Møteprotokoll

Bystyret

Møtested: Rådhuset, Munkegata 1, Bystyresalen

Møtedato: 26.09.2024 **Tid:** 13:00 - 18:00

Faste medlemmer som møtte:

Navn	Funksjon	Representerer
Kent Ranum	Ordfører	H
Berit Tiller	Medlem	H
Niklaus Haugrønning	Medlem	H
Ferhat Güven	Medlem	H
Olav Noteng	Medlem	H
Tone Dorthe Sletten	Medlem	H
Ove Vollan	Medlem	H
Nina Westad	Medlem	H
Radino Dizza Zulfi Mahendra	Medlem	H
Kjetil Utne	Medlem	H
Haakon Gussiaas	Medlem	H
Therese Bjørstad Karlsen	Medlem	H
Karl Erik Haug	Medlem	H
Michael Momyr	Medlem	H
Sindre Nilsskog	Medlem	H
Jørn Erik Berg	Medlem	H
Robert Flataas	Medlem	H
Emil Raaen	Medlem	AP
Sara Shafighi	Medlem	AP
Kirsti Tømmervold	Medlem	AP
Roar Aas	Medlem	AP
Sissel Trønsdal	Medlem	AP
Anita Børstad	Medlem	AP
Håkon Einarsve	Medlem	AP
Jørn Arve Flått	Medlem	AP
Sigurd Jan Ingvaldsen	Medlem	AP
Erling Eide Hustvedt	Medlem	AP
Edvin Helland	Medlem	AP
Karim Tahir	Medlem	AP
Gjermund Gorset	Medlem	AP
Maria Eriksen Storrø	Medlem	AP
Mona Berger	Medlem	SV
Efia Marie Damba	Medlem	SV
Silje Naper Salomonsen	Medlem	SV

Ottar Michelsen	Medlem	SV
Jenny Nordaune	Medlem	SV
Latifa Nasser	Medlem	SV
Nils Heldal	Medlem	SV
Annbjørg Horgar	Medlem	SV
Even Næss Bergseng	Medlem	SV
Elin Marie Andreassen	Medlem	FRP
Maria Alseth	Medlem	FRP
Jostein Eirik Gjermstad	Medlem	FRP
Jomar Andre Aftret	Medlem	FRP
Erling Moe	Varaordfører	V
Guro Holm Skillingstad	Medlem	V
Aurora Meland Winger	Medlem	MDG
Ola Lund Renolen	Medlem	MDG
Morten Kokaas	Medlem	PP
Solveig Sandsør	Medlem	PP
Roald Arentz	Medlem	R
Mia Småvik Rørdal	Medlem	R
Vegard Frøseth Fenes	Medlem	SP
Majen Helen Sævik	Medlem	KRF
Merete Letnes Ødegaard	Medlem	U

Varamedlemmer som møtte:

Navn	Funksjon	Representerer
Børre Lien		H
Terje Ekle		H
Jan Erik Engan		H
Knut Efskin		H
Thomas Sakshaug		MDG
Live Naomi Lubanda-Husby		AP
Kristin Tinmannsvik		AP
Hege Anette Rovik		AP
Magnus Gilje		V
Hanne Moe Reitan		V
Nora Malini Sætherø		MDG
Jonas Ali Werket Ghanizadeh		MDG
Lise Julianne Sandvik		PP
Arve Sletten		R

Forfall:

Navn	Funksjon	Representerer
Christianne Bauck-Larsen	Byråd	H
Ismail Elmi	Medlem	AP
Gro Eide	Medlem	H
Leon Bafondoko	Medlem	AP

Trond Grønli Åm	Byråd	V
Trude Basso	Medlem	AP
Jacob Brox	Medlem	H
Elisiv Hårstad Skjei	Byrådssekretær	V
Tore Dyrendahl	Byrådssekretær	MDG
Svein Otto Nilsen	Medlem	PP
Magni Fjørtoft Svarstad	Medlem	R

Fra administrasjonen møtte:

Navn	Stilling
Knut Ole Moen Bleke	rådgiver
Kåre Georgsen	sekretær
Merethe Baustad Ranum	byråd
Kristian Dahlberg Hauge	byrådsleder
Line Fjørstad	byråd
Trond Grønli Åm	byråd
Lucie Katrine Eidem	byråd
Lars Viko Gaupset	byråd
Christianne Bauck-Larssen	byråd
Kjetil Reinskou	byråd

67 medlemmer tilstede ved møtestart.

Meldt forfall ble godkjent.

Innkalling og sakliste ble godkjent.
Ola Lund Renolen (MDG) ble valgt til setteordfører under behandling av sak 169/24. Lund Renolen ble valgt mot 3 stemmer (3 R).

Følgende habilitetsvurderinger ble gjort:

Kent Ranum (H) vurderes som inhabil etter forvaltningslovens § 6 annet ledd i sak 129/24 Kommuneplanens arealdel 2022-2034, sluttbehandling. Ranum har opplyst om at flere av eiendommene han har eierskap i, via Kolvik Invest AS, påvirkes av forslag til ny KPA. Også Ranums nærmeste venn og forretningspartner har flere eiendommer (utover de som eies i felleskap med Ranum) som vil bli påvirket. I tillegg er det flere foreslåtte bestemmelser som vil ha konsekvenser for utvikling av flere av eiendommene. Borg Forvaltning AS, som Ranum er medeier av, har bistått flere kunder med innspill til rulleringen av KPA. Utfallet av KPA vil kunne gi positive eller negative økonomiske virkninger for Ranum selv, hans nære venn og forretningspartner, samt Borg Forvaltning AS og deres kunder. Dette er forhold som kan påvirke den objektive tilliten til Ranums upartiskhet. Hver enkelt tilknytning i seg selv begrunner nødvendigvis ikke inhabilitet i forhold til en så stor og overordnet plan som KPA, men etter en

totalvurdering anses Ranums samlede tilknytning til KPA som et særegent forhold som er egnet til å svekke den objektive tilliten til hans upartiskhet. Ranum er som kjent vurdert inhabil i KPA tidligere.

Niklaus Haugrønning (H) vurderes inhabil etter forvaltningslovens § 6 annet ledd i sak 169/24 Kommuneplanens arealdel 2022-2034, sluttbehandling. Haugrønning sitt tilknytningsforhold til saken er at han er deleier av Spongdalsveien 641 og denne eiendommen er spilt inn i forbindelse med rulleringen av KPA, benevnt som 920 Myrsund. I tilllegg er Haugrønning deleier og styreleder i Haugrønning Eiendom AS. Hele denne eiendommen er utleid til to andre firmaer i Nik Haugrønning Holding AS, Nik Haugrønning AS og PMH Norway AS. Eiendommen har akutt behov for tilleggsareal til sine virksomheter, primært tilleggsareal til nåværende tomt. Tilgang på tilleggsareal betinger etter det tidligere opplyste en endret arealplanstatus i KPA. Haugrønning oppgir selv å ha stor personlig interesse av en omdisponering til mer næringsareal. Denne direkte og sterke økonomiske interessen i utfallet av KPA må vurderes som en slik særlig tilknytning til saken, som klarligvis – avhengig av utfallet, vil medføre en særlig fordel eller tap for Haugrønning. Det synes heller ikke tvilsomt at tilknytningen kan være egnet til å svekke tilliten til hans objektive upartiskhet.

Berit Tiller (H) anses habil i sak 169/24 Kommuneplanens arealdel 2022-2034 - sluttbehandling. Tiller sitt tilknytningsforhold til saken er at hun var styreleder i TOBB fram til april 2015. Som styreleder var Tiller med på strategiske vurderinger om TOBB skulle kjøpe seg inn i deler av Overvik. Videre har Tiller opplyst at etter hun gikk ut av styret i 2015 så har hun ikke på noen måte vært involvert i selskapets virksomhet. Det er snart 10 år siden Tiller sluttet som styreleder og det er derfor svært vanskelig å se at tilknytningsforholdet ligger så nært i tid at det er nærliggende å tro at Tiller fortsatt identifiserer seg med TOBB sine interesser generelt eller på Overvik spesielt. Til sammenligning er det i NOU 2019:5 som omhandler forslag til ny forvaltningslov foreslått å konkretisere dette med en karenstid på ett år etter opphørt engasjement i ledende stilling eller verv i styrende organ. I tillegg må det også sees hen til sakens karakter - det skal en god del til for å statuere inhabilitet i en stor overordnet sak som KPA, spesielt når det ikke er noen indikasjoner på at Tiller, utover det alminnelige, har noen direkte personlige økonomiske interesser i utfallet av behandling av KPA. Tillers tilknytning til TOBB i dag er for avledet til å kunne karakteriseres som et særegent inhabiliserende forhold.

Saksliste

Sak	Tittel
PS 169/24	Kommuneplanens arealdel 2022-2034 - Sluttbehandling
PS 170/24	Årsrapport 2023 - Ombud for helse, omsorg og oppvekst
PS 171/24	Retningslinjer for forfall
PS 172/24	Representantforslag - Innføre en sømløs og vedtaksfri "omsorgstrapp" for personer med ALS - Tone Dorthe Sletten (H)
PS 173/24	Fritakssøknad og oppnevninger for Høyre
FO 45/24	Muntlige spørsmål bystyret 26.09.2024
FO 46/24	Medlemsforslag - Base for hjemmetjeneste ved Vår Frue Menighets Omsorgsboliger - Maria Alseth (FrP)
FO 47/24	Medlemsforslag - Innkjøpsstopp for Tesla så lenge arbeidskonflikt pågår - Roald Arentz (R)
FO 48/24	Medlemsforslag - Samarbeid for å etablere hjelpetiltak for etterlatte ved overdose - og andre rusrelaterte dødsfall - Mona Berger (SV)
FO 49/24	Medlemsforslag - Heve bompengesatsen for nye fossilbiler fra 2025 - Jenny Nordaune (SV) og Even Næss Bergseng (SV)
FO 50/24	Medlemsforslag - egne avdelinger for åndsfriske på sykehjem - Lise Julianne Sandvik (PP)
FO 51/24	Medlemsforslag - Språkpolitisk plan i Trondheim kommune - Annbjørg Horgar (SV)
FO 52/24	Medlemsforslag - Flere skolehager i Trondheim - Vegard Frøseth Fenes (SP)
FO 53/24	Interpellasjon - Interpellasjon om likeverdige helsetjenester - Annbjørg Horgar (SV)
PS 174/24	Valg til politiske organer etter innføring av parlamentarisme - settevalg og nyvalg
PS 175/24	Valg av forliksrådsmedlemmer og møtefullmektiger for forliksrådet for perioden 01.01.2025 - 31.12.2028
PS 176/24	Stavne Arbeid Trondheim KF og Stavne Inkludering Trondheim KF - styret - valg av settemedlem
PS 177/24	Trondheim symfoniorkester & opera - oppnevning til valgkomite
PS 178/24	Navneendring for Rådet for personer med funksjonsnedsettelser

PS 169/2024 Kommuneplanens arealdel 2022-2034 - Sluttbehandling

Bystyrets behandling i møte den 26.09.2024:

Vedtak:

1. Bystyret vedtar forslag til ny kommuneplanens arealdel 2022-2034 som vist på kart i målestokk 1:40 000, senest datert 07.05.2024, unntatt 911 Øvre Rotvoll Sør og 912 Øvre Rotvoll (trekanten)

og områdene som er omfattet av bystyrets øvrige vedtakspunkter i saken.

2. Bystyret vedtar bestemmelser senest datert 07.05.2024 og beskrevet i planbeskrivelsen, senest datert 07.05.2024, med de endringer som følger av bystyrets vedtak.

3. Bystyret vedtar endringer i forslaget til KPA 2022-2034 som vist i vedlagte PDF.

4. Saksdokumentene til kommuneplanens arealdel 2022-2034 skal korrigeres slik det framgår av Tilleggsnotat 11 - Korrigeringer av Kommunedirektørens forslag til sluttbehandling, datert 06.06.2024.

5. Arealdelen vedtas med rettsvirkning ved Bystyrets vedtak, jf. plan- og bygningsloven § 11-6. Dette med unntak av de avgrensede utbyggingsområdene som det er knyttet innsigelser til, jf. plan- og bygningsloven § 11-16. Disse tas opp til mekling og eventuell videre behandling hos Kommunal- og distriktsdepartementet, jf. plan- og bygningsloven § 5-6.

6. Lianvatnet skole/Haukåsen (126) beholder formål som foreslått i kommunedirektørens innstilling. Byrådet bes sørge for at utarbeidelse av ny reguleringsplan som vil gjelde foran KPA 2022-2034 legges inn i kommunens planstrategi.

Vedtaket fattes i henhold til plan- og bygningsloven § 11-15.

Areal
Område 864 og deler av 5 Tilbakeføre Tillermarka til LNF
Markagrensa (rød strek) vest i Tillermarka justeres i henhold til markagrensa i kommuneplanens arealdel 2007-2012, unntatt areal regulert til bebyggelse og anlegg i reguleringsplan for Torgårdsvegen (planID r20150033). Arealet avsettes til landbruk, natur og friluftsformål (LNFR). Hensynssone for naturtypen ravinelandskap i Tillermarka pprettholdes. Kart endres i tråd med dette.

Område 9/933 Fossegrenda
Område 9/933 Fossegrenda får fremtidig kombinert bebyggelse og anlegg KB5 som formål.

Område 28 Valkyrjeveien 7
Område 28 Valkyrjeveien 7 får byggesone 2 som formål.

Område 35 Leirfossveien (Fossegrenda)
Område 35 Leirfossvegen får næringsbebyggelse som formål.

Område 41 Røddevegen
Område 41 Røddevegen får næringsbebyggelse som formål.

Område 50 Bratsbergvegen 139
Del av område 50 Bratsbergvegen 139 og dagens næringsbebyggelse får næringsbebyggelse som formål, som vist i kartutsnittet under.

Område 51 Sandmoen
Område 51 Sandmoen får næringsbebyggelse og overnatting som formål

Område 55 Innherredsveien
Område 55 Innherredsveien får byggesone 3 som formål.

Område 57 Selsbakk
Areal avsatt til blå/grønnstruktur endres til byggesone 3 i tråd med kartutsnitt i kommunedirektørens tilleggsnotat 9.

Område 93 Heimdalsvegen
Område 93 får to arealformål: Del som er dyrka mark i dag får LNFR som foreslått til sluttbehandling. Resterende del får næringsbebyggelse som formål. Avgrensning for næringsareal vises i kartutsnittet under.

Område 106/58 Flatåsen
Deler av område 58 som er foreslått til næringsbebyggelse endres til byggesone 2. Område 106 som ikke overlapper 58 settes av til fremtidig næringsbebyggelse, jfr vedlagte illustrasjon.

Område 124 Gamle Ladejarlen
Område 124 Gamle Ladejarlen får byggesone 2 som formål. For den delen av området som grenser til blågrønn struktur skal hensynssonen ikke overlappe byggesonen.

Område 127 Moksneslia
Område 127 Moksneslia får formål byggesone 3.

Område 142 Eklestrøa
Fordeling av formål gjennomføres som i hovedhøringen. Byggeområdene holdes utenfor forbudsgrense vassdrag Nidelvkorridoren.

Område 315 Porsmyra
Foreslått endring til fremtidig offentlig tjenesteyting gjennomføres ikke, formål settes til blå/grønnstruktur i tråd med KPA 2012-2024.
Område 320 Fjellseterveien - Offentlig tjenesteyting/barnehage
Formål offentlig tjenesteyting erstattes med blå/grønnstruktur og byggesone 1 S4 med fordeling som i KPA 2012-2024

Område 320 Fjellseterveien - Offentlig tjenesteyting/barnehage
Formål offentlig tjenesteyting erstattes med blå/grønnstruktur og byggesone 1 S4 med fordeling som i KPA 2012-2024

Område 331 - Offentlig tjenesteyting/skole Blyberget
Offentlig tjenesteyting/skole Blyberget tas ut, og formål settes til LNFR. Rød strek beholdes som i KPA 2012-2024.

Område 352 Offentlig tjenesteyting/barnehage Østmarka
Offentlig tjenesteyting/barnehage Østmarka tas ut, og formål settes til LNFR.

Område 404 Tiller sør
Område 404 Tiller sør får formål byggesone 1 S2, i tråd med KPA 2012-2024.

Område 920 Myrsundet
Område 920 Myrsundet får framtidig næringsbebyggelse som formål, jf. kartutsnitt under.

Område 921 Offentlig tjenesteyting/HVS Wullumsgården

Offentlig tjenesteyting (Helse- og velferdssenter) Wullumsgården tas ut, og formål settes til LNFR. Rød strek beholdes som i KPA 2012-2024. HVS kan bygges ut som en del av byggesone 1 og byggesone 2 sør for Fjellseterveien

Område 924 Berg prestegård
Deler av område 924 Berg prestegård får byggesone 2 som formål, jf. kartutsnitt under.

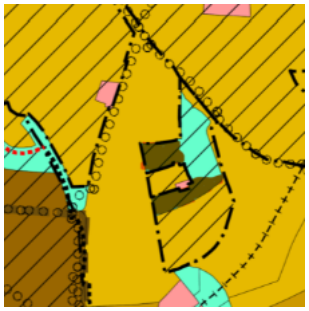

Område 937 Østmarka
Område 937 Østmarka får formål blå/grønnstruktur.

Område 941 Ranheimsvegen 305
Område 941 Ranheimsvegen 305 får byggesone 4 som formål

Område 945 Brøsetekra 5, 7, 11
Område 945 Brøsetekra får byggesone 2 som formål.

Område 950 NGU-tomta på Østmarka, gnr/bnr 413/21
Område 950 NGU-tomta på Østmarka, gnr/bnr 413/21, får formål offentlig tjenesteyting.

Område 956 Universitetsområdet Dragvoll
De deler av område 956 som har byggesone 3 som formål endres til formål framtidig næringsbebyggelse. Områdene som er avsatt til idrettsanlegg endres ikke, inkludert område 208 og 209 på søndre og nordre parkeringsplass

Båndleggingssoner i påvente av detaljregulering tas ut
Båndleggingssonene H710_1 (Østmarka) og H710_2 (Øvre Rotvoll og Presthus) tas ut av kartet, og tilhørende bestemmelser 30.2 og 30.3 strykes

Nytt bestemmelsesområde for bynaturpark
Det opprettes et nytt bestemmelsesområde § 32.10 Bestemmelsesområde #12, Bynaturpark

Bestemmelsesområdet legges til i kartet i tråd med kartet som var ute på høring, og som vist i kartutsnittet under.

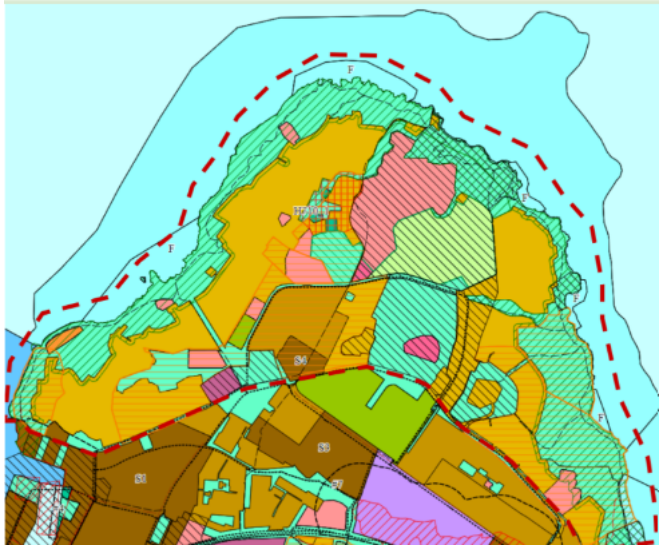

Innbyggernes bro
Innbyggernes bro tas ut av plankartet, jf. vedtak i sak 165/24 Videre arbeid med Innbyggernes bro i formannskapet 22.05.2024.

Bestemmelser
For bestemmelser som ikke er nevnt under, gjelder kommunedirektørens forslag til bestemmelser, senest datert 07.05.2024.

§ 1 Formål
Kommuneplanens arealdel skal følge opp byutviklingsstrategien, for å sikre en attraktiv og næringsvennlig kommune, tilstrekkelig tilvekst av nye boliger og gode vilkår for landbruket i kommunen. Kommuneplanens arealdel skal bygge opp under kommuneplanens samfunnsdel 2020-2032, Trondheimsløftet, og bygger på følgende hovedgrep:
- ivaretakelse av den private eiendomsretten
- holde bystrukturen samlet
- bevare områder for landbruk, natur og friluftsliv, og sikre en arealnøytral byutvikling
- differensiere tetthet og sikre variert boligbebyggelse med attraktive bolig- og bymiljø
- sikre rett virksomhet på rett sted, og nok næringsareal av ulik størrelse.
- legge til rette for et klima- og miljøvennlig transportmønster
- utvikle lokalsentre som reduserer transportbehovet
- legge føringer for klima- og miljøvennlige byggeprosjekt

§ 2.1 Forholdet til kommunedelplaner
Følgende kommunedelplaner går ved motstrid foran kommuneplanens arealdel:
- kommunedelplan for Sluppen, vedtatt 02.02.2023, med unntak av i områder i Nidelvkorridoren og områdene avsatt til næringsbebyggelse i kommunedelplanen.
- kommunedelplan for Klett, vedtatt 19.10.2023.
- Kommunedelplan for Nyhavna, vedtatt 16.06.2016, med unntak av bestemmelsesområde #1 Kaibasert næring, #2 Byøkologisk forsøksområde, #3 Mobilitetsfunksjoner og #4 Sjøbad strandveikaia, og areal til framtidig blå/grønnstruktur, idrettsanlegg og tjenesteyting. Krav til antall parkeringsplasser skal følge kommuneplanens arealdel.

§ 6.1 Byggegrense mot sjø - Trondheimsfjorden
Tiltak etter PBL § 1-6 første ledd utenom fasadeendringer kan ikke settes i verk nærmere strandlinjen, målt i horisontalplanet ved alminnelig høyvann, enn:
- Byggesone 1 og naust: 0 meter

- Byggesone 2-4 og øvrige byggeformål: 25 meter
- LNFR: 100 meter

Friluftslivstiltak kan tillates dersom viktige økologiske funksjoner blir opprettholdt. Det samme gjelder tiltak for å fremme naturmangfoldet, og tiltak som har til hensikt å reetablere historiske funksjoner.

§ 6.2 Byggegrense mot vassdrag og innsjøer

Langs Gaula og Vikelva er tiltak etter pbl § 20-1 a, d, j, k og l ikke tillatt inntil 100 meter fra normal strandlinje. Nødvendige tiltak for drift, vedlikehold og fornying av eksisterende teknisk infrastruktur, veg og bane kan tillates.

Langs alle vassdrag med årssikker vannføring, inklusive elver, bekker, vann og tjern, gjelder byggegrense på minimum 10 meter på hver side av vassdraget innenfor byggeområder og minimum 50-meter innenfor LNFR-områder. Dette gjelder både åpne og lukkede vassdrag.
Ved gjenåpning av tidligere lukkede bekker kan det tillates mindre avstandskrav ved detaljregulering.

§ 7.2 Universell utforming

Alle planforslag skal redegjøre for universell utforming i planområdet og i sammenheng med omgivelsene. Der det kan oppstå konflikt mellom ulike hensyn skal planarbeidet avveie alternative løsninger basert på prinsippet om inkludering og likeverd og hensynet til universell utforming skal veie tungt.

Uttalelser fra kommunalt råd for personer med funksjonsnedsettelser, samt berørte organisasjoner, brukes som dokumentasjon i saker som omhandler universell utforming.

§ 8.4 Overordnede strukturer

Viktige landskapstrekk, siktlinjer og landemerker, offentlige gater og byrom, blågrønne strukturer og offentlig tilgang til sjø og vassdrag skal være premissgivende for bystrukturen.

Byens viktigste landskapstrekk er høydedragene som omkranser byen, strandsonen, elve- og bekkedalene, jordbrukslandskapet, sammenhengende grøntdrag og markante trær.

Eksempel på viktige siktlinjer er mellom Gløshaugen-Studentersamfundet-Nidarosdomen.

§ 8.5 Høyhus

Trondheim skal ikke utvikles til en høyhusby.
Tempe, Rosten og Sluppen har etablerte høyhusområder.
Høyhus er her bygg over 10 etasjer, eller over 3 etasjer høyere enn omkringliggende bebyggelse.

§ 8.6 Svalganger

Svalganger og rømningstrapper skal ha høy arkitektonisk kvalitet og være godt tilpasset fasaden med en bredde som tillater gode overganger og en privat sone mellom boligens yttervegg og offentlig sone/kommunikasjonsvei.

§ 9.2 Antikvarisk verdifull bebyggelse - klasse A, B og C

Bebyggelse i klasse A og B skal i størst mulig grad etterstrebes bevart i sin helhet, og ikke vesentlig endres. Ved forfall tillates kun gjenoppføring til byggets tidligere eller opprinnelige volum og uttrykk.

Bebyggelse i klasse C skal søkes bevart. Ved tiltak som endrer bygningens uttrykk skal både antikvarisk verdi og funksjonalitet vektlegges.

Med vesentlig endring forstås svekking av bygningens utvendige antikvariske verdi. Med "eldre" menes bygningsdeler fra byggeår, og der disse ikke finnes menes bygningsdeler fra før 1940. Ved tilbakeføring av bebyggelsen skal dokumentasjon av opprinnelig/tidligere situasjon foreligge.

Antikvarisk verdi forstås som historisk, arkitektonisk eller annen kulturhistorisk verdi. Klassifisering fremgår av kulturminnekartet i Trondheim kommunes innsynsløsning.

§9.3 Hensynssoner kulturmiljø
Her skal det tas særlige hensyn ved utarbeiding av planforslag og ved søknad om tiltak etter pbl § 20-1. Tiltak skal fremme vern av kulturminnet eller kulturmiljøet. Den kulturhistoriske bebyggelsens egenart og kulturmiljøets særpreg skal sikres og opprettholdes.

Hensynssonens strøkskarakter bør være retningsgivende for byggehøyder, volum, utforming, materialbruk og farger. Estetikk, kvalitet, bevaring av store trær og andre grønne kvaliteter bør vektlegges.

Retningslinjer for de ulike hensynssonene er også angitt i vedlegg til arealdelen Kulturmiljø og antikvarisk bebyggelse og er retningsgivende ved utforming av nye planer og tiltak.

Ved nye tiltak innenfor eller nær hensynssonene kan kommunen kreve at kulturmiljøet/landskapet dokumenteres og at det redegjøres for hvordan tiltaket ivaretar og foredler områdets kulturhistoriske verdier.

§ 10.2 Kvaliteter ved boenhetene
Ensidig belyste boenheter utenfor byggesone 1, må ha stue eller privat uteoppholdsplass inntil stue med sol 21. april i minst tre timer etter kl 12.

Alle boliger skal oppfylle minst to av kvalitetene under, men i S1 holder ett.
- soverom eller stue mot stille side, ikke dempet fasade
- stue, eller privat veranda/balkong inntil stue, med sol i minst tre timer 21. april
- boenheter over 30 m2 og med minst ett soverom i tillegg til stue

Alle boenheter utenfor S1 skal være minst 30 m2.

Alle boenheter bør samtidig minst oppfylle halvparten av følgende kvalitetskriterier:
- gjennomgående boenhet eller hjørneleilighet
- størrelse over 40 m2
- utsikt fra stue/hovedoppholdsrom direkte mot landskap/større park /grøntområde
- tilgang til privat eller felles uteoppholdsareal på bakken
- beliggenhet utenfor rød støysone
- beliggenhet utenfor rød og gul støysone

§ 10.3 Fellesarealer innendørs

Ved planforslag med 20 boliger eller mer skal det sikres etablering av et samlet innendørs felles oppholdsareal.

Retningslinjer for innendørs fellesarealer:
- for 20-50 boenheter: minimum 30 m2
- for 50-100 boenheter: minimum 50 m2
- for over 100 boenheter: minimum 75 m2, pluss 0,5 m2 per boenhet over 100 boenheter

Fellesarealet bør ligge i første etasje og ha direkte kontakt med gaterommet og hovedadkomst til boligene.

§ 12.1 Overvannshåndtering
Planforslag og søknad om tiltak skal identifisere, dimensjonere og sikre arealer for overvannshåndtering og flomveger i tre trinn i tråd med Trondheim kommunes VA-norm og sanitærreglement.

Overvann skal søkes utnyttet som positivt element i bymiljøet og styrke lokalt naturmangfold. Andre løsninger må begrunnes. Utfyllende beskrivelse av overvannshåndtering i tre trinn er gitt i Trondheim kommunes VA-norm.

I "Middelalderbyen" skal overvannshåndtering planlegges i samråd med arkeologisk fagmiljø/Riksantikvaren

§ 13.1 Generelt
Transportsystemet skal bidra til en attraktiv by, at flere går, sykler og reiser kollektivt og at viktige samfunnsfunksjoner har nødvendig fremkommelighet. Bystrukturen skal planlegges slik at byens gater og byrom gir et attraktivt og finmasket gangnett som gir kort adkomst til viktige målpunkt.

Ved planlegging av nye samferdselsanlegg skal etablering av allé eller trær vurderes.

F*or eksisterende alleer og trerekker bør trær og tilstrekkelig rotsone bevares. Allétrær som fjernes bør erstattes.*

Fortau bør opparbeides med minst 2,5 meter asfaltert bredde og reguleres med 3 meter bredde for å inkludere skulderareal. I private blindveger uten gjennomgang kan 1,5 meter asfaltert bredde aksepteres hvis de betjener færre enn 50 boenheter.

§ 13.2 Innenfor tettstedene
Samferdselsanlegg innenfor byggesone 1-3 og ellers innenfor tettstedene skal utformes som gater for lav fart og med areal til blågrønne kvaliteter. Unntak er fjernveger og skinnegående transport.

Tilrettelegging for kryssing for fotgjengere skal være på bakkeplan, unntatt over fjernveg. Annen løsning kan vurderes der alternativet i større grad oppfyller målet om at flere går, sykler og reiser kollektivt. Planskilte kryss kan vurderes som et tillegg der dette er nødvendig for å sikre trygg skoleveg.

§ 13.4 Mobilitetsutredning
I planforslag skal det redegjøres for hvordan planforslaget vil bidra til at flere går, sykler og reiser kollektivt. Nødvendige tiltak i mobilitetsutredningen skal sikres i reguleringsplanen.

Mobilitetsutredningen bør vise:
1. Forventet transportbehov: reiser til/fra bolig/virksomhet, besøksreiser, varelevering, godstransport.
2. Tilbud for gående, syklende, kollektivtrafikk og kjørende.
3. Trafikksikkerhet og fremkommelighet for gående, syklende, kollektivtrafikk og utrykningskjøretøy
4. Tiltak for å bedre tilgjengeligheten for gående, syklende og kollektivreisende og hvordan tiltakene bidrar til å nå målet om 20 prosents reduksjon i personbiltransport.

5. Parkeringstilbud for bil og sykkel, herunder plassering, utforming og ladeinfrastruktur. Det bør illustreres hvordan antall plasser er tenkt fordelt på personer med nedsatt funksjonsevne, beboere, besøkende, kunder, tjenesteytere og delebiler. Det bør også fremkomme om parkering kan samlokaliseres med andre boligfelt eller virksomheter i området.
6. Behov for regulering av offentlige gater i det aktuelle influensområdet for å begrense parkering utenfor eiendom.
7. Løsninger for renovasjon og varelevering.
8. For planlagt ny næringsbebyggelse skal det også foreligge en vurdering av om lokaliseringen er i samsvar med målsettingen om rett virksomhet på rett sted (§ 18).

§ 13.9 Turveg
Turveger vist i byggeområder kan reguleres til og utformes som gangveg. Alle reguleringsplaner skal redegjøre for nærhet til turveger.

§ 14.1 Antall parkeringsplasser for boligbebyggelse
Det skal avsettes plass for biler og sykler i samsvar med norm som angitt i vedlagte tabell.

Avrundingsregel: minimumskrav rundes opp og maksiumumskrav rundes ned til nærmeste hele tall.

§ 14.4 Bilparkeringsplasser for besøkende og nyttekjøretøy
I tillegg til parkeringsplasser etablert etter § 14.1 og § 14.2, skal det etableres bilparkeringsplasser for besøkende og nyttekjøretøy.

Antall parkeringsplasser skal vurderes og fastsettes i den enkelte reguleringsplan. Det skal alltid sikres minst 1 parkeringsplass.

Kravet gjelder ikke for frittliggende eneboliger og tomannsboliger, eller for kontor i felt S1. Kravet kan frafalles dersom det er tilstrekkelig tilgang på offentlige plasser i nærheten.

§ 14.5.1 Plassering
Plassering av parkeringsplasser skal vurderes og fastsettes i den enkelte reguleringsplan eller byggesak. Felles parkeringsanlegg skal som hovedregel anlegges ved kjøreadkomst fra veg.

Ved anleggelse av flere enn åtte parkeringsplasser, bør det vurderes å samle disse i felles parkeringsanlegg.

§ 14.6 Plassering og utforming av sykkelparkering

Sykkelparkering skal plasseres nær hovedinnganger. Det skal legges stor vekt på brukbarhet, tilgjengelighet og trygghet ved utforming.

Der normen gir krav om minst 10 sykkelparkeringsplasser bør:
- minst 50 prosent være innvendig i bygg eller ha overbygg, men etableres i tillegg til annet bodareal
- minst 15 prosent være for sykkelvogner og lastesykler, og være minst 1 m x 2,6 m - det for virksomheter være garderobe med dusjfasiliteter for ansatte

Der normen gir krav om minst 100 sykkelparkeringsplasser bør det avsettes areal til vask og enkel service.

Parkering for sykkel i kjeller bør legges i første parkeringsplan, og det bør sikres adkomst via

rampe eller bilheis/spesialheis dimensjonert for sykkelvogner og lastesykler. Andel sykkelparkeringsplasser i to-etasjes stativ bør begrenses.

Parkeringsareal for normale sykler bør være minst 0,75 m2 pr. plass, med låsefunksjon mot sykkelramme.

§ 15.4 Fjernvarme
Ved utbygging eller ved hovedombygging med samlet areal over 1000 m2 BRA innenfor gjeldende konsesjonsområde for fjernvarme skal bebyggelsen tilknyttes fjernvarmeanlegg. Tilknytningsplikten gjelder også for mindre bruksareal innenfor konsesjonsområdet dersom arealet er en del av et framtidig større utbyggingsprosjekt.

Det kan kun fritas for tilknytningsplikt til fjernvarme hvis det dokumenteres at klimagassutslippene ved andre energiløsninger er lavere og belastningen på el-nettet blir akseptabel. Nødvendig anleggsarbeid for å etablere løsningene skal inkluderes i klimagassberegningen.

Akseptabel belastning på el-nettet tilsier at varmeløsningen ved dimensjonerende utetemperatur ikke belaster el-nettet vesentlig mer enn tilsvarende bygg som tilfredsstiller gjeldende byggteknisk forskrift og som benytter fjernvarme som primærvarmekilde.

§ 17.3 Næringsavfall
I byggesone 1 og 2 skal næringsavfall løses innomhus.

I øvrige byggeområder skal næringsavfall løses på egen grunn og fortrinnsvis innomhus. Utomhus bør det tilstrebes nedgravde oppsamlingsløsninger.

I byggesone 1 og 2 bør det vurderes om næringsarealer kan ha felles renovasjonsløsning med husholdninger i samme bygg eller på nærliggende tomt.

§ 17.4 Offentlig returpunkt og ombrukssentral
Ved planlegging og oppføring av nye bygg på over 1000 m2 BRA i byggesone 1, 2 eller 3 må det avklares om det skal sikres areal til offentlige returpunkt for renovasjon.

Ved utarbeiding av områdeplaner i byggesone 1 og 2 skal areal til ombrukssentral vurderes.

§ 18.1 Lokalisering av virksomheter
Virksomheter skal lokaliseres etter prinsippet rett virksomhet på rett sted. Støyende virksomheter og virksomheter med sikkerhetssoner skal etableres med god avstand fra boliger eller andre følsomme formål.

Prinsippet rett virksomhet på rett sted er illustrert i temakart, og innebærer:
- Arbeidsplassintensive virksomheter, som kontor, skal lokaliseres langs kollektivbuen mellom Sluppen og Strindheim, i tilknytning til kollektivknutepunktene Heimdal, Tiller og Strindheim, eller i større lokale sentrumskjerner (felt S3), eller i andre områder der kollektivdekningen er/kan bli tilfredsstillende i løpet av planperioden. I disse områdene skal arbeidsplassintensive virksomheter kun etableres innenfor byggesone 1, byggesone 2 eller fra andre etasje og opp innenfor formålet næringsbebyggelse. Arbeidsplassintensive virksomheter kan også lokaliseres innenfor formålet næringsbebyggelse på Tunga fra andre etasje og opp.
- Publikumsrettede virksomheter, som handel, tjenesteyting og andre kultur- og servicetilbud som har kommunen eller regionen som omland, skal lokaliseres i byggesone 1 - S1, på Midtbyhalvøya.

Små publikumsrettede virksomheter med lokalt nedslagsfelt skal kun tillates i byggesone 1, og på inntil 400 m2 BRA i byggesone 2.
- Hotell skal kun tillates innenfor Midtbyen og sentrumsområdene rundt (felt S1) og i de største knutepunktene (felt S2).
- Forretninger generelt skal lokaliseres i byggesone 1. Dagligvareforretninger på inntil 2 000 m2 BRA kan vurderes tillatt i byggesone 2 og 3 gjennom detaljreguleringsplan. Forretninger for plasskrevende varer kan vurderes tillatt gjennom reguleringsplan innenfor arealer avsatt til næringsbebyggelse merket NF på Tiller. BRA for handel defineres som summen av salgsflate, lagerlokale, spiserom/kantine og kontorareal som er nødvendig for driften. Areal til parkering og varelevering inngår ikke.
- Næringsvirksomheter med få besøkende, som bygg- og anleggsvirksomheter, håndverkere, teknologi og produksjonsvirksomheter, skal lokaliseres innenfor formålet næringsbebyggelse, eller innenfor byggesone 1-3. Virksomheter som ikke kan tilpasses bystrukturen eller fører til vesentlig støy- og trafikkbelastning for omgivelsene bør ikke lokaliseres i byggesone 1-3.
- Arealkrevende næringsvirksomheter med behov for nærhet til hovedvegnettet skal fortrinnsvis lokaliseres innenfor formålet næringsbebyggelse i felt merket NA.

Ved arbeidsintensiv virksomhet/kontorformål bør det settes av areal til uteoppholdsareal for ansatte.

§ 19.2 Støyutredning
Støy fra veg, bane, havnevirksomhet, helikopter og industri skal utredes ved etablering av støyfølsomme formål. For veg, bane og helikopter skal støykart i kommunens kartløsning legges til grunn for vurdering av behovet for støyutredning.

§ 19.5 Stille områder og grønnstruktur
I og i nærheten av stille områder vist i Temakart støysone veg og stille områder og formålet blå/grønnstruktur, skal det dokumenteres ved planlegging og søknad at tiltak ikke medfører en økning av støynivået i disse områdene.

Lydpåvirkning (Lden) fra vegtrafikk, bane, trikk, helikopter, havne- og industrivirksomhet bør holdes under 55 dBA for grønnstruktur generelt og under 50 dBA for stille områder. Ved flere støykilder bør sumstøy vurderes. For andre støykilder brukes grenseverdier i T-1442. Støynivå fra tekniske installasjoner bør tilfredsstille samme krav som stilles til lydnivå ved boligfasade.

§ 22 Plan for bygge- og anleggsfasen
Plan for beskyttelse av omgivelsene i bygge- og anleggsfasen skal foreligge før arbeidet kan igangsettes.Nødvendige beskyttelsestiltak skal være etablert før bygge- og anleggsarbeider kan igangsettes. I bygge- og anleggsfasen skal det være god framkommelighet, trafikksikkerhet og orienterbarhet for gående, syklende og kollektivtransport.

Planen bør redegjøre for trafikkavvikling, massetransport, driftstider, støyforhold, rystelser og vibrasjoner, ivaretakelse av terreng og verdifull vegetasjon, renhold og støvdemping, framkommelighet og trafikksikkerhet for gående, syklende og kollektivtransport, håndtering av avrenning for å ivareta hensyn til vannmiljø og avløpsnett samt tiltak for å redusere klimagassutslipp. Lange omveier for gående og syklende bør unngås.

Tiltakshaver er ansvarlig for at planen foreligger, at planen er tilgjengelig på bygge-/anleggsplassen og at den er kjent for foretakene som utfører arbeid. Det bør vises hvordan kravene i §§ 15.4, 19.6 og 20.2 tilfredsstilles og dokumenteres i bygge-og anleggsfasen. Ved større prosjekter bør planen revideres. Ved flere utbygginger i samme område bør tiltakene samordnes.

§ 23.1 Felles formålsbestemmelser byggesone 1-4:
Byggesone 1 og 2 utgjør tilsammen de mest sentrale byområdene i kommunen, hvor det skal legges til rette for at hovedandelen av nye boliger lokaliseres.

Arbeidsplassintensive virksomheter skal lokaliseres i byggesone 1 og 2 langs kollektivbuen og ved de store knutepunktene.

Byggesone 1 skal utvikles med et mangfold av publikumsfunksjoner tilpasset stedets omland, og et aktivt og levende bymiljø.

Byggesone 2 og 3 skal videreutvikles som områder for boliger med innslag av næring, og nødvendig areal til tjenesteyting og idrett. Virksomheter med mange besøkende, eller som ikke kan tilpasses bystrukturen eller gir vesentlig belastning på tilliggende vegnett, bymiljø og bomiljøer tillates normalt ikke.

Byggesone 4 skal utvikles i tråd med omgivelsene, og antall nye boliger skal begrenses.

Ved regulering kan justeringer av grensene mellom byggesonene vurderes etter en stedsanalyse. Dette for å sikre bedre utnyttelse av arealer innenfor byggesonene og bedre tilpasning til etablert gate- og bebyggelsesstruktur, samt hensynta naturlige terrengavgrensninger, viktige natur- og kulturhistoriske verdier eller fjernvirkning i landskapet.

For alle planforslag skal det tidlig i planprosessen avklares behov for å innpasse areal til nye, eller utvidelse av eksisterende, offentlige funksjoner eller annen nødvendig infrastruktur.

Dagligvarehandel skal lokaliseres i tilknytning til bydelens gang- og sykkelnett og nært godt kollektivtilbud.

Alle byggesonene skal utvikles på en måte som bidrar til å skape en inkluderende by, der bymiljø og møteplasser er tilgjengelige og åpne for alle.

§ 23.2 Felles bestemmelser byggesone 1 og 2
Områdene skal utvikles etter bymessige prinsipper, med høy tetthet og kvalitet, og sammenhengende byromsnettverk.

Ny bebyggelse skal utformes og plasseres slik at den ikke er til hinder for at omkringliggende eiendommer kan utvikles med tilsvarende tetthet og kvalitet, der hvor dette kan være aktuelt.

Langs fasader som henvender seg mot hovedgater og offentlige byrom skal det vurderes etablert utendørs møbleringssone som muliggjør tilrettelegging for utendørs byliv.

Første etasje, herunder areal på bakkeplan trukket inn under tak, ut mot sentrale offentlige gater, gangveger og byrom bør ikke inneholde parkeringsanlegg, boder og lager, samt større rom for tekniske anlegg.

Stopp for tjeneste- og varelevering og renovasjonsbiler skal fortrinnsvis etableres i forbindelse med møbleringssone langs sidegater.

Det skal tilstrebes et finmasket gangnett. Ved planlegging av ny bebyggelsesstruktur bør kvartaler ha maksimal bredde/lengde på 70 meter, og fasadene underdeles med sprang i fasadeliv og variert material- og fargebruk minst hver 30 meter. Føresteetasjer ut mot sentrale offentlige gater,

gangveger og byrom bør ligge på samme nivå som gateplan for å muliggjøre innganger fra gata. Felles oppholdsrom for flere boenheter, kantiner eller lignende skal fortrinnsvis plasseres her. Som en mindre del av møbleringsarealet langs gater kan det etableres langsgående offentlig korttidsparkering for besøkende, HC
parkering og taxi.

§ 23.3.3 Utforming av bystruktur og bebyggelse:
Sentrumsstrategien og Gatebruksplan for Midtbyen skal legges til grunn som stedsanalyse for planforslag i byggesone 1, felt S1 Midtbyen og Trondheim sentrum.

For planforslag i sentrumskjerner felt S2-5 skal det utarbeides stedsanalyse.

Mot torg og sentrale gaterom/strøk skal fasader i første etasje ha et åpent uttrykk og en stor andel vinduer, samt dører med direkte adkomst fra gateplan.

Arealene i etasje på gateplan bør være fleksible for ulike typer virksomheter og enhetsinndeling. Takhøyde bør være minimum 4,5 meter brutto. Vinduer bør ikke dekkes med folie eller lignende.

§ 23.4.2 Arealbruk
a. Innenfor byggesone 2 tillates kun følgende formål: boligbebyggelse, offentlig tjenesteyting, privat tjenesteyting inntil 400 m2 BRA, idrettsanlegg, næringsbebyggelse.
b. Forretning tilknyttet næringsvirksomheter tillates på inntil 25 % av virksomhetens BRA.
c. I eksisterende bebyggelse av antikvarisk verdi klasse A-C tillates også tjenesteyting som kan bidra til at bebyggelsen fortsatt kan være i bruk.

Forretningsformål bør være knyttet til service- og håndverksvirksomheter.

§ 23.5.2 Arealbruk
a. Innenfor byggesone 3 tillates kun følgende formål: boligbebyggelse, offentlig tjenesteyting, idrettsanlegg, og næringsbebyggelse.
b. Forretning tilknyttet næringsvirksomheter tillates på inntil 25 % av virksomhetens BRA.
c. I eksisterende bebyggelse av antikvarisk verdi klasse A-C tillates også tjenesteyting som kan bidra til at bebyggelsen fortsatt kan være i bruk.

Forretningsformål bør være knyttet til service- og håndverksvirksomheter.

§ 24.1.1 Generelle bestemmelser
Det må foreligge godkjent avløpsløsning med felles ledningsnett knyttet til kommunalt nett eller eget renseanlegg før igangsettingstillatelse kan gis.

Fritidsbebyggelse skal tilpasses tomtearealet, og bør ha maksimalt 120 m2 BRA for hovedbygg.

§ 24.4.1 Innhold

Innenfor formålet kan det etableres næringsvirksomheter i tråd med prinsippet for rett virksomhet på rett sted. Energianlegg tillates. Ved søknad om tiltak gjelder formål angitt i vedtatt reguleringsplan foran formål angitt i arealdelen dersom motstrid.

Innenfor arealer avsatt til næringsbebyggelse bør det kun tillates håndverk og industri (1340), lager (1350) og bensin-/energistasjon (1360), samt energianlegg. Dette med unntak av på Strindheim mellom jernbanen og Innherredsveien, hvor det fra andre etasje og opp kan etableres kontor

(1310).

Innenfor felt merket NA bør næringsarealene forbeholdes større produksjons- og lager/logistikkvirksomheter med behov for stort, sammenhengende areal.

På Tiller i felter merket NF kan det vurderes tillatt forretning for plasskrevende varegrupper gjennom reguleringsplan.

For Tunga næringsområde tillates det kontor for virksomheter med få besøkende fra andre etasje og opp. Etasjer på bakkeplan skal forbeholdes næringsformål som angitt over.

Det vises for øvrig til retningslinjene under § 18 Rett virksomhet på rett sted.

§ 24.5 Idrettsanlegg (1400)
Ved detaljregulering skal det i tillegg til idrettsanlegg legges til rette for grønne forbindelser og egenorganisert aktivitet.

§ 24.6.2 Massedeponi
Ved detaljregulering og søknad om etablering av massedeponi skal det foreligge en plan for drifts- og anleggsfasen. Planen skal sikre naturverdier og trinnvis utvikling av deponiet, slik at naturverdier ivaretas fram til området tas i bruk.

Etterbruk til LNFR skal sikres i reguleringsplan. Jordbruksarealer skal istandsettes for jordbruksdrift. Felt merket MN kan ha næringsbebyggelse som etterbruk. Dette må sikres i reguleringsplan.

Ved etablering av nye massedeponi eller ved vesentlige utvidelser, skal det vurderes sorteringsanlegg og muligheter for gjenbruk av rene masser.

Planen bør også redegjøre for miljøbelastninger knyttet til drift og transport til og fra deponiet for influensområdet, geotekniske forhold, landbruksfaglige forhold, landskap/stedskvalitet, og naturmangfold og vannmiljø.

§ 24.7.5 Fossegrenda KB5 (ny bestemmelse)
Innenfor område KB5 tillates bolig og næring med minimum utnyttelse 100% BRA.

§ 25.2 Offentlige parker
Arealene skal gi tilbud til alle og være offentlig tilgjengelige. Overvannshåndtering skal være godt ivaretatt. Materialbruk og utførelse skal ha høy kvalitet og sikre lang levetid ved høy bruksintensitet.

All vegetasjon bør sikres gode vekstforhold. Der offentlig park etableres på tak eller konstruksjoner under bakken bør konstruksjonen dimensjoneres til å tåle etablering av trær, vegetasjon og jordoverdekning, samt vedlikeholdskjøretøy.

§ 28.3.2 Grunneiere og andre rettighetshavere
For grunneiere og andre rettighetshavere i tilsigsområdet gjelder følgende bestemmelser:
Hele hensynssonen:
a. Det er forbudt å lagre avfall eller avløpsslam.
b. Fritidsboliger skal ikke ha innlagt vann. Fritidsboliger skal ha avløpsfritt forbrenningstoalett eller annen løsning

c. Kunstgjødsel må primært lagres under tak eller sekundært være forsvarlig tildekket. Det er forbudt med inntransport av husdyrgjødsel eller avløpsslam til nedbørfeltet.
d. Transport og lagring av farlige produkter, som oljeprodukter, drivstoff og kjemikalier, skal foregå slik at det ikke kan utgjøre noen fare for forurensning i sonen. Kravet omfatter også håndtering av maskiner eller andre kjøretøy ved vask, reparasjon, oljeskift og lignende aktiviteter som kan medføre fare for forurensning i sonen. Dersom det skjer utslipp i nedbørfeltet, plikter den som oppdager utslippet å varsle vannverkseier og forurensningsmyndigheten.
e. Det er forbudt å salte veier.

§ 28.4 Bestemmelsen strykes

§ 28.5 Bestemmelsen strykes.

§ 28.6 Bestemmelsen strykes.

§ 30.2 Bestemmelsen strykes.

§ 30.3 Bestemmelsen strykes.

§ 32.3 Bestemmelsesområde #3, Mobilitetsfunksjoner
Innenfor bestemmelsesområdet skal mobilitetsfunksjoner samles ett eller flere steder med bydelsparkering, i tråd med mål om et bilfritt område på Nyhavna. Dette sikres ved detaljregulering innenfor felt 1 - 10 i KDP Nyhavna. Det kan benyttes midlertidige parkeringsløsninger for å dekke parkeringskravet for boligene inntil 250 av boligene totalt innenfor feltene er tatt i bruk.

§ 32.4 Bestemmelsesområde #4, Sjøbad Strandveikaia
Innenfor området skal det etableres offentlig sjøbad i tråd med Kvalitetsprogram for Nyhavna.

§ 32.6 Bestemmelsesområde #6, Offentlig tjenesteyting
Før planlegging eller gjennomføring av tiltak innenfor området skal behov for offentlig tjenesteyting avklares.

På Hallset skal bestemmelsen ivareta et nytt helse- og velferdssenter, på Tempe og Overvik en ny barnehage, og på Strindheim en utvidelse av skoletomt.

§ 32.10 Bestemmelsesområde #12, Bynaturpark (ny bestemmelse)
Innenfor området skal det tas særskilt hensyn til naturverdier, kulturmiljø og landskap. Særskilte krav til blågrønn faktor for området, angitt i kommunens Norm for blågrønn faktor, skal oppfylles. Ved planlegging av nye samferdselsanlegg skal etablering av allé eller trær vurderes. For eksisterende alleer og trerekker skal trær og tilstrekkelig rotsone bevares. Allétrær som fjernes skal erstattes

Byggesone	Sykkel	Bil – per 100 m2 BRA
Byggesone 1 – felt S1	Største tall av 3 parkeringsplass pr. 100 m2 og 1,5 parkeringsplass per	Midtbyen: 0 / S1: maks. 0,4
Byggesone 1 – felt S1		min 0,1 - maks 0,7
Byggesone 2		min 0,2 – maks 0,9

Byggesone 3	boenhet	min 0,4 – maks 1,1
Øvrige soner		min 0,6 – maks 1,5
Frittliggende eneboliger ogtomannsboliger i byggesone3 og øvrige soner	4 pr. boenhet	min. 2 pr boenhet

Generelt

Næringsareal

Bystyret ber byrådet fram til rullering av neste KPA kartlegge og finne nye næringsarealer slik at målet om 3000 dekar næringsareal fastholdes. Bystyret mener nytt næringsareal er nødvendig for å sikre transformasjon av enkelte områder f.eks. Nyhavna, Lade, Tempe og Sluppen. Det er også viktig å sikre tilstrekkelig areal for å tilrettelegge for ny næringsvirksomhet. Trondheim som teknologihovedstad har et mål om å skape betydelig høyt antall arbeidsplasser knyttet til teknologi, som vil kreve arealer for ny produksjon og utviklingsarbeid. I tillegg vokser byen med et stort antall nye innbyggere årlig som igjen fører til økt behov knyttet til lager og logistikk.

Offentlig tjenesteyting

Bystyret ber byrådet om å følge opp følgende i arbeidet med revidering av plan for areal til offentlige tjenester (PAOT) og i forbindelse med neste rullering av kommuneplanens arealdel (KPA):

- Finne flere områder til helse- og velferdssenter, skoler, barnehager og idrettsformål for å dekke behovet. Det skal vurderes om dette kan løses innenfor andre arealformål, særlig hvordan helse- og velferdssenter og barnehager kan inkluderes i sentrumsformål og boligprosjekter.

Utredning økologisk kompensasjon

Bystyret ber byrådet utrede hvordan økologisk kompensasjon kan brukes for å ivareta prinsippet om arealnøytralitet i kommuneplanens arealdel. Målet med utredninga er en kommunal veileder for økologisk kompensasjon.

Fortetting av eksisterende næringsareal

Bystyret ber byrådet om å ha dialog med aktører som kan bidra til økt utnyttelse og fortetting av eksisterende næringsareal slik at sentrale områder kan transformeres raskere.

Drikkevannsbestemmelser Jonsvatnet

Hensynssonene blir som foreslått i innstillingen til ny KPA, men gjeldende bestemmelser i KPA videreføres. Bystyret ber byrådet om å legge fram nytt forslag til bestemmelser knyttet til hensynssonen rundt Jonsvatnet innen sommeren 2025

Innbyggernes bro

Innbyggernes bro tas ut av plankartet, jf. vedtak i sak 165/24 Videre arbeid med Innbyggernes bro i formannskapet 22.05.2024.

Behov for nye høringer

Bystyret ber byrådet sende følgende forslag på høring. Bystyret ber byrådet komme tilbake med et forslag og en sak til bystyret etter høringsrunden er avsluttet.

1. § 6.6 Byggegrense mot formålet blå/grønnstruktur endres til retningslinje
2. § 10.4 endres til retningslinjer
3. § 13.3 Snøopplag endres til: Langs offentlig veg skal det sikres tilstrekkelig areal til snøopplag.

Areal til snøopplag sikres gjennom den enkelte reguleringsplan, på grunnlag av forventede snømengder.
4. Nye minimums- og maksimumsgrenser for bilparkering i §14.1:
§ 14.1 Midtbyen: min 0 / S1: maks 0.6
Byggesone 1 - felt S2-S5 min. 0 - maks 0.8
Byggesone 2 min. 0 - maks 1
Byggesone 3 min. 0 - maks 1.2
Øvrige soner min. 0 - maks 1.5
Frittliggende eneboliger og tomannsboliger i byggesone 3 og øvrige soner: min. 1 pr boenhet
5. Nye maksimumsgrenser for bilparkering pr 100 m2 BRA i §14.2:
Forretning, maks 4
Kontor, byggesone 1 og 2: maks 0.5
Kontor, byggesone 3: maks 1
Kontor, øvrige soner: maks 2
Privat tjenesteyting, maks 0.5.
6. Bestemmelse 14.5.2 endres til:
Utforming av nye parkeringsanlegg skal være i henhold til Statens vegvesen Håndbok N100.
Ved vedlikehold av eksisterende anlegg kan 2,3 meters bredde aksepteres.
7. Punkt b og c i § 23.3.2 strykes
8. 23.3.4 Bymiljø endres til retningslinje
9. Nytt forslag til § 23.5.1 Utnyttelsesgrad
Grad av utnytting tilpasses områdets strøkskarakter, samtidig som hensiktsmessig utnyttelse av arealet sikres.

Ivaretakelse av eksisterende bomiljø, naturverdier og kulturhistoriske verdier bør tillegges vekt ved nye bygninger og andre tiltak.

Ved planlegging av større nye byggeområder eller transformasjonsområder bør det legges vekt på effektiv arealbruk innenfor de rammene som for øvrig er gitt i bestemmelsene. Andel areal på bakkeplan avsatt til kjøring og parkering bør begrenses.
10. §24.4.2 Utnyttelse og utforming (næringsareal) endres ved at første setning beholdes som bestemmelse, øvrig endres til retningslinje.
11. Ny tekst til bestemmelse § 26.3 Fritidsbebyggelse
Oppføring av ny eller utvidelse av bestående fritidsbebyggelse kan godkjennes så lenge tiltaket ikke medfører flere boenheter eller legger til rette for økt bruk. Bruksendring fra fritidsbebyggelse til bolig er ikke tillatt.
12. Markagrensa i Klæbu: Nytt forslag til rød strek (Markagrensa) i tidligere Klæbu kommune flyttes slik at eksisterende helårsboliger ikke ligger innenfor rød strek etter endringen.
13. Teksten " turistbåter med godkjenning " legges til bestemmelsens §27.4 ift hvilke aktiviteter som er unntatt fra forbudet
14. Tilgrensede tomter til område 937 Østmarka gnr/bnr 413/168 og 169 høres som blå/grønnstruktur.
15. Område 127 Moksneslia sendes på høring med formål byggesone 2.
16. Område 402 Ladalen sør for Haakon VIIs gate som var foreslått som næring høres som byggesone 1, med bestemmelser som sikrer areal til blå/grønnstruktur som er minst like stort som det som ble hørt november 2022.
17. Området på Byåsen mellom Bygrensa, Åsveien skole og Breidablikk som vist i kartutsnitt under med byggesone 2 sendes på høring med formål byggesone 3.

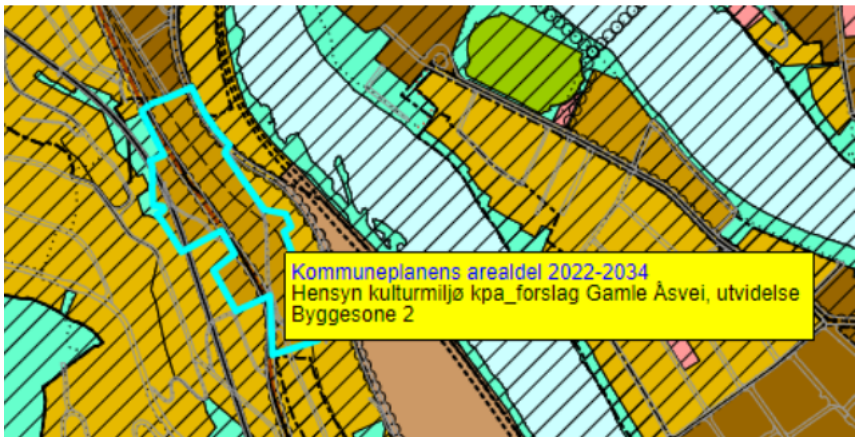

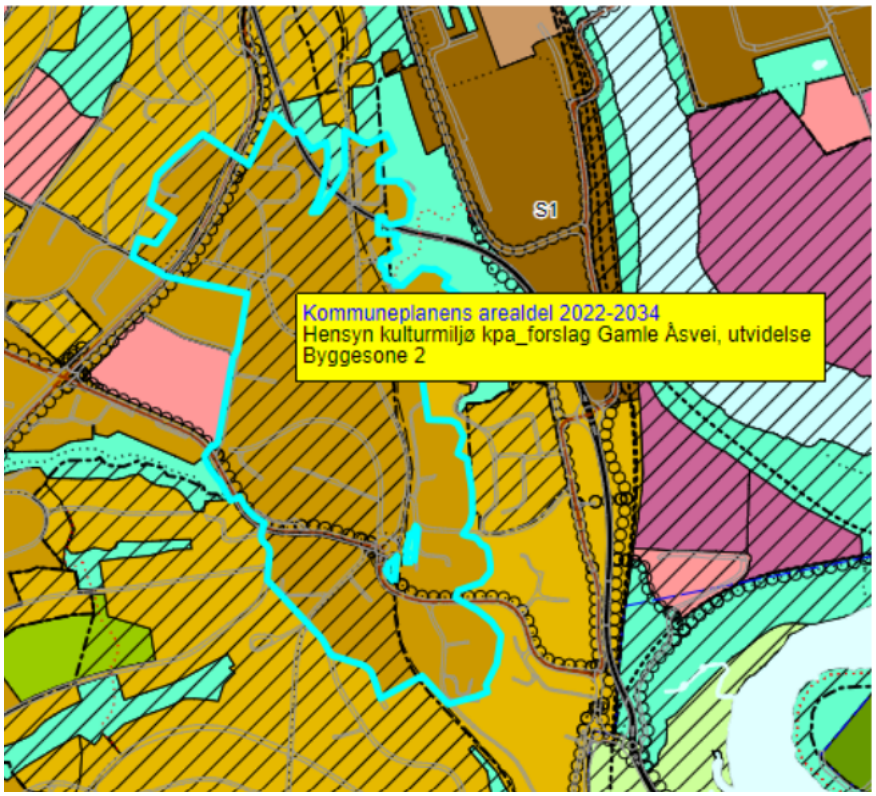

Øvre Rotvoll sør (911a) Framtidig næringsbebyggelse.

Hele Rotvolltrekanten får arealformålet kombinert bebyggelse og anlegg og næringsformål Det settes av areal til kollektivanlegg, kommunaltekniske anlegg, energianlegg, energistasjon og renovasjonsanlegg. Det skal legges til rette for næringsareal på resterende areal og over bussdepot, bydrift og energistasjon der dette er mulig.

Behandling:

Kirsti Tømmervold (Ap) fremmet følgende utsettelsesforslag på vegne av Ap, FrP:
Saken utsettes med bakgrunn i at det nå, under et døgn før vedtak, ikke er kjent hva som er posisjonens forslag til vedtak. KPA er en omfattende sak med et betydelig underlag, og våre vedtak har stor betydning for byens innbyggere. Saken fortjener en sluttbehandling der de ulike

partigruppene kan ta gode og opplyste valg.

Elin Marie Andreassen fremmet følgende alternative forslag:
Alternativt forslag til vedtak:

1. Bystyret vedtar forslag til ny kommuneplanens arealdel 2022-2034 som vist på kart i målestokk 1:40 000, senest datert 07.05.2024, og med bestemmelser senest datert 07.05.2024 og beskrevet i planbeskrivelsen, senest datert 07.05.2024, og med de endringer som følger av bystyrets vedtak.

2. Arealdelen vedtas med rettsvirkning ved bystyrets vedtak, med unntak av de avgrensede utbyggingsområdene som det er knyttet innsigelser til, jf. plan- og bygningsloven § 11-16. Disse tas opp til mekling og eventuell videre behandling hos kommunal- og distriktsdepartementet, jf. plan- og bygningsloven § 5-6.

3. Kommuneplanen gjelder fra det tidspunkt planen er vedtatt av bystyret, og vil da gjelde for alle søknader om tiltak og forslag om regulering, jf. § 11-6. Unntak gis for planforslag som mottas som komplett innen seks måneder etter vedtaket av arealdelen. Planforslaget skal være komplett etter loven og krav gitt i Trondheim kommunes veileder for reguleringsplaner. Unntak forutsetter videre at føringer gitt i kommuneplanens arealdel for Trondheim 2012-2024 eller for Klæbu 2010-2021 følges. En eventuell kombinasjon med føringer fra ny arealdel forutsetter at dette bidrar til bedre bolig- og bykvalitet.

Vedtaket fattes i henhold til plan- og bygningsloven § 11-15.

4. Bystyret vedtar at det gjennomføres ny høring for de områder og bestemmelser som etter dette vedtaket er nødvendig, før de tas opp til endelig sluttbehandling.

5. Bystyret vedtar følgende endringer i arealdisponering:
5.1. 3 Foldal
KU nr. 3 Foldal avsettes til byggesone 3.
5.2. 9 Fossegrenda
KU nr. 9 Fossegrenda avsettes til byggesone 2 og næringsformål.
5.3. 14 Sivert Dahlens veg
KU nr. 14 Sivert Dahlens veg avsettes til byggesone 3 og LNFR.
5.4. 28 Valkyrjeveien 7
KU nr. 28 Valkyrjeveien 7 avsettes til byggesone 2.
5.5. 31 Lundskogen
KU nr. 31 Lundskogen avsettes til LNFR og fremtidig gravplass.
5.6. 37 Havstein
KU nr. 37 Havstein avsettes til Byggesone 2 og blå/grønnstruktur.
5.7. 41 Røddevegen0 Kommentarer
KU nr. 41 avsettes til fremtidig næringsbebyggelse.
5.8. 43 Bratsberg og Sneegga
KU nr. 43 Bratsberg og Sneegga avsettes til fremtidig massedeponi.
5.9. 48 Stokkåsen
KU nr. 48 Stokkåsen avsettes til byggesone 3. Markagrensa flyttes utenfor byggesonen.
5.10. 50 Bratsbergvegen 139
KU nr. 50 Bratsbergvegen 139 avsettes til byggesone 3.
5.11. 51 Sandmoen
KU nr. 51 Sandmoen avsettes til næringsbebyggelse. Hotell/overnatting tillates.
5.12. 53 Forsøkslia

KU nr. 53 Forsøkslia avsettes til næringsbebyggelse.
5.13. 54 Klett
KU nr. 54 Klett avsettes til byggesone 3.
5.14. 55 Innherredsveien
KU nr. 55 Innherredsveien avsettes til byggesone 3.
5.15. 57 Osloveien 276A
KU nr. 57 Osloveien 276A avsettes til byggesone 3.
5.16. 58 Flatåsen senterområde
KU nr. 58 Flatåsen senterområde avsettes i sin helhet til sentrumsformål, byggesone 1.
5.17. 67 Kleiva
KU nr. 67 Kleiva avsettes til byggesone 3.
5.18. 70 Stormyra
KU nr. 70 Stormyra avsettes til byggesone 3.
5.19. 74 Brøttemsvegen
KU nr. 74 Brøttemsvegen avsettes til fremtidig næringsbebyggelse.
5.20. 75 Stokkanhaugen
KU nr. 75 Stokkanhaugen avsettes til byggesone 3 og blå/grønnstruktur.
5.21. 77 Granåsen gård
KU nr. 77 Granåsen gård avsettes til byggesone 3.
5.22. 82 Moen, LNFR mot Nidelva, Finnhaugen, Oddmyra
KU nr. 82 Moen, LNFR mot Nidelva, Finnhaugen, Oddmyra avsettes til fremtidig massedeponi og LNFR.
5.23. 87 Dalgård
KU nr. 87 Dalgård avsettes til byggesone 2.
5.24. 88 Prestegårdsveien 74, Duvåsen
KU nr. 88 Prestegårdsveien 74, Duvåsen avsettes til fritids- og turistformål.
5.25. 90 Tesliåsen
KU nr. 90 Tesliåsen avsettes til byggesone 3.
5.26. 92 Torgård
Byens viktigste landskapstrekk er høydedragene som omkranser byen, strandsonen, elve- og bekkedalene, jordbrukslandskapet, sammenhengende grøntdrag og markante trær.
5.27. 93 Heimdalsvegen
KU nr. 93 Heimdalsvegen avsettes til fremtidig næringsbebyggelse.
5.28. 94 Røddevegen, Røddevegen, Ridehallen Klett
KU nr. 94 Røddevegen, Røddevegen, Ridehallen Klett avsettes til fremtidig næringsbebyggelse.
5.29. 96 Brøttemsvegen (Røddevegen)
KU nr. 96 Brøttemsvegen avsettes til fremtidig næring og råstoffutvinning.
5.30. 97 Kjøsan
KU nr. 97 Kjøsan avsettes til massedeponi og fremtidig LNFR.
5.31. 102 Okstadøya
KU nr. 102 Okstadøya avsettes til byggesone 3.
5.32. 106 Flatåsen næringsareal
KU nr. 106 Flatåsen næringsareal avsettes til byggesone 1.
5.33. 108 Kastbrekka/Tomset
KU nr. 108 Kastbrekka/tomset avsettes til byggesone 2.
5.34. 110 Fuglmyra
KU nr. 110 Fuglmyra avsettes til fremtidig næringsbebyggelse.
5.35. 113 Vassfjellet hyttefelt
KU nr. 113 Vassfjellet hyttefelt avsettes til fritidsbebyggelse.

5.36. 114 Selbusjøen hyttefelt
KU nr. 114 Selbusjøen hyttefelt avsettes til fritidsbebyggelse.
5.37. 120 Hermo, Hermo
KU nr. 120 Hermo, Hermo avsettes til byggesone 3.
5.38. 124 Gamle Ladejarlen VGS
5.39. KU nr. 124 Gamle Ladejarlen VGS avsettes til byggesone 2. Hensynssone bevaring naturmiljø må følge den blågrønne strukturen, og ikke legges inn i byggesonen.
5.40. 126 Lianvatnet skole
KU nr. 126 Lianvatnet skole avsettes til tjenesteyting.
5.41. 127 Moksneslia
KU nr. 127 Moksneslia avsettes til byggesone 2.
5.42. 130 Espflaten
KU nr. 130 Espflaten avsettes til byggesone 3.
5.43. 134 Stubbsvingen 63
KU nr. 134 stubbsvingen 63 avsettes til byggesone 3.
5.44. 142 Eklestrøa
KU nr. 142 Eklestrøa avsettes til fremtidig næringsbebyggelse, LNFR og kolonihager med parseller. Eksisterende boligeiendommer avsettes til byggesone 3.
5.45. 143 Oustmyrvegen
KU nr. 143 Oustmyrvegen avsettes til byggesone 3.
5.46. 145 Høvilåsen vestre
KU nr. 145 Høvilåsen vestre avsettes til fritidsbebyggelse.
5.47. 218 Kruskajordet
KU nr. 218 Kruskajordet avsettes til byggesone 2.
5.48. 317 Chamonix
KU nr. 317 Chamonix avsettes til byggesone 2 og offentlig tjenesteyting.
5.49. 318 Vidarheim
KU nr. 318 Vidarheim avsettes til byggesone 2 og offentlig tjenesteyting.
5.50. 319 Ringvålvegen
KU nr. 319 Ringvålvegen avsettes til byggesone 2 og offentlig tjenesteyting.
5.51. 320 Fjellseterveien
KU nr. 320 Fjellseterveien avsettes til byggesone 2.
5.52. 326 Nils Uhlin Hansens veg (Stavset)
KU nr. 326 Nils Uhlin Hansens veg (Stavset) byggesone 2 og offentlig tjenesteyting.
5.53. 330 Einar Tambarskjelves gate
KU nr. 330 Einar Tambarskjelves gate avsettes til byggesone 1.
5.54. 331a Blyberget
KU nr. 331a Blyberget avsettes til byggesone 2 og offentlig tjenesteyting.
5.55. 331b Steinberget
KU nr. 331b Steinberget avsettes til byggesone 2 og offentlig tjenesteyting.
5.56. 332 Grilstad
KU nr. 332 Grilstad avsettes til næringsbebyggelse.
5.57. 333 Solbergåsen/Lundåsen
KU nr. 333 Solbergåsen/Lundåsen avsettes til byggesone 2 med bestemmelsesområde #6.
5.58. 337 Hallsteingård
5.59. KU nr. 337 Hallsteingård avsettes til byggesone 2 og offentlig tjenesteyting.
5.60. 340 Aktivitetshus med driftsgarasje, Kattem
KU nr. 340 Aktivitetshus med driftsgarasje, Kattem, avsettes til blå/grønnstruktur.
5.61. 351 - Brundalen utvidelse bhg
KU nr. 351 Brundalen utvidelse bhg avsettes til byggesone 3 og

blå/grønnstruktur.
5.62. 401 KDP Nyhavna m.fl.
KU nr. 401 KDP Nyhavna avsettes til KDP Nyhavna og kaibasert næring.
5.63. 402 Ladalen
KU nr. 402 Ladalen avsettes til sentrumsformål med næring i nederste etasjer.
5.64. 403 Valøya
KU nr. 403 Valøya avsettes til sentrumsformål og blå/grønnstruktur.
5.65. 404 Tiller sør
KU nr. 404 Tiller sør beholdes som sentrumsformål.
5.66. 405 Forset/Tanem, Tjønnmyra
KU nr. 405 Forset/Tanem, Tjønnmyra avsettes til kombinert bebyggelse næring og massetak.
5.67. 601 Grismyra
KU nr. 601 Grismyra avsettes til byggesone 4.
5.68. 602 Tanemsmyra, Tanemsflata/Tanemsmyra
KU nr. 602 avsettes til byggesone 2 og blå/grønnstruktur.
5.69. 603 Vest for Tanem skole
KU nr. 603 Vest for Tanem avsettes til fremtidig tjenesteyting.
5.70. 604 - Gjellan/Trøåsen
KU nr. 604 Gjellan/Trøåsen avsettes til byggesone 3 og grøntstruktur, og utvikles i tråd med gjeldende reguleringsplan.
5.71. 605 Klæbu sentrum, Rydland
KU nr. 605 Klæbu sentrum, Rydland avsettes til byggesone 3 og blå/grønnstruktur.
5.72. 606 Klæbu sentrum, Stormyra N
KU nr. 606 Klæbu sentrum, Stormyra N avsettes til byggesone 3 og blå/grønnstruktur.
5.73. 607 Tulluan, Tullusmyra N
KU nr. 607 Tulluan, Tullusmyra N avsettesw til byggesone 3 og blå/grønnstruktur.
5.74. 611 Kvennildsmyra S, Sandmoen
KU nr. 611 Kvennildsmyra S, Sandmoen avsettes til næringsbebyggelse.
5.75. 612 Kvennildsmyra Ø
KU nr. 612 Kvennildsmyra Ø avsettes til næringsbebyggelse.
5.76. 613 Heggstadmoen
KU nr. 613 Heggstadmoen avsettes til næringsbebyggelse.
5.77. 616 Vassfjellet, uregulert
KU nr. 616 Vassfjellet, uregulert avsettes til fritidsformål.
5.78. 618 Furuhaugmyra
KU nr. 618 Furuhaugmyra avsettes til idrettsanlegg og LNFR.
5.79. 621 Klæbu sentrum, Stormyra S
KU nr. 621 Klæbu sentrum, Stormyra S avsettes til idrettsanlegg.
5.80. 622 Digresmyra
KU nr. 622 Digresmyra avsettes til idrettsanlegg.
5.81. 626 Lia pukkverk, Stamsåsen
KU nr. 626 Lia pukkverk, Stamsåsen avsettes til råstoffutvinning.
5.82. 701 Heimdal stasjonsparken
KU nr. 701 Heimdal stasjonsparken avsettes til sentrumsformål.
5.83. 702 Heimdal Industriveien
KU nr. 702 Heimdal Industriveien avsettes til sentrumsformål.
5.84. 703 Flatåsen sentrumskjerne
KU nr. 703 Flatåsen sentrumskjerne avsettes til sentrumsformål med areal for helse- og velferdssenter.
5.85. 704 Stavset sentrumskjerne

KU nr. 704 Stavset sentrumskjerne avsettes til sentrumsformål.
5.86. 705 Moholt sentrumskjerne
KU nr. 705 Moholt sentrumskjerne avsettes til sentrumsformål.
5.87. 706 Fossegrenda sentrumskjerne
KU nr. 706 Fossegrenda sentrumskjerne avsettes til sentrumsformål.
5.88. 707 Nardo sentrumskjerne
KU nr. 707 Nardo sentrumskjerne avsettes til sentrumsformål.
5.89. 732 Dragvoll
KU nr. 732 Dragvoll avsettes til byggesone 3.
5.90. 801 Trolla
KU nr. 801 Trolla avsettes til byggesone 3.
5.91. 802 Rye
KU nr. 802 Rye avsettes til byggesone 3.
5.92. 805 Seibergskjæret
KU nr. 805 Seibergskjæret avsettes til byggesone 3.
5.93. 806 Høgberget
KU nr. 806 Høgberget avsettes til byggesone 3.
5.94. 807 Skogan
KU nr. 807 Skogan avsettes til byggesone 3.
5.95. 808 Bjørkheim
KU nr. 808 Bjørkheim avsettes til byggesone 3.
5.96. 809 Ringvål
KU nr. 809 Ringvål avsettes til byggesone 3.
5.97. 810 Lund
KU nr. 810 Lund avsettes til byggesone 3.
5.98. 811 Fortunalia
KU nr. 811 Fortunalia avsettes til byggesone 3.
5.99. 812 Vikåsen
KU nr. 812 Vikåsen avsettes til byggesone 3.
5.100. 814 Sveen
KU nr. 814 Sveen avsettes til byggesone 3.
5.101. 815 Brøttemsvegen
KU nr. 815 Brøttemsvegen avsettes til byggesone 3.
5.102. 816 Klæbu
KU nr. 816 Klæbu avsettes til byggesone 3.
5.103. 817 Brøttemsåsen
KU nr. 817 Brøttemsåsen avsettes til byggesone 3.
5.104. 818 Hyttfossen
KU nr. 818 Hyttfossen avsettes til byggesone 3.
5.105. 819 Eggan
KU nr. 819 Eggan avsettes til byggesone 3.
5.106. 852 Tanembruvegen
KU nr. 852 Tanembruvegen avsettes til fritidsformål.
5.107. 873 Torvmyra
KU nr. 873 Torvmyra avsettes til massedeponi.
5.108. 881 Nordset
KU nr. 881 Nordset avsettes til råstoffutvinning.
5.109. 891 Ust
KU nr. 891 Ust avsettes til byggesone 3.
5.110. 901 Kleiva

KU nr. 901 Kleiva avsettes til byggesone 3.
5.111. 902 Utleirvegen 140, Kastbrekka
KU nr. 902 Utleirvegen 140, Kastbrekka avsettes til byggesone 2.
5.112. 903 Bjørkheim
KU nr. 903 Bjørkheim avsettes til byggesone 2.
5.113. 904 Reppevegen (1)
KU nr. 904 Reppevegen (1) avsettes til byggesone 3.
5.114. 910 Overvik gårdstun
KU nr. 910 Overvik gårdstun avsettes til byggesone 3.
5.115. 911 Øvre Rotvoll sør
KU nr. 911 Øvre Rotvoll sør avsettes til byggesone 2. Ei stripe langs E6
reguleres til næringsformål.
5.116. 912 Rotvolltrekanten
KU nr. 912 Rotvolltrekanten avsettes til kombinert bebyggelse, næring, kommunalteknisk og bussdepot m.fl.
5.117. 919 Leinan
KU nr. 919 Leinan avsettes til fremtidig næringsbebyggelse.
5.118. 920 Myrsund
KU nr. 920 Myrsund avsettes til fremtidig næringsbebyggelse.
5.119. 921 Wullumsgården
KU nr. 921 Wullumsgården avsettes til byggesone 2 og offentlig tjenesteyting.
5.120. 922 Østre Sverreborg plass
KU nr. 922 Østre Sverresborg plass avsettes til byggesone 3 og offentlig tjenesteyting.
5.121. 924 Berg prestegård
KU nr. 924 Berg prestegård avsettes til byggesone 2 og blå/grønnstruktur.
5.122. 926 Klokkesvingen Lerkendal
KU nr. 926 Klokkesvingen Lerkendal avsettes til byggesone 1.
5.123. 927 Nardovegen 23
KU nr. 927 Nardovegen 23 avsettes til byggesone 2.
5.124. 928 Saghaugen
KU nr. 928 Saghaugen avsettes til fritidsbebyggelse.
5.125. 932 Brøset
KU nr. 932 Brøset avsettes til byggesone 2 og offentlig tjenesteyting.
5.126. 934 Sivert Dahlens veg 27 og 29
KU nr. 934 Sivert Dahlens veg 27 og 29 avsettes til byggesone 3 og LNFR.
5.127. 937 Østmarka
KU nr. 937 Østmarka avsettes til byggesone 2, tjenesteyting og blå/grønnstruktur.
5.128. 941 Ranheimsvegen 305
KU nr. 941 Ranheimsvegen 305 avsettes til byggesone 3.
5.129. 945 Brøsetekra 5, 7 og 13
KU nr. 945 Brøsetekra 5, 7 og 13 avsettes til byggesone 2.
5.130. 946 BB1-BB3 i Granås Øst
KU nr. 946 BB1-BB3 i Granås Øst avsettes til byggesone 2.
5.131. 947 Bjøra (tidl. 135)
KU nr. 947 Bjøra (tidl. 135) avsettes til byggesone 3.
5.132. 949 Buengveien 1A, Forsøkslia/Buenget
KU nr. 949 Buengveien 1A, Forsøkslia/Buenget avsettes til byggesone 3.
5.133. 953 Tunga med forretning, Tunga NF og Tungavegen 28-38
KU nr. 953 Tunga med forretning, Tunga NF og Tungavegen 28-38 avsettes til kombinert bebyggelse næring og forretning.

5.134. 954 Tiller med forretning, Tiller NF, Tiller sør
KU nr. 954 Tiller med forretning, Tiller NF, Tiller sør avsettes til sentrumsformål og næringsbebyggelse.
5.135. 957 Flakk
KU nr. 957 Flakk avsettes til fremtidig næringsbebyggelse.
5.136. 958 Myrsundet
KU nr. 958 Myrsundet avsettes til fremtidig næringsbebyggelse.
5.137. 962 Svemyra
KU nr. 962 Svemyra avsettes til fremtidig næringsbebyggelse.
5.138. 964 Storfagerlibekken
KU nr. 964 Storfagerlibekken avsettes til fremtidig næringsbebyggelse.
5.139. 965 Under Svartåsen
KU nr. 965 Under Svartåsen avsettes til fremtidig næringsbebyggelse.
5.140. 967 Litjvollen, Vassfjellet
KU nr. 967 Litjvollen, Vassfjellet avsettes til fremtidig næringsbebyggelse.
5.141. 968 Sagåsen - Rotmyråsen
KU nr. 968 Sagåsen - Rotmyråsen avsettes til fremtidig næringsbebyggelse.
5.142. 970 Furuhaugen
KU nr. 970 Furuhaugen avsettes til kombinert bebyggelse, anlegg deponi, råstoffutvinning og LNFR.
5.143. 973 Østmarka0 Kommentarer
KU nr. 973 Østmarka avsettes til byggesone 2, tjenesteyting og noe blå/grønnstruktur.
5.144. 944 Tanemsflata/Tanemsmyra
Tanemsflata/Tanemsmyra avsettes til byggesone 2.
5.145. Solemsvegen 5
Solemsvegen 5, gnr/bnr. 109/131:
En smal stripe helt sør på eiendommen, som gjennom reguleringsplan for Lian og Kystadmarka er avsatt til friluftsformål, endres til boligformål.
5.146. Heimstad/Tiller-ringen
Heimstad/Tiller-ringen avsettes til byggesone 3.
5.147. Torvmyra 2 (Bunnpris Tonstad)
Torvmyra 2 (Bunnpris Tonstad) avsettes til byggesone 2.
5.148. Ringvålvegen 98
Ringvålvegen 98 avsettes til byggesone 2.
5.149. Øvre allé 25 og 27 og Eidsvolls gate 2A
Eiendommene 406/26, 406/27 og 406/161, Øvre allé 25 og 27 og Eidsvolls gate 2A, klassifiseres ikke, og holdes utenfor hensynssone for Singsaker,
inklusive Kristianfeldt.
5.150. Haakon VIIs 8-12
Haakon VIIs gate 8-12 avsettes til byggesone 1.
5.151. Haakon VIIs gate (sør for)
Arealet sør for Haakon VII gate som i forslag til ny KPA er regulert til næringsareal, reguleres til byggesone 1.
5.152. Overvik områdeplan
Overvik utvikles i tråd med Overvik områdeplan, r20150024.
5.153. Lilleuglen, gnr./bnr. 518/1
Områder øst og vest for Tanemsbruvegen skal høres som fremtidig næringsareal og noe fremtidig jordbruksareal i tråd med innspill fra Adnor Advokat AS.
5.154. Lerslia, del av gnr/bnr 215/1, 215/2 m.fl.
Bystyret viser til detaljregulering av Lerslia, del av gnr/bnr 215/1, 215/2 m.fl., r20150037,

sluttbehandling, behandlet og avvist i bystyret 4.2.2021. Bystyret ber om at det på nytt startes en prosess for å sikre at arealene kan benyttes til massedeponi.
5.155. Vikingvegen
Deler av gnr./bnr. 521/137, inkludert Vikingvegen 8 og areal i nord mot Finnmyrvegen avsettes til byggesone 1 eller 2 etter høring.
5.156. Kleivavegen 23 og 25
For boligeiendommene 80/17 og 80/30 skal ikke omfattes av markagrensa, og avsettes til byggesone 3 etter høring.
5.157. Områder avvist ved fastsetting av planprogram
Områdene #16 - Byneset, Klefstadbakkan, #18 - Bratsberg, Ny Jord-vegen 114, #24 - Klæbu, Eidstutrøa, #27 - Byneset, Nerhovsvegen 169 - Begrenset til del av 248/2, teig i vest, beliggende langs Skolvegen, og #95 - Lund, Øvre Solberg og Lund Vestre skal høres i tråd med opprinnelig innspill til planprogrammet.

6. Bystyret vedtar følgende endringer i bestemmelser og retningslinjer, vedlegg 3:
6.1. § 1 Formål
§ 1 endres slik:
Kommuneplanens arealdel skal legge til rette for god arealutnyttelse, for å sikre en attraktiv og næringsvennlig kommune, tilstrekkelig tilvekst av nye boliger og gode vilkår for landbruket i kommunen. Kommuneplanens arealdel skal bygge opp under kommuneplanens samfunnsdel 2020-2032, Trondheimsløftet, og bygger på følgende hovedgrep for å oppnå dette:
-ivaretakelse av den private eiendomsretten
-variert boligbebyggelse
-rett virksomhet på rett sted, og nok næringsareal av ulik størrelse
-bevare områder for landbruk, natur og friluftsliv
-legge til rette for et klima- og miljøvennlig transportmønster
-utvikle lokalsenter som reduserer transportbehovet

6.2. § 2.1 Forholdet til kommunedelplaner
§ 2.1 endres slik:
Følgende kommunedelplaner går ved motstrid foran kommuneplanens arealdel: -Kommunedelplan for Sluppen, vedtatt 02.02.2023
-Kommunedelplan for Klett, vedtatt 19.10.2023
-Kommunedelplan for Nyhavna, vedtatt 16.06.2016, unntatt krav til skolekapasitet og unntak av bestemmelsesområde #1 Kaibasert næring.

6.3. § 2.2.3 Forholdet til vedtatte reguleringsplaner
§ 2.23 endres slik:
Alle reguleringsplaner vedtatt etter 21.03.2013 går ved motstrid foran kommuneplanens arealdel.

6.4. § 4.2 Rekkefølgekrav skolekapasitet
Det er ikke rekkefølgekrav om skolekapasitet for boliger innenfor byggesone 1. Fritak for rekkefølgekrav i byggesone 2 kan innvilges gjennom reguleringsplan. Boliger kan ikke tas i bruk før leke- og uteoppholdsareal er etablert.

6.5. § 4.3 Rekkefølgekrav gangareal
Omgjøres i sin helhet til retningslinje og endres slik:
Før det kan godkjennes ny bebyggelse innenfor tettstedene skal det være sikret tilfredsstillende helårs gangareal til nærmeste holdeplass og skole, jfr. § 13.1.2. For tiltak med inntil 1000 m2 BRA kan krav om opparbeidelse av gangareal begrenses til tomtas utstrekning.

Der en adkomstveg betjener mer enn 30 boliger bør det være et eget areal for gående.

6.6. § 6.1 Byggegrense mot sjø - Trondheimsfjorden
Tiltak etter PBL § 1-6 første ledd utenom fasadeendringer kan ikke settes i verk nærmere strandlinjen, målt i horisontalplanet ved alminnelig høyvann, enn:
- Byggesone 1 og naust: 0 meter
- Byggesone 2-4 og øvrige byggeformål: 25 meter
- LNFR: 100 meter

Friluftslivstiltak kan tillates dersom viktige økologiske funksjoner blir opprettholdt. Det samme gjelder tiltak for å fremme naturmangfoldet, og tiltak som har til hensikt å reetablere historiske funksjoner

6.7. § 6.2 Byggegrense mot vassdrag og innsjøer
Tillegg av ny setning sist i første avsnitt:
"Ved gjenåpning av lukkede bekker kan mindre avstandskrav tillates."

6.8. § 6.4 Byggegrense Markagrensa (Rød strek)
Innenfor byggegrensen i plankartet skal det sikres et bærekraftig friluftsliv og et rikt og variert naturmiljø der viktige økologiske funksjoner opprettholdes. Kun tiltak som ikke vesentlig tilsidesetter LNFR-formålet er tillatt.

6.9. § 6.5 Byggegrense langsiktig jordvern (Grønn strek)
§ 6.5 strykes fra bestemmelsene.

6.10. § 6.6 Byggegrense mot formålet blå/grønnstruktur
Omgjøres til retningslinje:
Bebyggelse kan ikke plasseres innenfor formålet blå/grønnstruktur. Dette gjelder ikke innenfor byggesone 1 og 2, eller frittliggende bygninger under 50 m² BRA som ikke skal benyttes til beboelse. Midlertidige tiltak som er reversible kan tillates innenfor formålet. Tiltak på eksisterende bebyggelse innenfor formålet blå/grønnstruktur er tillatt.

6.11. § 6.7 Byggegrense mot dyrka jord
Bebyggelse og inngrep i forbindelse med utbygging skal holdes utenfor dyrka jord.

6.12. § 7.1 Folkehelse
Alle planforslag skal bidra til å utvikle sosialt bærekraftige lokalsamfunn, som motvirker utenforskap og bidrar til tilhørighet og deltakelse.

Tilhørende retningslinjer:
Støy og luftkvalitet, solforhold, tilgang til gode uteoppholdsarealer og sosiale møteplasser i gangavstand, tilrettelegging for fysisk aktivitet, kriminalitets- og ulykkesforebygging og tiltak for å utjevne sosiale helseforskjeller bør vektlegges.

Planforslag bør redegjøre for planens bidrag til kommunens mål for folkehelse og levekår, og virkninger for folkehelse i planområdet og influensområder.

6.13. § 7.2 Universell utforming
Alle planforslag skal redegjøre for universell utforming i planområdet og i sammenheng med omgivelsene. Der det kan oppstå konflikt mellom ulike hensyn, skal planarbeidet avveie alternative løsninger basert på prinsippet om inkludering og likeverd, og hensynet til universell utforming skal og hensynet til universell utforming skal veie tungt.

Tilhørende retningslinjer:
Uttalelser fra kommunalt råd for personer med funksjonsnedsettelser, samt berørte organisasjoner,

brukes som dokumentasjon i saker som omhandler universell utforming.

6.14. § 8.1 Generelt (Arkitektur og byform)
§ 8.1 endres slik:
Til alle planforslag skal det utarbeides stedsanalyse før oppstart.

6.15. § 8.2 Arkitektur
Nye tiltak skal være i samspill med omgivelsene. Fargesetting og materialbruk skal bidra til variasjon i bymiljøet og bygge opp under Trondheims identitet.

6.16. § 8.4 Overordnede strukturer
Viktige landskapstrekk og landemerker, offentlige gater og byrom, blågrønne strukturer og offentlig tilgang til sjø og vassdrag skal være premissgivende for bystrukturen.

Tilhørende retningslinjer:
Byens viktigste landskapstrekk er høydedragene som omkranser byen, strandsonen, elve- og bekkedalene, jordbrukslandskapet, sammenhengende grøntdrag og markante trær.

6.17. § 8.5 Høyhus
- Høyhus kan plasseres i allerede etablerte høyhusområder.
- Høyhus kan vurderes langs viktige innfartsårer og langs høyfrekvente kollektivårer, tilsvarende metrobusslinjer.
- Høyhus kan vurderes der det skal signalisere større lokalt sentrum, allment tilgjengelige tilbud eller annen samfunnsmessig verdi.
- Høyhus kan vurderes der landskapsmessige og lokale forhold ellers tilsier det.

Tilhørende retningslinje:
Høyhus er her bygg over 10 etasjer.

6.18. § 8.6 Svalganger
Ved etablering av svalganger skal disse ha høy kvalitet i form og materialbruk.
6.19. § 9.1 Fredete kulturminner
Bestemmelsen strykes (ivaretas i annet lovverk).
6.20. § 9.2 Antikvarisk verdifull bebyggelse - klasse A, B og C
Bebyggelse i klasse A skal i størst mulig grad etterstrebes bevart i sin helhet, og ikke vesentlig endres. Bebyggelse i klasse B og C skal søkes bevart. Ved tiltak som endrer bygningens uttrykk og detaljering skal funksjonalitet vektlegges.

Tilhørende retningslinje:
Ved bevaring bør det legges særskilt vekt på å bevare opprinnelige og/eller eldre detaljering og materialbruk, herunder vinduer, dører, porter, tak, omramminger og kledning.

Med vesentlig endring forstås svekking av bygningens utvendige antikvariske verdi. Med "eldre" menes bygningsdeler fra byggeår, og der disse ikke finnes menes bygningsdeler fra før 1940. Ved tilbakeføring av bebyggelsen bør dokumentasjon av opprinnelig/tidligere situasjon foreligge.

Antikvarisk verdi forstås som historisk, arkitektonisk eller annen kulturhistorisk verdi. Klassifisering fremgår av kulturminnekartet i Trondheim kommunes innsynsløsning.

6.21. § 9.3 Hensynssoner kulturmiljø
§ 9.3 strykes fra bestemmelsene.

6.22. § 9.4 Båndlegging etter lov om kulturminner, Trondheim middelalderby, arkeologi
§ 9.4 strykes fra bestemmelsene (ivaretatt i annet lovverk).

6.23. § 9.5 Kulturminnevurdering
§ 9.5 strykes fra bestemmelsene.

6.24. § 10.2 Kvaliteter ved boenhetene
Omgjøres i sin helhet til retningslinjer:
For å sikre tilstrekkelig kvalitet bør halvparten av kvalitetskriteriene under være oppfylt for alle boenheter:
- soverom eller stue med fasade mot stille side eller dempet fasade
- beliggenhet utenfor rød støysone
- beliggenhet utenfor rød og gul støysone
- stue, eller privat veranda inntil stue, med sol i minst tre timer 21. april
- størrelse over 35 m2 og/eller med minst ett soverom i tillegg til oppholdsrom
- gjennomgående boenhet eller hjørneleilighet
- utsikt fra stue/hovedoppholdsrom direkte mot landskap/større park /grøntområde
- tilgang til privat eller felles uteoppholdsareal på bakken

6.25. § 10.3 Fellesarealer innendørs
§ 10.3 endres slik:
Ved planforslag med 20 boliger eller mer, skal det i reguleringsplanarbeidet gjøres en konkret vurdering av behovet for etablering av innendørs felles oppholdsareal.

6.26. § 10.4 Uteoppholdsareal
§ 10.4 endres slik:
Ved planforslag med 20 boliger eller mer, skal det i reguleringsplanarbeidet gjøres en konkret vurdering av behovet for etablering av innendørs felles oppholdsareal.

Ved planforslag og søknad om byggetiltak skal alle boenheter innenfor planområdet eller tiltaket ha minste uteoppholdsareal (MUA) i samsvar med tabellen under. Kravet for byggesone 1 - felt S1 utenfor Midtbyhalvøya og felt S2-5 - reduseres med 5 m2 per boenhet/100 m2 boareal dersom offentlig park/torg på minimum 500 m2 er etablert i den aktuelle sentrumskjernen eller innenfor 200 m fra boligene

Tabell 1 - Uteoppholdsareal

Sone	Per boenhet eller per 100 m2	Plassering og fordeling
Byggesone 1, innenfor Midtbyhalvøya	10 m2	- minst 50 % som fellesareal - kravet om eget uteoppholdsareal kan fravikes dersom det ikke er mulig å legge til rette for uteoppholdsareal, og det sikres tilgang til tilstrekkelig og kvalitativt gode leke- og uteoppholdsareal i trafikksikker gangavstand på maksimalt 200 m fra boligene

Byggesone 1, felt S1 utenom Midtbyhalvøya	10 m2	- minst 50 % som fellesareal
Byggesone 1, felt S2 - S5	20 m2	- minst 50 % som fellesareal
Byggesone 2	40 m2	- minst 50 % som fellesareal
Byggesone 3 under 20 boenheter	70 m2	- ved mer enn tre boenheter: minst 40 % som fellesareal - minimum halvparten av alle boenheter skal ha privat uteoppholdsareal på bakkeplan eller balkong
Byggesone 3 over 20 boenheter	60 m2	
Byggesone 4	75 m2	Utformet som privat uteoppholdsareal på bakkeplan.

BRA ved beregning av uteoppholdsareal skal inkludere alt bruksareal til bolig. Annet bruksareal i kjeller (herunder boder), uteoppholdsareal eller innendørs fellesareal skal ikke medregnes.

Tilhørende retningslinjer:
Minste uteoppholdsareal skal oppfylle følgende kvalitetskrav:
- Alle boenheter bør ha maksimalt 100 meter trygg gangavstand fra hovedinngang i bygget til nærmeste del av uteoppholdsarealet på bakkeplan.
- Minst halve arealet bør ha sol i minst 3 timer ved vårjevndøgn etter klokka 12, samt klokka 18 midtsommers.
- Arealet bør være mest mulig sammenhengende, og små eller smale oppstykkede arealer skal unngås. Areal som er brattere enn 1:3 kan ikke medregnes hvis ikke arealet har særlige bruksverdier. Areal mindre enn to meter fra private vinduer inn mot oppholdsrom kan ikke medregnes som felles uteoppholdsareal.
- Areal som kreves lagt på bakkeplan skal ligge på naturlig terreng, eller på dekke med god terrengkontakt, dimensjonert for å kunne bære permanent vegetasjonsdekke.
- Tellende uteoppholdsareal bør være skjermet mot motorisert trafikk og forurensing, og tilfredsstille grenseverdiene i tabell 2 i T-1442/21. Unntak er inntil ¼-del av felles uteoppholdsareal i byggesone 1, som kan ha støy inntil 3 dB over grenseverdi angitt i T-1442/21, men areal særlig tilrettelagt for barn og unge kan ikke etableres her.

Tekniske installasjoner som trafokiosker, høyspentrom og lufteanlegg bør plasseres slik at de ikke reduserer kvalitet og bruksverdi på uteoppholdsarealene. Boenheter i første etasje bør ha oppholdsareal på terreng i direkte tilknytning til boenheten.

6.27. <u>§ 10.5 Etablering av hybler</u>
§ 10.5 i bestemmelsene strykes.

6.28. <u>§ 11.2 Vegetasjon</u>
Omgjøres i sin helhet til retningslinjer:
Verdifull vegetasjon bør i størst mulig grad etterstrebes bevart. Ved utarbeidelse av planforslag og søknad om tiltak bør det legges til rette for ny vegetasjon i form av trær og annen vegetasjon, grønne tak og fasader eller andre grønne elementer som kan bidra til å styrke naturmangfold og økosystemtjenester.

Verdifull vegetasjon er bytrær, store trær og annen vegetasjon med stor betydning for naturmangfold, kulturhistorie, stedsidentitet, landskapsbilde, lokalklima, fordrøyning, og/eller karbonlagring.

6.29. § 11.3 Karbonrike arealer
§ 11.3 endres slik:
Forslag om fjerning eller drenering av myr, og omdisponering av skog med høy bonitet, skal vurderes og utredes i hvert enkelt tilfelle.

6.30. § 12.1 Overvannshåndtering
§ 12.1 endres slik:
Planforslag og søknad om tiltak skal identifisere, dimensjonere og sikre arealer for overvannshåndtering og flomveger i tre trinn i tråd med Trondheim kommunes VA-norm og sanitærreglement.

Tilhørende retningslinje:
Overvann bør søkes utnyttet som positivt element i bymiljøet og styrke lokalt naturmangfold. Andre løsninger må begrunnes. Utfyllende beskrivelse av overvannshåndtering i tre trinn er gitt i Trondheim kommunes VA-norm. I "Middelalderbyen" skal overvannshåndtering planlegges i samråd med arkeologisk fagmiljø/Riksantikvaren.

6.31. § 12.2 Blågrønn faktor
Omgjøres i sin helhet til retningslinjer:
Alle planforslag bør dokumentere at Trondheim kommunes norm for blågrønn faktor kan oppfylles ved gjennomføring av planen. Ved tiltak som er omfattet av pbl § 20-1 a og l, bør Trondheim kommunes norm for blågrønn faktor være dokumentert oppfylt.

Ved andre tiltak eller tiltak etter reguleringsplan vedtatt før kommuneplanens arealdel 2022-2034 bør det tilstrebes å oppnå normkrav til blågrønn faktor.

6.32. § 12.3 Vassdrag
Omgjøres i sin helhet til retningslinjer:
Lukking av vassdrag eller andre tiltak som forringer økologiske funksjoner i og ved vassdrag er som hovedregel ikke tillatt. Nødvendige tiltak for drift, vedlikehold og fornying av eksisterende teknisk infrastruktur for veg og bane kan tillates, men skal i størst mulig grad ivareta økologiske funksjoner. Bredden på kantsonen på hver side av vassdraget skal være minimum 10 meter innenfor tettbebygde områder og 50-meter innenfor LNFR-områder.

Ved reguleringsplaner som berører lukkede eller sterkt påvirkede vassdrag bør det alltid vurderes om vassdraget kan gjenåpnes og restaureres. Ved behov skal det avsettes areal for tiltak mot partikkelavrenning og annen forurensning til vassdrag. Det bør legges vekt på å ivareta og der det er mulig reetablere et belte med naturlig kantvegetasjon.

6.33. § 13.1 [Mobilitet] Generelt
§ 13.1 endres slik:
Transportsystemet skal bidra til en attraktiv by, at flere går, sykler og reiser kollektivt og at viktige samfunnsfunksjoner har nødvendig fremkommelighet.

Tilhørende retningslinje:
Bystrukturen bør planlegges slik at byens gater og byrom gir et attraktivt og finmasket gangnett

som gir kort adkomst til viktige målpunkt.

Ved planlegging av nye samferdselsanlegg bør etablering av allé eller trær vurderes. For eksisterende alleer og trerekker bør trær og tilstrekkelig rotsone bevares. Allétrær som fjernes bør erstattes.

Fortau bør opparbeides med minst 2 meter asfaltert bredde og reguleres med 2,5 meter bredde for å inkludere skulderareal. I private blindveger uten gjennomgang kan 1,5 meter asfaltert bredde aksepteres hvis de betjener færre enn 50 boenheter.

6.34. § 13.2 Innenfor tettstedene
§13.2 endres slik:
Samferdselsanlegg innenfor byggesone 1-3 og ellers innenfor tettstedene skal som hovedregel utformes som gater for lav fart og med areal til blågrønne kvaliteter. Unntak er fjernveger og skinnegående transport.

Tilhørende retningslinje:
Tilrettelegging for kryssing for fotgjengere bør være på bakkeplan, unntatt over fjernveg. Annen løsning kan vurderes der alternativet sikrer en mer effektiv gang- og sykkelforbindelse. Planskilte kryss kan vurderes som et tillegg der dette er nødvendig for å sikre trygg skoleveg.

6.35. § 13.3 Snøopplag
§ 13.3 endres slik:
Langs offentlig veg skal det sikres areal til snøopplag.

Tilhørende retningslinje:
Areal til snøopplag sikres gjennom den enkelte reguleringsplan, på grunnlag av forventede snømengder.

Langs offentlig gate i byggesone 1 og 2 kan snøopplag løses i møbleringssoner og veggsoner. Utomhusplaner bør redegjøre for vintersituasjonen og tilstrekkelig areal for drift.

6.36. § 13.4 Mobilitetsutredning
§ 13.4 endres slik:
I planforslag skal det redegjøres for hvordan planforslaget vil bidra til at flere går, sykler og reiser kollektivt.

Tilhørende retningslinje:
Relevante tiltak fra mobilitetsutredningen bør sikres i reguleringsplanen.
Mobilitetsutredningen bør vise:
1. Forventet transportbehov: reiser til/fra bolig/virksomhet, besøksreiser, varelevering, godstransport.
2. Tilbud for gående, syklende, kollektivtrafikk og kjørende.
3. Trafikksikkerhet og fremkommelighet for gående, syklende, kollektivtrafikk og utrykningskjøretøy.
4. Tiltak for å bedre tilgjengeligheten for gående, syklende og kollektivreisende.
5. Parkeringstilbud for bil og sykkel, herunder plassering, utforming og ladeinfrastruktur. Det bør illustreres hvordan antall plasser er tenkt fordelt på personer med nedsatt funksjonsevne, beboere, besøkende,
kunder, tjenesteytere og bildeling. Det bør også fremkomme om parkering kan samlokaliseres med

andre boligfelt eller virksomheter i området.
6. Behov for regulering av offentlige gater i det aktuelle influensområdet for å begrense parkering utenfor eiendom.
7. Løsninger for renovasjon og varelevering.
8. For planlagt ny næringsbebyggelse skal det også foreligge en vurdering av om lokaliseringen er i samsvar med målsettingen om rett virksomhet på rett sted (§ 18).

6.37. § 13.5 Fjernveg
§ 13.5 endres slik:
Langs fjernveg skal effektiv og trafikksikker fremkommelighet for motoriserte kjøretøy prioriteres.
Tilhørende retningslinje:
Antall avkjørsler bør begrenses.
6.38. § 13.6 Hovedveg
§ 13.6 endres slik:
Langs hovedveg skal det sikres tilstrekkelig fremkommelighet for motoriserte kjøretøy.

Tilhørende retningslinje:
Det bør avsettes areal til kollektivfelt der dette er mulig og vurderes som nødvendig. Antall avkjørsler bør begrenses.

6.39. § 13.7 Kollektivtrasé
§ 13.7 endres slik:
Langs kollektivtrasé skal det sikres effektiv og trafikksikker fremkommelighet for buss.

Tilhørende retningslinje:
Det bør avsettes areal til kollektivfelt der dette er mulig og vurderes som nødvendig.

6.40. § 13.8 Sykkelnett
§ 13.8 endres slik:
Langs sykkelnettet skal det sikres et sammenhengende tilbud for syklende som oppleves som trygt og enkelt å bruke.

Tilhørende retningslinje:
Det bør sikres gjennomgående tilbud for sykkel i kryss.

Der sykkelnett sammenfaller med hovedveg og/eller kollektivtrasé bør det hovedsakelig tilrettelegges for beskyttet sykkelanlegg. Bruk av fortau og fotgjengeroverganger ved kryssing bør unngås som del av tilbudet for syklister i sykkelnettet.

6.41. § 13.9 Turveg
§ 13.9 endres i sin helhet til retningslinje:
Turveger vist på plankartet er viktige overordnede gangforbindelser som kobler turvegnettet sammen og gir sammenheng mellom marka og de andre overordnede grønne områdene. Turveger vist i byggeområder kan reguleres til og utformes som gangveg.

6.42. § 14.1 Antall parkeringsplasser for boligbebyggelse
Det skal avsettes plass for biler og sykler i samsvar med følgende norm:

Tabell 2 - Antall parkeringsplasser for boligbebyggelse

Byggesone	Sykkel	Bil – per 100 m2 BRA
Byggesone 1 – felt S1	Minimum 3 parkeringsplass pr. 100 m2, eller 1,5 parkeringsplass per boenhet.	Midtbyen: min 0/S1: min 0
Byggesone 1 – felt S2-S5		
Byggesone 2		
Byggesone 3		
Øvrige soner		
Frittliggende eneboliger og tomannsboliger i byggesone 3 og øvrige soner	4 pr. boenhet	min. 2 pr. boenhet

Avrundingsregel: Det rundes opp til nærmeste hele tall.

5.43. <u>§ 14.2 Antall parkeringsplasser for kontor, forretning og privat tjenesteyting</u>
§ 14.2 endres slik:
Det skal avsettes plass for biler og sykler per 100 m2 BRA i samsvar med følgende norm, gjelder ikke for virksomheters nyttekjøretøy:

Tabell 3 - Antall parkengsplasser for kontor, forretning og privat tjenesteyting

Sykkel			Bil		
Forretning	Kontor	Privat tjenesteyting	Forretning	Kontor	Privat tjenesteyting
Min. 1	Min. 1	Min. 1	Min. 1	Min. 0,1	Min. 0,5

Avrundingsregel: Det rundes opp til nærmeste hele tall.

6.44. <u>§ 14.3 Bilparkeringsplasser for personer med nedsatt bevegelsesevne</u>
§ 14.3 endres slik:
Ved søknad om tiltak og ved utarbeidelse av planer skal det etableres minst 1 plass, unntatt ved frittliggende en- og tomannsboliger. Kravet til antall plasser skal for øvrig være den høyeste verdien av enten:
- 5 prosent av alle bilparkeringsplassene
- 1 bilparkeringsplass pr. 1500 m2 BRA

Tilhørende retningslinje:
Etablering av slike parkeringsplasser bør ivareta følgende:
- Parkeringsplassene bør maksimalt ligge 25 meter fra hovedinngang.
- Parkeringsplassene bør fordeles mellom parkeringskjeller og gateplan, for å sikre et godt tilbud til ulike grupper av personer med nedsatt bevegelsesevne og biler med ekstra stor høyde.

6.45. <u>§ 14.4 Bilparkeringsplasser for besøkende og nyttekjøretøy</u>
§ 14.4 endres slik:
I tillegg til parkeringsplasser etablert etter § 14.1 og § 14.2, skal det etableres bilparkeringsplasser for besøkende og nyttekjøretøy.

Antall parkeringsplasser skal vurderes og fastsettes i den enkelte reguleringsplan.

Tilhørende retningslinje:
Det bør alltid sikres minst 1 parkeringsplass.

6.46. § 14.5.1 Plassering
§ 14.5.1 endres slik:
Plassering av parkeringsplasser skal vurderes og fastsettes i den enkelte reguleringsplan eller byggesak.

Tilhørende retningslinje:
Ved anleggelse av flere enn åtte parkeringsplasser, bør det vurderes å samle disse i felles parkeringsanlegg. Felles parkeringsanlegg bør anlegges ved kjøreadkomst fra veg.

6.47. § 14.5.2 Utforming
§ 14.5.2 endres slik:
Etablering av nye parkeringsplasser skal ta utgangspunkt i anbefalinger gitt gjennom SINTEFs anvisning for utforming og dimensjonering av parkeringsanlegg.
Ved vedlikehold av eksisterende anlegg kan 2,3 meters bredde aksepteres.

Tilhørende retningslinje:
Det bør sikres fri høyde på minst 2,6 meter på HC-parkeringsplass ved hovedinngang eller heis.

6.48. § 14.6 Plassering og utforming av sykkelparkering
§ 14.6 endres slik:
Sykkelparkering skal som hovedregel plasseres nær hovedinnganger. Det skal legges stor vekt på brukbarhet, tilgjengelighet og trygghet ved utforming. Plassering og utforming vurderes og fastsettes i den enkelte reguleringsplan eller byggesak.

6.49. § 15.1 Klimamål
§ 15.1 endres slik:
Alle reguleringsplaner og søknadspliktige tiltak skal planlegges og gjennomføres slik at den negative påvirkningen på klima og miljø gjennom livsløpet blir lavest mulig.

6.50. § 15.2 Klima- og energidokumentasjon
§ 15.2 endres slik:
Detaljplaner skal redegjøre for tiltak for å redusere behovet for tilført energi og belastningen planen vil ha på energisystemet i området. Ved utbygginger som samlet utgjør over 1000 m2 oppvarmet BRA, skal energibehov og energiforsyningsløsning beregnes.

Tilhørende retningslinje:
I planer og byggesaker bør det ved valg mellom riving og bevaring av eksisterende bygningsmasse synliggjøres hva som gir lavest energibehov i livsløpet.

6.51. § 15.3 Miljø - og energivennlig utforming
§ 15.3 endres slik:
Nye bygg skal gis en utforming som sikrer fleksibilitet og allsidig bruk. Plassering av bygninger og planlegging av tekniske løsninger skal tilstrebe å
redusere energi og effektbehovet, samt gjøre det mulig å høste lokal energi.

Tilhørende retningslinjer.
Bebyggelse og infrastruktur bør tilpasses terrenget for å redusere sprenging, graving og masseforflytting. Før bortregulering av eksisterende bygg bør ombrukspotensialet kartlegges. Det bør i størst mulig grad benyttes miljø- og klimavennlige materialer.

6.52. § 15.4 Fjernvarme
Ved utbygging eller ved hovedombygging med samlet areal over 1000 m2 BRA innenfor gjeldende konsesjonsområde for fjernvarme skal bebyggelsen tilknyttes fjernvarmeanlegg.

Tilhørende retningslinjer:
Det kan fritas for tilknytningsplikt til fjernvarme hvis det dokumenteres at klimagassutslippene ved andre energiløsninger er lavere, og/eller belastningen på el-nettet blir akseptabel. Nødvendig anleggsarbeid for å etablere løsningene bør inkluderes i klimagassberegningen.

Akseptabel belastning på el-nettet tilsier at varmeløsningen ved dimensjonerende utetemperatur ikke belaster el-nettet vesentlig mer enn tilsvarende bygg som tilfredsstiller gjeldende byggteknisk forskrift og som benytter fjernvarme som primærvarmekilde.

6.53. § 17.3 Næringsavfall
§ 17.3 endres slik:
I byggesone 1 og 2 skal næringsavfall løses innomhus.

Tilhørende retningslinjer:
I øvrige byggeområder skal næringsavfall løses på egen grunn og fortrinnsvis innomhus. Utomhus bør det tilstrebes nedgravde oppsamlingsløsninger.

I byggesone 1 og 2 bør det vurderes om næringsarealer kan ha felles renovasjonsløsning med husholdninger i samme bygg eller på nærliggende tomt.

6.54. § 17.4 Offentlig returpunkt og ombrukssentral
§ 17.4 endres slik:
Ved planlegging og oppføring av nye bygg på over 1000 m2 BRA i byggesone 1, 2 eller 3 må det avklares om det skal sikres areal til offentlige returpunkt for renovasjon.

Tilhørende retningslinje:
Ved planlegging av boliger i byggesone 1 og 2 bør areal til ombrukssentral vurderes.

6.55. § 18 Rett virksomhet på rett sted
§ 18 endres slik:
Virksomheter skal lokaliseres etter prinsippet rett virksomhet på rett sted. Støyende virksomheter og virksomheter med sikkerhetssoner skal etableres med god avstand fra boliger eller andre følsomme formål.

Tilhørende retningslinjer:
Prinsippet rett virksomhet på rett sted kan innebære:
- Arbeidsplassintensive virksomheter, som kontor, bør lokaliseres langs kollektivbuen mellom Sluppen og Strindheim, i tilknytning til kollektivknutepunktene Heimdal, Tiller og Strindheim, eller i lokale sentrumskjerner. I disse områdene bør arbeidsplassintensive virksomheter etableres innenfor byggesone 1, byggesone 2 eller fra andre etasje og opp innenfor formålet næringsbebyggelse.

- Publikumsrettede virksomheter, som handel, tjenesteyting og andre kultur- og servicetilbud som har kommunen eller regionen som omland, bør lokaliseres der de er lett tilgjengelige.
- Forretninger generelt kan lokaliseres i byggesone 1. Dagligvareforretninger tillates i alle byggesoner gjennom detaljreguleringsplan. Forretninger for plasskrevende varer kan tillates gjennom reguleringsplan innenfor arealer avsatt til næringsbebyggelse. BRA for handel defineres som summen av salgsflate, lagerlokale, spiserom/kantine og kontorareal som er nødvendig for driften. Areal til parkering og varelevering inngår ikke.
- Næringsvirksomheter med få besøkende, som bygg- og anleggsvirksomheter, håndverkere, teknologi og produksjonsvirksomheter, bør lokaliseres innenfor formålet næringsbebyggelse, eller innenfor byggesone 1-3. Virksomheter som ikke kan tilpasses bystrukturen eller fører til vesentlig støy- og trafikkbelastning for omgivelsene bør ikke lokaliseres i byggesone 1-3.
- Arealkrevende næringsvirksomheter med behov for nærhet til hovedvegnettet skal fortrinnsvis lokaliseres innenfor formålet næringsbebyggelse i felt merket NA.
- Ved arbeidsintensiv virksomhet/kontorformål bør det settes av areal til uteoppholdsareal for ansatte.

6.56. <u>§ 19.1 [Støy og stille områder] Statlig retningslinje T-1442</u>
§ 19.1 endres slik:
Retningslinje T-1442 skal legges til grunn ved planlegging og søknad om tiltak som gir nytt støyfølsomt bruksformål, herunder bruksendring, ved etablering av nye støykilder og vesentlig endring av eksisterende støykilder.

Tilhørende retningslinje:
Retningslinjens anbefalte støygrenser, angitt i tabell 2, og angitte kvalitetskriterier bør tilfredsstilles. Støynivå bør være premissgivende for valg av formål, plassering og planløsning. Ved etablering av støyfølsom bebyggelse i støysoner bør det utredes kompenserende kvaliteter som sikres i reguleringsbestemmelser.

6.57. <u>§ 19.2 Støyutredning</u>
§ 19.2 endres slik:
Støy fra veg, bane, havnevirksomhet, helikopter og industri skal utredes ved etablering av støyfølsomme formål. For veg, bane og helikopter skal støykart i kommunens kartløsning legges til grunn for vurdering av behovet for støyutredning.

Tilhørende retningslinje:
Med planforslag eller søknad om tiltak nevnt i § 19.1 bør det følge en støyfaglig utredning. Denne bør inneholde beregning og kartfesting av støysoner og støynivå på relevante høyder på fasader, vise påvirkning på støyømfintlig bruk i planens influensområde, samt forslag til avbøtende tiltak og en vurdering av effekten av disse.

6.58. <u>§ 19.5 Stille områder og grønnstruktur</u>
§ 19.5 endres slik:
I og i nærheten av stille områder vist i Temakart støysone veg og stille områder og formålet grønnstruktur, skal det dokumenteres at planlegging og søknad om tiltak ikke medfører en økning av støynivået i disse områdene.

Tilhørende retningslinje:
Lydpåvirkning (Lden) fra vegtrafikk, bane, trikk, helikopter, havne- og industrivirksomhet bør holdes under 55 dBA for grønnstruktur generelt og under 50 dBA for stille områder. Ved flere støykilder bør sumstøy vurderes. For andre støykilder bør grenseverdier i T-1442 brukes. Støynivå

fra tekniske installasjoner bør tilfredsstille samme krav som stilles til lydnivå ved boligfasade.

6.59. § 20.2 Luftkvalitet
§ 20.2 endres slik:
Alle tiltak skal planlegges slik at luftkvaliteten innendørs og utendørs blir tilfredsstillende. Miljøverndepartementets retningslinje for behandling av lokal luftkvalitet i arealplanlegging T-1520, skal legges til grunn for planforslag og tiltak etter pbl § 20-1, inkludert bygge- og anleggsfasen.

Tilhørende retningslinjer:
Det bør ikke tillates bebyggelse med formål som er følsom for luftforurensning nærmere tunnelåpninger enn 50 til 100 meter, avhengig av trafikkmengde.

Gul sone er en vurderingssone hvor det bør vises varsomhet med etablering av bebyggelse med bruksformål som er følsomt for luftforurensning. I gul sone bør det legges vekt på at uteoppholdsarealer får minst mulig eksponering og at det sikres godt inneklima. Dersom området også er utsatt for støy, skal den totale belastningen vurderes etter en helsefaglig vurdering.

6.60. § 20.3 Elektromagnetiske felt
Omgjøres til retningslinje og endres slik:
Ved etablering av boliger, barnehager, skoler og uteoppholdsområder nær høyspentanlegg eller transformatorstasjoner, skal det foretas en utredning av virkningene dersom det elektromagnetiske feltet ved gjennomsnittlig årlig strømbelastning overstiger 0,4 µT. Det samme gjelder ved etablering av høyspentanlegg eller transformatorstasjoner. Utredningene skal foreslå avbøtende tiltak.

6.61. § 21.2. Midlertidig massehåndtering og mellomlagring av ombruksmaterialer
§ 21.2 omgjøres til retningslinjer:
I planforslag for større utbyggingsområder med trinnvis utbygging skal det vurderes avsatt arealer til mellomlagring av overskuddsmasse og gjenbruksmaterialer fra egne og andre utbyggingsprosjekter i bydelen.

Muligheten for ombruk og materialgjenvinning bør vurderes og massebalanse tilstrebes.

6.62. § 22 Plan for bygge- og anleggsfasen
§ 22 endres slik:
Plan for beskyttelse av omgivelsene i bygge- og anleggsfasen skal foreligge før arbeidet kan igangsettes.

Nødvendige beskyttelsestiltak skal være etablert før bygge- og anleggsarbeider kan igangsettes. I bygge- og anleggsfasen det være god framkommelighet, trafikksikkerhet og orienterbarhet for gående, syklende og kollektivtransport.

Tilhørende retningslinjer:
Planen bør redegjøre for trafikkavvikling, massetransport, driftstider, støyforhold, rystelser og vibrasjoner, ivaretakelse av terreng og verdifull vegetasjon, renhold og støvdemping, framkommelighet og trafikksikkerhet for gående, syklende og kollektivtransport, håndtering av avrenning for å ivareta hensyn til vannmiljø og avløpsnett samt tiltak for å redusere klimagassutslipp.

Tiltakshaver er ansvarlig for at planen foreligger, at planen er tilgjengelig på bygge-/anleggsplassen og at den er kjent for foretakene som utfører arbeid. Det bør vises hvordan kravene

i §§ 15.4, 19.6 og 20.2 tilfredsstilles og dokumenteres i bygge-og anleggsfasen. Ved større prosjekter bør planen revideres. Ved flere utbygginger i samme område bør tiltakene samordnes.

6.63. § 23.1 Felles formålsbestemmelser byggesone 1-4
Følgende legges til i § 23.1:
Det skal utvises fleksibilitet ved endring og/eller utvikling av eiendom som ligger i eller nært opp til overgangen mellom byggesoner.

6.64. § 23.2 Felles bestemmelser byggesone 1 og 2
§ 23.2 endres slik:
Områdene skal utvikles etter bymessige prinsipper, med høy tetthet og kvalitet, og sammenhengende byromsnettverk.

Ny bebyggelse skal utformes og plasseres slik at den ikke er til hinder for at omkringliggende eiendommer kan utvikles med tilsvarende tetthet og kvalitet, der hvor dette kan være aktuelt.

Tilhørende retningslinjer:
- Første etasje, herunder areal på bakkeplan trukket inn under tak, ut mot sentrale offentlige gater, gangveger og byrom bør i hovedsak ikke inneholde parkeringsanlegg, boder og lager, samt større rom for tekniske anlegg.
- Langs fasader som henvender seg mot hovedgater og offentlige byrom bør det vurderes etablert utendørs møbleringssone som muliggjør tilrettelegging for utendørs byliv.
- Stopp for tjeneste- og varelevering og renovasjonsbiler bør fortrinnsvis etableres i forbindelse med møbleringssone langs sidegater.
- Det skal tilstrebes et finmasket gangnett. Ved planlegging av ny bebyggelsesstruktur bør kvartaler ha maksimal bredde/lengde på 70 meter, og fasadene underdeles med sprang i fasadeliv og variert material- og fargebruk minst hver 30 meter.
- Føresteetasjer ut mot sentrale offentlige gater, gangveger og byrom bør ligge på samme nivå som gateplan for å muliggjøre innganger fra gata. Felles oppholdsrom for flere boenheter, kantiner eller lignende skal fortrinnsvis plasseres her. Som en mindre del av møbleringsarealet langs gater kan det etableres langsgående offentlig korttidsparkering for besøkende, HC parkering og taxi.

6.65. § 23.3.2 Arealbruk (byggesone 1)
§ 23.3.2 endres slik:
Innenfor byggesone 1 tillates sentrumsformål, idrettsanlegg og næringsbebyggelse.

Tilhørende retningslinjer:
Bebyggelsens første etasje ut mot sentrale offentlig gater og byrom bør fortrinnsvis inneholde utadrettet virksomhet, eventuelt innendørs fellesareal og kantiner.

Første etasje i nye bygg bør ikke inneholde boenheter ut mot sentrale offentlige gater, gangveger og byrom, dersom arealet vurderes som egnet til fellesfunksjoner eller publikumsrettet virksomhet.

6.66. § 23.3.3 Utforming av bystruktur og bebyggelse
§ 23.3.3 i bestemmelsene strykes.

6.67. § 23.3.4 Bymiljø
§ 23.3.4 i bestemmelsene strykes.

6.68. § 23.4.2 Arealbruk (byggesone 2)
§ 23.4.2 endres slik:
Innenfor byggesone 2 tillates sentrumsformål, idrettsanlegg og næringsbebyggelse.

Tilhørende retningslinjer:
Forretning knyttet til service- og håndverksvirksomheter tillates på inntil 25 % av virksomhetens BRA. I eksisterende bebyggelse av antikvarisk verdi klasse A-C tillates formål som kan bidra til at bebyggelsen fortsatt kan være i bruk.

6.69. § 23.5.1 Utnyttelsesgrad (byggesone 3)
§ 23.5.1 endres slik:
Grad av utnytting tilpasses områdets strøkskarakter, samtidig som hensiktsmessig utnyttelse av arealet sikres.

Tilhørende retningslinjer:
I*varetakelse av eksisterende bomiljø, naturverdier og kulturhistoriske verdier bør tillegges vekt ved nye bygninger og andre tiltak.*

Ved planlegging av større nye byggeområder eller transformasjonsområder bør det legges vekt på effektiv arealbruk innenfor de rammene som for øvrig er gitt i bestemmelsene. Andel areal på bakkeplan avsatt til kjøring og parkering bør begrenses.

6.70. § 23.5.2 Arealbruk (byggesone 3)
§ 23.5.2 endres slik:
Innenfor byggesone 3 tillates sentrumsformål, idrettsanlegg, og næringsbebyggelse.

Tilhørende retningslinje:
Forretning knyttet til service- og håndverksvirksomheter tillates på inntil 25 % av virksomhetens BRA.

I eksisterende bebyggelse av antikvarisk verdi klasse A-C tillates formål som kan bidra til at bebyggelsen fortsatt kan være i bruk

6.71. § 23.6.1 [Byggesone 4] Utnyttelsesgrad
§23.6.1 endres slik:
Grad av utnytting skal ikke overstige 50 % BRA.

Tilhørende retningslinje:
Ivaretakelse av eksisterende bomiljø, naturverdier og kulturhistoriske verdier bør tillegges stor vekt ved nye bygninger og andre tiltak.

6.72. § 23.6.2 Arealbruk (byggesone 4)
§ 23.6.2 endres slik:
Innenfor byggesone 4 tillates sentrumsformål, idrettsanlegg, og næringsbebyggelse.

Tilhørende retningslinje:
Areal bør i hovedsak benyttes til bolig. For eksisterende bebyggelse av antikvarisk verdi klasse A-C tillates formål som kan bidra til at bebyggelsen fortsatt kan være i bruk.

6.73. § 24.1.1 [Fritidsbebyggelse] Generelle bestemmelser

§ 24.1.1 endres slik:
Det må foreligge godkjent avløpsløsning med felles ledningsnett knyttet til kommunalt nett eller eget renseanlegg før igangsettingstillatelse kan gis.

Tilhørende retningslinje:
Fritidsbebyggelse bør tilpasses tomtearealet, og som hovedregel ha maksimalt 80 m2 BRA for hovedbygg.

6.74. § 24.1.2 Felt F1 Selbusjøen
§ 24.1.2 endres slik:
Innenfor feltet tillates fritidsboliger.

6.75. § 24.1.3 Kolonihage Grendstad
§ 24.1.3 endres slik:
Innenfor området tillates parseller med bebyggelse.

Tilhørende retningslinje:
Avstanden mellom bebyggelsen på parsellene og Selbusjøen bør være minst 30 m. På hver parsell kan det etableres bebyggelse på inntil 30 m2.

6.76. § 24.2 Tjenesteyting (1160)
§ 24.2 endres slik:
Arealene vist som tjenesteyting skal benyttes til barnehager, skoler, helse- og omsorgsinstitusjoner, brannstasjoner, fengsel, museer og kirker/religiøse forsamlingslokaler. Idrettsanlegg tillates etablert innenfor formålet.

Tilhørende retningslinjer:
Felles bestemmelser for byggesone 1 og 2 - § 23.2 og tilhørende retningslinjer - bør gjelde for utforming av bebyggelse, bymiljø og samferdsel innenfor formålet tjenesteyting. Det bør legges vekt på effektiv arealbruk innenfor de rammene som for øvrig er gitt i bestemmelsene.

Minimum uteoppholdsareal til offentlig tjenesteyting:
- Barnehager: 24 m2 godt egnet uteoppholdsareal per barn.
- Skole: 25 m2 godt egnet uteoppholdsareal per elev. Deler kan være regulert som offentlig friområde.
- Helse- og velferdssenter: 25 m2 godt egnet uteoppholdsareal per 100 m2 bruksareal.

6.77. *§ 24.3* Råstoffutvinning (1200)
Ved planforslag og behandling av søknad om råstoffutvinning skal det foreligge en vurdering av miljøbelastninger for influensområdet knyttet til driften og transport til og fra området, geotekniske forhold, landbruksfaglige forhold, landskap/ stedskvalitet og biologisk naturmangfold.

Tilhørende retningslinjer:
Etterbruk til LNFR bør sikres i reguleringsplan. Jordbruksarealer bør istandsettes til jordbruksdrift. Felt merket RN kan ha næringsbebyggelse som etterbruk. Dette bør sikres i reguleringsplan.

T-1442 og T-1520 skal ligge til grunn for vurderingene av støy og luftkvalitet.

6.78. § 24.4.1 [Næringsbebyggelse]
§ 24.4.1 endres slik:

Innenfor formålet kan det etableres næringsvirksomheter i tråd med prinsippet for rett virksomhet på rett sted. Energianlegg tillates. Ved søknad om tiltak gjelder formål angitt i vedtatt reguleringsplan foran formål angitt i arealdelen dersom motstrid.

Tilhørende retningslinjer:
Innenfor arealer avsatt til næringsbebyggelse bør det kun tillates håndverk og industri (1340), lager (1350) og bensin-/energistasjon (1360), samt energianlegg. Dette med unntak av 1) på Strindheim mellom jernbanen og Innherredsveien, hvor det fra andre etasje og opp kan etableres kontor, og 2) på Tunga, der næringsarealene bør forbeholdes industri, plasskrevende varehandel og næringer samt produksjons- og lager/logistikkvirksomheter. Kontorlokaler fra andre etasje og opp kan her tillates gjennom reguleringsplan. (1310) Kontor fra andre etasje og opp over forretninger for plasskrevende varehandel tillates som hovedregel ikke.

Innenfor felt merket NA bør næringsarealene forbeholdes større produksjons- og lager/logistikkvirksomheter med behov for stort, sammenhengende areal.

På Tiller i felter merket NF kan det vurderes tillatt forretning for plasskrevende varegrupper gjennom reguleringsplan. Det vises for øvrig til retningslinjene under § 18 Rett virksomhet på rett sted.

Det vises for øvrig til retningslinjene under § 18 Rett virksomhet på rett sted.

6.79. <u>§ 24.4.2 Utnyttelse og utforming</u>
§ 24.4.2 endres slik:
Effektiv arealutnyttelse skal ivaretas gjennom høy tetthet tilpasset omgivelsene og områdets tilgjengelighet i henhold til prinsippet om rett virksomhet på rett sted.

Tilhørende retningslinjer:
Alle planforslag og søknader om tiltak bør vise hvordan plassering og utforming av bebyggelse og adkomster bidrar til effektiv arealutnyttelse for tomta og tilsluttende næringsarealer. Det bør primært etableres felles renovasjon og varelevering. Varelevering bør etableres slik at det ikke er til unødig ulempe for omgivelsene.

For å sikre tilstrekkelig areal til virksomhetenes arealkrevende funksjoner bør arealene på bakkeplan både ute og inne reserveres til disse funksjonene. I ytterkant av næringsområdene, mot samferdselsanlegg, boliger og andre områder for opphold, bør det etableres visuell skjerming ved bruk av vegetasjon. Dette gjelder ikke for nåværende næringsbebyggelse langs Haakon VII's gate vest for Leangen allé.

Det bør legges til rette for uteoppholdsareal for ansatte.

Belysning skal utformes slik at landbruks-, natur- og friluftslivsområder skjermes mot lysforurensning.

6.80. <u>§ 24.4.3 Tilrettelegging for næringstransport</u>
§ 24.4.3 endres slik:
Det skal sikres god framkommelighet for næringstransport i områder for næringsbebyggelse.

Tilhørende retningslinjer:
Ved regulering av arealkrevende næring bør det legges til rette for lade- og fylleinfrastruktur

dersom behovet i området ikke er dekket.

6.81. § 24.5 Idrettsanlegg (1400)
§ 24.5 endres slik:
Ved detaljregulering skal det i tillegg til idrettsanlegg legges til rette for grønne forbindelser.

Tilhørende retningslinjer:
Ved detaljregulering bør det i tillegg til idrettsanlegg og grønne forbindelser også legges til rette for anlegg for egenorganisert aktivitet.

6.82. § 24.6.2 Massedeponi
§ 24.6.2 endres slik:
Ved detaljregulering og søknad om etablering av massedeponi skal det foreligge en plan for drifts- og anleggsfasen. Planen skal sikre naturverdier og trinnvis utvikling av deponiet, slik at naturverdier ivaretas fram til området tas i bruk.

Tilhørende retningslinjer:
Planen bør også redegjøre for miljøbelastninger knyttet til drift og transport til og fra deponiet for influensområdet, geotekniske forhold, landbruksfaglige forhold, landskap/stedskvalitet, og naturmangfold og vannmiljø. Etterbruk bør sikres i reguleringsplan. Jordbruksarealer bør istandsettes for jordbruksdrift. Felt merket MN kan ha næringsbebyggelse som etterbruk. Dette bør sikres i reguleringsplan.

Ved etablering av nye massedeponi eller ved vesentlige utvidelser, bør det vurderes sorteringsanlegg og muligheter for gjenbruk av rene masser.

6.83. § 24.7.1 Effektiv arealbruk
Bestemmelse § 24.7.1 endres til retningslinje:
Ved planlegging og utbygging av nye byggeprosjekter bør det legges vekt på effektiv arealbruk innenfor de rammene som for øvrig er gitt i bestemmelsene.

6.84. § 24.7.2 Knutepunkter KB1
§ 24.7.2 endres slik:
Innenfor felter merket KB1 på Heimdal, Tiller og Tempe tillates tjenesteyting, idrettsanlegg og næringsbebyggelse.

Tilhørende retningslinje:
Felles bestemmelser og retningslinjer for byggesone 1 og 2 (§ 23.2) bør gjelde for utforming av bebyggelse, bymiljø og samferdsel innenfor områdene.

6.85. § 24.7.5 Øvre Rotvoll (trekanttomta)
§ 24.7.5 Øvre Rotvoll (trekanttomta)
Innenfor området tillates kommunaltekniske anlegg, næringsbebyggelse, energianlegg, energistasjon, renovasjonsanlegg og kollektivanlegg. Det skal legges til rette for lade- og fylleinfrastruktur.

Tilhørende retningslinje:
I ytterkant av feltet, mot samferdselsnettet, skal det etableres visuell skjerming ved bruk av vegetasjon.

6.86. § 24.7.6 Tungavegen 28-38

§ 24.7.6 Tungavegen 28-38:
Innenfor feltet tillates sentrumsformål og næringsbebyggelse.

6.87. § 25.1 Opparbeidelse og bruk
§ 25.1 endres slik:
Formålet omfatter naturområder, turdrag, friområder og parker. Sammenhengene i blå/grønnstrukturen, eksisterende naturverdier og økologiske funksjoner skal ivaretas og styrkes.

Tilhørende retningslinjer:
Tiltak for å fremme friluftsliv, lek og rekreasjon tillates. Andre tiltak tillates som hovedregel ikke. Unntak er bruk av bebyggelse med antikvarisk verdi klasse A-C, som kan benyttes til funksjoner innenfor formålene tjenesteyting og bevertning.

Arter oppført på listen over fremmede arter og/eller definert som problemart i Trondheim skal unngås i blå/grønnstrukturen. Det bør i størst mulig grad brukes vegetasjon som er naturlig for stedet.

6.88. § 25.2 Offentlige parker
§ 25.2 endres slik:
Arealene skal gi tilbud til alle og være offentlig tilgjengelige. Overvannshåndtering skal være ivaretatt.

Tilhørende retningslinjer:
Materialbruk og utførelse bør ha høy kvalitet og sikre lang levetid ved høy bruksintensitet. All vegetasjon bør sikres gode vekstforhold. Der offentlig park etableres på tak eller konstruksjoner under bakken bør konstruksjonen dimensjoneres til å tåle etablering av trær, vegetasjon og jordoverdekning, samt vedlikeholdskjøretøy.

6.89. § 25.3 Felt B - fremtidige offentlig parker og torg
§ 25.3 i bestemmelsene strykes.

6.90. § 26.1 [LNFR] Generelle bestemmelser
§ 26.1 endres slik:
I LNFR-områder er det ikke tillatt å gjøre bruksendringer eller oppføre nye bygninger, nye boenheter eller andre konstruksjoner og anlegg. Det samme gjelder fradeling til slike formål. Unntatt er tiltak knyttet til stedbunden næring, og tiltak som kan styrke ressursgrunnlaget i landbruket.

Tilhørende retningslinjer:
Ved søknad om fradeling av eksisterende bolig som er en følge av bruksrasjonaliseringstiltak i landbruket, godkjent etter jordlov og konsesjonslov, kan dispensasjon vurderes. Fradeling av boenheter tilknyttet
tunet tillates ikke.

I LNFR-områder legges hensynet til landbruk, natur og allmenn rekreasjon til grunn for kommunens forvaltning. Det tas særlig hensyn til langsiktig forvaltning av natur- og kulturlandskapet.

For endringer på bebygde eiendommer legges det vekt på tiltakets tilpasning på eiendommen og helhetlige kulturlandskapsvurderinger. Nybygg og tilbygg tilknyttet landbruket skal tilpasses

eksisterende bygningsmiljø og landskapet.

6.91. § 26.2 Våningshus for landbruksdrift
§ 26.2 endres slik:
Det tillates inntil to våningshus.

Tilhørende retningslinjer:
Våningshuset bør plasseres i tilknytning til tunet på landbrukseiendommen, og utformes på en slik måte at den blir en naturlig del av det tradisjonelle kulturlandskapet, samt tilpasses eksisterende bygningsmasse når det gjelder takvinkler, materialvalg, farger og stilart.

Våningshuset bør som hovedregel ikke berøre dyrka jord (fulldyrka eller overflatedyrka) jf. digitale markslagskart AR5 (gårdskart) med mindre det ikke finnes andre alternativ.

6.92. § 26.3 Fritidsbebyggelse
§ 26.3 endres slik:
Søknad om oppføring av ny eller utvidelse av bestående fritidsbebyggelse skal vurderes i hvert tilfelle. Det samme gjelder for bruksendring fra fritidsbebyggelse til bolig.

Tilhørende retningslinje:
Oppføring av ny eller utvidelse av bestående fritidsbebyggelse, samt bruksendring fra fritidsbebyggelse til bolig, bør som hovedregel ikke tillates.

6.93. § 27.4 Friluftsområde (6700)
§ 27.4 endres slik:
Innenfor områder avsatt til friluftsområde i sjø og vassdrag skal det tas hensyn til ferdsel, rekreasjon, lek og opphold i sjøen. Anlegg, tiltak og aktivitet til ulempe for friluftsliv eller opplevelsesverdi, herunder bruk av motordrevne fartøy, er ikke tillatt. Dette gjelder ikke for transportkjøring inntil 5 knop for turistbåter med godkjenning og kjøretøy som ivaretar og rutegående transport etter yrkestransportlova, sikkerhetstjenester, eller drift og vedlikehold av friluftsområdene.

Følgende aktiviteter er ikke underlagt fartsbegrensing:
- Forsvarets øvelser, forflytninger og transporter
- Politi-, rednings-, brannverns- og ambulansetjenester, tiltak i forbindelse med akutt forurensning, samt oppsyns- og tilsynstjeneste

6.94. § 28.3.1 Ferdsel og opphold
§ 28.3.1 punkt b endres slik:
Det er forbudt å sette opp telt, parkere bobil eller lignende, eller på annen måte slå leir med formål om overnatting.

6.95. § 28.3.2 a) Grunneiere og andre rettighetshavere
§ 28.3.2 punkt a endres slik:
Det er forbudt å gjennomføre tiltak som kan ha vesentlig negativ innvirkning på drikkevannskvaliteten. Forbudet gjelder ikke tiltak som omhandler vedlikehold og oppgradering av eiendom og bygningsmasse, innfrielse av krav som følger av drikkevannshensyn eller tiltak knyttet til det offentlige drikkevannsanlegget. Tiltak som ikke legger opp til vesentlig endret eller utvidet bruk vil normalt kunne godkjennes.

6.96. § 28.3.2 e) Grunneiere og andre rettighetshavere
§ 28.3.2 punkt e endres slik:
Det er forbudt å drive hoteller, herberger, utleiehytter, ridesenter, kennel eller lignende virksomheter.

6.97. § 28.4 j) Sikringssone drikkevann (110) Jessmokilden
§ 28.4 Sone 1 punkt j endres slik:
Det er forbudt å sette opp telt, parkere bobil eller lignende, eller på annen måte slå leir med formål om overnatting.

6.98. § 28.5 a) Sikringssone drikkevann (110) - Høydebassengene Reppeåsen, Steinan og Høgåsen og Vikåsen rentvannstunnel
§ 28.5 punkt a endres slik:
Det er forbudt å gjennomføre tiltak som kan ha vesentlig negativ innvirkning på drikkevannskvaliteten. Forbudet gjelder ikke tiltak som omhandler vedlikehold og oppgradering av eiendom og bygningsmasse, innfrielse av krav som følger av drikkevannshensyn eller tiltak knyttet til det offentlige drikkevannsanlegget. Tiltak som ikke legger opp til vesentlig endret eller utvidet bruk vil normalt kunne godkjennes.

6.99. § 28.5 g) Sikringssone drikkevann (110) - Høydebassengene Reppeåsen, Steinan og Høgåsen og Vikåsen rentvannstunnel
§ 28.5 punkt g endres slik:
Det er forbudt å sette opp telt eller på annen måte slå leir med formål om overnatting.

6.100. § 28.7.1 [Avfallsdeponi] Arealbruk
§ 28.7.1 endres slik:
Det tillates boligbebyggelse og annen sårbar bebyggelse i randsone til deponi i de områdene som er svært viktige for byutviklingen og i tråd med byutviklingsstrategien og nullvekstmålet. Bygging av andre formål tillates på og i randsone til deponi.

Ved bygging av sårbar bebyggelse på avfallsdeponi, som for eksempel bolig, barnehage, helsebygg og undervisningsbygg, skal avfallet som hovedregel fjernes under bebyggelsen. Areal der deponimasser er fjernet skal betraktes som ordinær byggetomt eller randsone til deponi.

Utvikling på og ved nedlagte deponier vurderes hver for seg, og det må gjøres nødvendige sikringstiltak som hindrer inntrenging av gass fra deponiet inn i bebyggelse i den enkelte reguleringsplan.

Ved opprydding av gamle avfallsdeponier skal muligheten for ombruk og materialgjenvinning utredes og vurderes. Masser som etter opprydding av deponi ikke utgjør risiko for gassproduksjon eller setninger ved nedbryting kan gjenbrukes som fyllmasse under bebyggelse.

Nettstasjon tillates ikke plassert i rom under bakkeplan innenfor hensynssonen.

Det vises til Miljødirektoratets veileder "Bygging på nedlagte deponier" for ytterligere krav ved detaljregulering innenfor faresonen.

6.101. § 29.1 Hensynssone landbruk (H510) - grønn strek
§ 29.1 i bestemmelsene strykes, og hensynssonen tas ut av plankartet.

6.102. § 30.3 Båndlegging i påvente av detaljregulering - Øvre Rotvoll og Presthus (H710_2)

§ 30.3 i bestemmelsene strykes, og båndleggingssone for dette arealet tas ut av plankartet.

6.103. § 32.2 Bestemmelsesområde #2, Byøkologisk forsøksområde miljøkvalitet
§ 32.2 i bestemmelsene strykes, og bestemmelsesområde #2 tas ut av plankartet.

6.104. § 32.3 Bestemmelsesområde #3, Mobilitetshus
§ 32.3 i bestemmelsen strykes, og bestemmelsesområde #3 tas ut av plankartet.

6.105. § 32.4 Bestemmelsesområde #4, Sjøbad Strandveikaia
§ 32.4 i bestemmelsen strykes, og bestemmelsesområde #4 tas ut av plankartet.

6.106. § 32.5 Bestemmelsesområde #5, Støy langs E6
§ 32.5 i bestemmelsen strykes, og bestemmelsesområde #5 tas ut av plankartet.

6.107. § 32.6 Bestemmelsesområde #6, Offentlig tjenesteyting
§ 32.6 endres slik:
Før planlegging eller gjennomføring av tiltak innenfor området skal behov for offentlig tjenesteyting avklares.

6.108. § 32.8 Bestemmelsesområde #8 og #9, Framtidig godsterminal.
Innenfor områdene #8 på Heggstadmoen og #9 på Torgård skal alle søknader om tiltak etter pbl § 1-6 forelegges jernbanemyndighetene for uttalelse før eventuell tillatelse kan gis. Dette gjelder inntil jernbanemyndighetene beslutter endelig lokalisering eller frafaller behovet for areal til ny godsterminal for Trondheimsregionen.

7. Andre forslag

7.1. Fortetting av eksisterende næringsareal
Bystyret ber om at kommunen har dialog med relevante aktører for å bidra til økt utnyttelse og fortetting av eksisterende næringsareal slik at vi får raskere transformasjon av sentrale områder.

7.2. Næringsareal
Bystyret ber kommunen fortløpende sikre klargjøring og tilrettelegging av næringsareal avsatt i kommuneplanens arealdel (KPA), slik at et mål om 3000 dekar næringsareal kan oppnås.

7.3. Parkering ved helse- og velferdssentre
Det må planlegges for et betydelig høyere antall parkeringsplasser for ansatte og pårørende ved bygging av nye helse- og velferdssentre, enn det som er praksis i dag. Alle tall i tabell for Veiledende norm for bilparkering på side 17 i parkeringsveilederen gjøres til minimumskrav.

7.4. Hensynssone bevaring naturmiljø:
Hensynssone bevaring naturmiljø må følge den blågrønne strukturen, og ikke overlappe byggesonen, eksempelvis på Ladehalvøya.

7.5. Justering av markagrensa - Lian og Kystadmarka
Markagrensa skal justeres, slik at eiendommer omfattet av r20200039, Detaljregulering av Lian og Kystadmarka, kan omdefineres til byggesone 4 uten de restriksjoner som følger av rød strek.

7.6. Justering av markagrensa - Strindamarka
Markagrensa skal justeres, slik at eiendommer langs Estenstadvegen og Kleivavegen kan omdefineres til byggesone 4 uten de restriksjoner som følger av rød strek.

Berit Tiller (H) fremmet følgende alternative forslag på vegne av H, KrF, MDG, SP, SV, V, PP:
KPA: Forslag til sluttbehandling på vegne av sentrum - Høyre og SV

Helhetlig forslag KPA Sentrum - Høyre og SV

1. Bystyret vedtar forslag til ny kommuneplanens arealdel 2022-2034 som vist på kart i målestokk 1:40 000, senest datert 07.05.2024, unntatt 911 Øvre Rotvoll Sør og 912 Øvre Rotvoll (trekanten) og områdene som er omfattet av bystyrets øvrige vedtakspunkter i saken.

2. Bystyret vedtar bestemmelser senest datert 07.05.2024 og beskrevet i planbeskrivelsen, senest datert 07.05.2024, med de endringer som følger av bystyrets vedtak.

3. Bystyret vedtar endringer i forslaget til KPA 2022-2034 som vist i vedlagte PDF.

4. Saksdokumentene til kommuneplanens arealdel 2022-2034 skal korrigeres slik det framgår av Tilleggsnotat 11 - Korrigeringer av Kommunedirektørens forslag til sluttbehandling, datert 06.06.2024.

5. Arealdelen vedtas med rettsvirkning ved Bystyrets vedtak, jf. plan- og bygningsloven § 11-6. Dette med unntak av de avgrensede utbyggingsområdene som det er knyttet innsigelser til, jf. plan- og bygningsloven § 11-16. Disse tas opp til mekling og eventuell videre behandling hos Kommunal- og distriktsdepartementet, jf. plan- og bygningsloven § 5-6.

6. Lianvatnet skole/Haukåsen (126) beholder formål som foreslått i kommunedirektørens innstilling. Byrådet bes sørge for at utarbeidelse av ny reguleringsplan som vil gjelde foran KPA 2022-2034 legges inn i kommunens planstrategi.

Vedtaket fattes i henhold til plan- og bygningsloven § 11-15.

Areal
Område 864 og deler av 5 Tilbakeføre Tillermarka til LNF
Markagrensa (rød strek) vest i Tillermarka justeres i henhold til markagrensa i kommuneplanens arealdel 2007-2012, unntatt areal regulert til bebyggelse og anlegg i reguleringsplan for Torgårdsvegen (planID r20150033). Arealet avsettes til landbruk, natur og friluftsformål (LNFR). Hensynssone for naturtypen ravinelandskap i Tillermarka opprettholdes. Kart endres i tråd med dette.

Område 9/933 Fossegrenda
Område 9/933 Fossegrenda får fremtidig kombinert bebyggelse og anlegg KB5 som formål.

Område 28 Valkyrjeveien 7
Område 28 Valkyrjeveien 7 får byggesone 2 som formål.

Område 35 Leirfossveien (Fossegrenda)
Område 35 Leirfossvegen får næringsbebyggelse som formål.

Område 41 Røddevegen
Område 41 Røddevegen får næringsbebyggelse som formål.

Område 50 Bratsbergvegen 139
Del av område 50 Bratsbergvegen 139 og dagens næringsbebyggelse får næringsbebyggelse som formål, som vist i kartutsnittet under.

Område 51 Sandmoen
Område 51 Sandmoen får næringsbebyggelse og overnatting som formål

Område 55 Innherredsveien
Område 55 Innherredsveien får byggesone 3 som formål.

Område 57 Selsbakk
Areal avsatt til blå/grønnstruktur endres til byggesone 3 i tråd med kartutsnitt i kommunedirektørens tilleggsnotat 9.

Område 93 Heimdalsvegen
Område 93 får to arealformål: Del som er dyrka mark i dag får LNFR som foreslått til sluttbehandling. Resterende del får næringsbebyggelse som formål. Avgrensning for næringsareal vises i kartutsnittet under.

Område 106/58 Flatåsen
Deler av område 58 som er foreslått til næringsbebyggelse endres til byggesone 2. Område 106 som ikke overlapper 58 settes av til fremtidig næringsbebyggelse, jfr vedlagte illustrasjon.

Område 124 Gamle Ladejarlen
Område 124 Gamle Ladejarlen får byggesone 2 som formål. For den delen av området som grenser til blågrønn struktur skal hensynssonen ikke overlappe byggesonen.

Område 127 Moksneslia
Område 127 Moksneslia får formål byggesone 3.

Område 142 Eklestrøa
Fordeling av formål gjennomføres som i hovedhøringen. Byggeområdene holdes utenfor forbudsgrense vassdrag Nidelvkorridoren.

Område 315 Porsmyra
Foreslått endring til fremtidig offentlig tjenesteyting gjennomføres ikke, formål settes til blå/grønnstruktur i tråd med KPA 2012-2024.
Område 320 Fjellseterveien - Offentlig tjenesteyting/barnehage
Formål offentlig tjenesteyting erstattes med blå/grønnstruktur og byggesone 1 S4 med fordeling som i KPA 2012-2024

Område 320 Fjellseterveien - Offentlig tjenesteyting/barnehage
Formål offentlig tjenesteyting erstattes med blå/grønnstruktur og byggesone 1 S4 med fordeling som i KPA 2012-2024

Område 331 - Offentlig tjenesteyting/skole Blyberget
Offentlig tjenesteyting/skole Blyberget tas ut, og formål settes til LNFR. Rød strek beholdes som i KPA 2012-2024.

Område 352 Offentlig tjenesteyting/barnehage Østmarka
Offentlig tjenesteyting/barnehage Østmarka tas ut, og formål settes til LNFR.

Område 404 Tiller sør
Område 404 Tiller sør får formål byggesone 1 S2, i tråd med KPA 2012-2024.

Område 920 Myrsundet
Område 920 Myrsundet får framtidig næringsbebyggelse som formål, jf. kartutsnitt under.

Område 921 Offentlig tjenesteyting/HVS Wullumsgården
Offentlig tjenesteyting (Helse- og velferdssenter) Wullumsgården tas ut, og formål settes til LNFR. Rød strek beholdes som i KPA 2012-2024. HVS kan bygges ut som en del av byggesone 1 og byggesone 2 sør for Fjellseterveien

Område 924 Berg prestegård
Deler av område 924 Berg prestegård får byggesone 2 som formål, jf. kartutsnitt under.

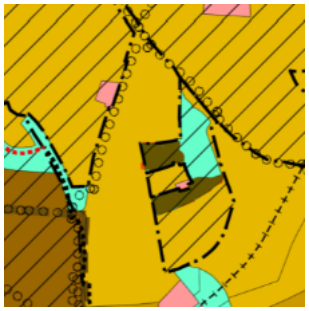

Område 937 Østmarka
Område 937 Østmarka får formål blå/grønnstruktur.

Område 941 Ranheimsvegen 305
Område 941 Ranheimsvegen 305 får byggesone 4 som formål

Område 945 Brøsetekra 5, 7, 11
Område 945 Brøsetekra får byggesone 2 som formål.

Område 950 NGU-tomta på Østmarka, gnr/bnr 413/21
Område 950 NGU-tomta på Østmarka, gnr/bnr 413/21, får formål offentlig tjenesteyting.

Område 956 Universitetsområdet Dragvoll
De deler av område 956 som har byggesone 3 som formål endres til formål framtidig næringsbebyggelse. Områdene som er avsatt til idrettsanlegg endres ikke, inkludert område 208 og 209 på søndre og nordre parkeringsplass

Båndleggingssoner i påvente av detaljregulering tas ut
Båndleggingssonene H710_1 (Østmarka) og H710_2 (Øvre Rotvoll og Presthus) tas ut av

kartet, og tilhørende bestemmelser 30.2 og 30.3 strykes

Nytt bestemmelsesområde for bynaturpark
Det opprettes et nytt bestemmelsesområde § 32.10 Bestemmelsesområde #12, Bynaturpark

Bestemmelsesområdet legges til i kartet i tråd med kartet som var ute på høring, og som vist i kartutsnittet under.

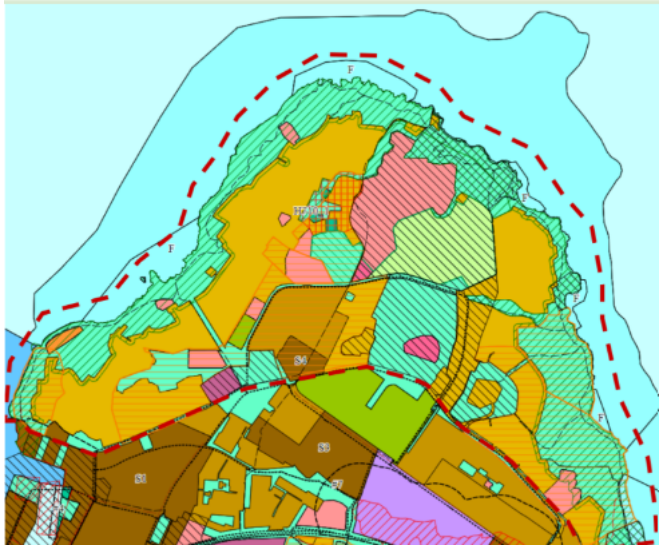

Innbyggernes bro
Innbyggernes bro tas ut av plankartet, jf. vedtak i sak 165/24 Videre arbeid med Innbyggernes bro i formannskapet 22.05.2024.

Bestemmelser
For bestemmelser som ikke er nevnt under, gjelder kommunedirektørens forslag til bestemmelser, senest datert 07.05.2024.

§ 1 Formål
Kommuneplanens arealdel skal følge opp byutviklingsstrategien, for å sikre en attraktiv og næringsvennlig kommune, tilstrekkelig tilvekst av nye boliger og gode vilkår for landbruket i kommunen. Kommuneplanens arealdel skal bygge opp under kommuneplanens samfunnsdel 2020-2032, Trondheimsløftet, og bygger på følgende hovedgrep:
- ivaretakelse av den private eiendomsretten
- holde bystrukturen samlet
- bevare områder for landbruk, natur og friluftsliv, og sikre en arealnøytral byutvikling
- differensiere tetthet og sikre variert boligbebyggelse med attraktive bolig- og bymiljø
- sikre rett virksomhet på rett sted, og nok næringsareal av ulik størrelse.
- legge til rette for et klima- og miljøvennlig transportmønster
- utvikle lokalsentre som reduserer transportbehovet
- legge føringer for klima- og miljøvennlige byggeprosjekt

§ 2.1 Forholdet til kommunedelplaner
Følgende kommunedelplaner går ved motstrid foran kommuneplanens arealdel:
- kommunedelplan for Sluppen, vedtatt 02.02.2023, med unntak av i områder i Nidelvkorridoren og områdene avsatt til næringsbebyggelse i kommunedelplanen.
- kommunedelplan for Klett, vedtatt 19.10.2023.
- Kommunedelplan for Nyhavna, vedtatt 16.06.2016, med unntak av bestemmelsesområde #1

Kaibasert næring, #2 Byøkologisk forsøksområde, #3 Mobilitetsfunksjoner og #4 Sjøbad strandveikaia, og areal til framtidig blå/grønnstruktur, idrettsanlegg og tjenesteyting. Krav til antall parkeringsplasser skal følge kommuneplanens arealdel.

§ 6.1 Byggegrense mot sjø - Trondheimsfjorden
Tiltak etter PBL § 1-6 første ledd utenom fasadeendringer kan ikke settes i verk nærmere strandlinjen, målt i horisontalplanet ved alminnelig høyvann, enn:
- Byggesone 1 og naust: 0 meter
- Byggesone 2-4 og øvrige byggeformål: 25 meter
- LNFR: 100 meter

Friluftslivstiltak kan tillates dersom viktige økologiske funksjoner blir opprettholdt. Det samme gjelder tiltak for å fremme naturmangfoldet, og tiltak som har til hensikt å reetablere historiske funksjoner.

§ 6.2 Byggegrense mot vassdrag og innsjøer
Langs Gaula og Vikelva er tiltak etter pbl § 20-1 a, d, j, k og l ikke tillatt inntil 100 meter fra normal strandlinje. Nødvendige tiltak for drift, vedlikehold og fornying av eksisterende teknisk infrastruktur, veg og bane kan tillates.

Langs alle vassdrag med årssikker vannføring, inklusive elver, bekker, vann og tjern, gjelder byggegrense på minimum 10 meter på hver side av vassdraget innenfor byggeområder og minimum 50-meter innenfor LNFR-områder. Dette gjelder både åpne og lukkede vassdrag.
Ved gjenåpning av tidligere lukkede bekker kan det tillates mindre avstandskrav ved detaljregulering.

§ 7.2 Universell utforming
Alle planforslag skal redegjøre for universell utforming i planområdet og i sammenheng med omgivelsene. Der det kan oppstå konflikt mellom ulike hensyn skal planarbeidet avveie alternative løsninger basert på prinsippet om inkludering og likeverd og hensynet til universell utforming skal veie tungt.

Uttalelser fra kommunalt råd for personer med funksjonsnedsettelser, samt berørte organisasjoner, brukes som dokumentasjon i saker som omhandler universell utforming.

§ 8.4 Overordnede strukturer
Viktige landskapstrekk, siktlinjer og landemerker, offentlige gater og byrom, blågrønne strukturer og offentlig tilgang til sjø og vassdrag skal være premissgivende for bystrukturen.

Byens viktigste landskapstrekk er høydedragene som omkranser byen, strandsonen, elve- og bekkedalene, jordbrukslandskapet, sammenhengende grøntdrag og markante trær.

Eksempel på viktige siktlinjer er mellom Gløshaugen-Studentersamfundet-Nidarosdomen.

§ 8.5 Høyhus
Trondheim skal ikke utvikles til en høyhusby.
Tempe, Rosten og Sluppen har etablerte høyhusområder.
Høyhus er her bygg over 10 etasjer, eller over 3 etasjer høyere enn omkringliggende bebyggelse.

§ 8.6 Svalganger
Svalganger og rømningstrapper skal ha høy arkitektonisk kvalitet og være godt tilpasset fasaden med en bredde som tillater gode overganger og en privat sone mellom boligens yttervegg og offentlig sone/kommunikasjonsvei.

§ 9.2 Antikvarisk verdifull bebyggelse - klasse A, B og C
Bebyggelse i klasse A og B skal i størst mulig grad etterstrebes bevart i sin helhet, og ikke vesentlig endres. Ved forfall tillates kun gjenoppføring til byggets tidligere eller opprinnelige volum og uttrykk.

Bebyggelse i klasse C skal søkes bevart. Ved tiltak som endrer bygningens uttrykk skal både antikvarisk verdi og funksjonalitet vektlegges.

Med vesentlig endring forstås svekking av bygningens utvendige antikvariske verdi. Med "eldre" menes bygningsdeler fra byggeår, og der disse ikke finnes menes bygningsdeler fra før 1940. Ved tilbakeføring av bebyggelsen skal dokumentasjon av opprinnelig/tidligere situasjon foreligge.

Antikvarisk verdi forstås som historisk, arkitektonisk eller annen kulturhistorisk verdi. Klassifisering fremgår av kulturminnekartet i Trondheim kommunes innsynsløsning.

§9.3 Hensynssoner kulturmiljø
Her skal det tas særlige hensyn ved utarbeiding av planforslag og ved søknad om tiltak etter pbl § 20-1. Tiltak skal fremme vern av kulturminnet eller kulturmiljøet. Den kulturhistoriske bebyggelsens egenart og kulturmiljøets særpreg skal sikres og opprettholdes.

Hensynssonens strøkskarakter bør være retningsgivende for byggehøyder, volum, utforming, materialbruk og farger. Estetikk, kvalitet, bevaring av store trær og andre grønne kvaliteter bør vektlegges.

Retningslinjer for de ulike hensynssonene er også angitt i vedlegg til arealdelen Kulturmiljø og antikvarisk bebyggelse og er retningsgivende ved utforming av nye planer og tiltak.

Ved nye tiltak innenfor eller nær hensynssonene kan kommunen kreve at kulturmiljøet/landskapet dokumenteres og at det redegjøres for hvordan tiltaket ivaretar og foredler områdets kulturhistoriske verdier.

§ 10.2 Kvaliteter ved boenhetene
Ensidig belyste boenheter utenfor byggesone 1, må ha stue eller privat uteoppholdsplass inntil stue med sol 21. april i minst tre timer etter kl 12.

Alle boliger skal oppfylle minst to av kvalitetene under, men i S1 holder ett.
- soverom eller stue mot stille side, ikke dempet fasade
- stue, eller privat veranda/balkong inntil stue, med sol i minst tre timer 21. april
- boenheter over 30 m2 og med minst ett soverom i tillegg til stue

Alle boenheter utenfor S1 skal være minst 30 m2.

Alle boenheter bør samtidig minst oppfylle halvparten av følgende kvalitetskriterier:
- gjennomgående boenhet eller hjørneleilighet
- størrelse over 40 m2
- utsikt fra stue/hovedoppholdsrom direkte mot landskap/større park /grøntområde
- tilgang til privat eller felles uteoppholdsareal på bakken
- beliggenhet utenfor rød støysone
- beliggenhet utenfor rød og gul støysone

§ 10.3 Fellesarealer innendørs

Ved planforslag med 20 boliger eller mer skal det sikres etablering av et samlet innendørs felles oppholdsareal.

Retningslinjer for innendørs fellesarealer:
- for 20-50 boenheter: minimum 30 m2
- for 50-100 boenheter: minimum 50 m2
- for over 100 boenheter: minimum 75 m2, pluss 0,5 m2 per boenhet over 100 boenheter

Fellesarealet bør ligge i første etasje og ha direkte kontakt med gaterommet og hovedadkomst til boligene.

§ 12.1 Overvannshåndtering
Planforslag og søknad om tiltak skal identifisere, dimensjonere og sikre arealer for overvannshåndtering og flomveger i tre trinn i tråd med Trondheim kommunes VA-norm og sanitærreglement.

Overvann skal søkes utnyttet som positivt element i bymiljøet og styrke lokalt naturmangfold. Andre løsninger må begrunnes. Utfyllende beskrivelse av overvannshåndtering i tre trinn er gitt i Trondheim kommunes VA-norm.

I "Middelalderbyen" skal overvannshåndtering planlegges i samråd med arkeologisk fagmiljø/Riksantikvaren

§ 13.1 Generelt
Transportsystemet skal bidra til en attraktiv by, at flere går, sykler og reiser kollektivt og at viktige samfunnsfunksjoner har nødvendig fremkommelighet. Bystrukturen skal planlegges slik at byens gater og byrom gir et attraktivt og finmasket gangnett som gir kort adkomst til viktige målpunkt.

Ved planlegging av nye samferdselsanlegg skal etablering av allé eller trær vurderes.

F*or eksisterende alleer og trerekker bør trær og tilstrekkelig rotsone bevares. Allétrær som fjernes bør erstattes.*

Fortau bør opparbeides med minst 2,5 meter asfaltert bredde og reguleres med 3 meter bredde for å inkludere skulderareal. I private blindveger uten gjennomgang kan 1,5 meter asfaltert bredde aksepteres hvis de betjener færre enn 50 boenheter.

§ 13.2 Innenfor tettstedene
Samferdselsanlegg innenfor byggesone 1-3 og ellers innenfor tettstedene skal utformes som gater for lav fart og med areal til blågrønne kvaliteter. Unntak er fjernveger og skinnegående transport.

Tilrettelegging for kryssing for fotgjengere skal være på bakkeplan, unntatt over fjernveg. Annen løsning kan vurderes der alternativet i større grad oppfyller målet om at flere går, sykler og reiser kollektivt. Planskilte kryss kan vurderes som et tillegg der dette er nødvendig for å sikre trygg skoleveg.

§ 13.4 Mobilitetsutredning
I planforslag skal det redegjøres for hvordan planforslaget vil bidra til at flere går, sykler og reiser kollektivt. Nødvendige tiltak i mobilitetsutredningen skal sikres i reguleringsplanen.

Mobilitetsutredningen bør vise:
1. Forventet transportbehov: reiser til/fra bolig/virksomhet, besøksreiser, varelevering, godstransport.
2. Tilbud for gående, syklende, kollektivtrafikk og kjørende.
3. Trafikksikkerhet og fremkommelighet for gående, syklende, kollektivtrafikk og utrykningskjøretøy
4. Tiltak for å bedre tilgjengeligheten for gående, syklende og kollektivreisende og hvordan tiltakene bidrar til å nå målet om 20 prosents reduksjon i personbiltransport.
5. Parkeringstilbud for bil og sykkel, herunder plassering, utforming og ladeinfrastruktur. Det bør illustreres hvordan antall plasser er tenkt fordelt på personer med nedsatt funksjonsevne, beboere, besøkende, kunder, tjenesteytere og delebiler. Det bør også fremkomme om parkering kan samlokaliseres med andre boligfelt eller virksomheter i området.
6. Behov for regulering av offentlige gater i det aktuelle influensområdet for å begrense parkering utenfor eiendom.
7. Løsninger for renovasjon og varelevering.
8. For planlagt ny næringsbebyggelse skal det også foreligge en vurdering av om lokaliseringen er i samsvar med målsettingen om rett virksomhet på rett sted (§ 18).

§ 13.9 Turveg
Turveger vist i byggeområder kan reguleres til og utformes som gangveg. Alle reguleringsplaner skal redegjøre for nærhet til turveger.

§ 14.1 Antall parkeringsplasser for boligbebyggelse
Det skal avsettes plass for biler og sykler i samsvar med norm som angitt i vedlagte tabell.

Avrundingsregel: minimumskrav rundes opp og maksiumumskrav rundes ned til nærmeste hele tall.

§ 14.4 Bilparkeringsplasser for besøkende og nyttekjøretøy
I tillegg til parkeringsplasser etablert etter § 14.1 og § 14.2, skal det etableres bilparkeringsplasser for besøkende og nyttekjøretøy.

Antall parkeringsplasser skal vurderes og fastsettes i den enkelte reguleringsplan. Det skal alltid sikres minst 1 parkeringsplass.

Kravet gjelder ikke for frittliggende eneboliger og tomannsboliger, eller for kontor i felt S1. Kravet kan frafalles dersom det er tilstrekkelig tilgang på offentlige plasser i nærheten.

§ 14.5.1 Plassering
Plassering av parkeringsplasser skal vurderes og fastsettes i den enkelte reguleringsplan eller byggesak. Felles parkeringsanlegg skal som hovedregel anlegges ved kjøreadkomst fra veg.

Ved anleggelse av flere enn åtte parkeringsplasser, bør det vurderes å samle disse i felles parkeringsanlegg.

§ 14.6 Plassering og utforming av sykkelparkering

Sykkelparkering skal plasseres nær hovedinnganger. Det skal legges stor vekt på brukbarhet, tilgjengelighet og trygghet ved utforming.

Der normen gir krav om minst 10 sykkelparkeringsplasser bør:
- minst 50 prosent være innvendig i bygg eller ha overbygg, men etableres i tillegg til annet

bodareal
- minst 15 prosent være for sykkelvogner og lastesykler, og være minst 1 m x 2,6 m - det for virksomheter være garderobe med dusjfasiliteter for ansatte

Der normen gir krav om minst 100 sykkelparkeringsplasser bør det avsettes areal til vask og enkel service.

Parkering for sykkel i kjeller bør legges i første parkeringsplan, og det bør sikres adkomst via rampe eller bilheis/spesialheis dimensjonert for sykkelvogner og lastesykler. Andel sykkelparkeringsplasser i to-etasjes stativ bør begrenses.

Parkeringsareal for normale sykler bør være minst 0,75 m2 pr. plass, med låsefunksjon mot sykkelramme.

§ 15.4 Fjernvarme
Ved utbygging eller ved hovedombygging med samlet areal over 1000 m2 BRA innenfor gjeldende konsesjonsområde for fjernvarme skal bebyggelsen tilknyttes fjernvarmeanlegg. Tilknytningsplikten gjelder også for mindre bruksareal innenfor konsesjonsområdet dersom arealet er en del av et framtidig større utbyggingsprosjekt.

Det kan kun fritas for tilknytningsplikt til fjernvarme hvis det dokumenteres at klimagassutslippene ved andre energiløsninger er lavere og belastningen på el-nettet blir akseptabel. Nødvendig anleggsarbeid for å etablere løsningene skal inkluderes i klimagassberegningen.

Akseptabel belastning på el-nettet tilsier at varmeløsningen ved dimensjonerende utetemperatur ikke belaster el-nettet vesentlig mer enn tilsvarende bygg som tilfredsstiller gjeldende byggteknisk forskrift og som benytter fjernvarme som primærvarmekilde.

§ 17.3 Næringsavfall
I byggesone 1 og 2 skal næringsavfall løses innomhus.

I øvrige byggeområder skal næringsavfall løses på egen grunn og fortrinnsvis innomhus. Utomhus bør det tilstrebes nedgravde oppsamlingsløsninger.

I byggesone 1 og 2 bør det vurderes om næringsarealer kan ha felles renovasjonsløsning med husholdninger i samme bygg eller på nærliggende tomt.

§ 17.4 Offentlig returpunkt og ombrukssentral
Ved planlegging og oppføring av nye bygg på over 1000 m2 BRA i byggesone 1, 2 eller 3 må det avklares om det skal sikres areal til offentlige returpunkt for renovasjon.

Ved utarbeiding av områdeplaner i byggesone 1 og 2 skal areal til ombrukssentral vurderes.

§ 18.1 Lokalisering av virksomheter
Virksomheter skal lokaliseres etter prinsippet rett virksomhet på rett sted. Støyende virksomheter og virksomheter med sikkerhetssoner skal etableres med god avstand fra boliger eller andre følsomme formål.

Prinsippet rett virksomhet på rett sted er illustrert i temakart, og innebærer:
- Arbeidsplassintensive virksomheter, som kontor, skal lokaliseres langs kollektivbuen mellom

Sluppen og Strindheim, i tilknytning til kollektivknutepunktene Heimdal, Tiller og Strindheim, eller i større lokale sentrumskjerner (felt S3), eller i andre områder der kollektivdekningen er/kan bli tilfredsstillende i løpet av planperioden. I disse områdene skal arbeidsplassintensive virksomheter kun etableres innenfor byggesone 1, byggesone 2 eller fra andre etasje og opp innenfor formålet næringsbebyggelse. Arbeidsplassintensive virksomheter kan også lokaliseres innenfor formålet næringsbebyggelse på Tunga fra andre etasje og opp.
- Publikumsrettede virksomheter, som handel, tjenesteyting og andre kultur- og servicetilbud som har kommunen eller regionen som omland, skal lokaliseres i byggesone 1 - S1, på Midtbyhalvøya. Små publikumsrettede virksomheter med lokalt nedslagsfelt skal kun tillates i byggesone 1, og på inntil 400 m2 BRA i byggesone 2.
- Hotell skal kun tillates innenfor Midtbyen og sentrumsområdene rundt (felt S1) og i de største knutepunktene (felt S2).
- Forretninger generelt skal lokaliseres i byggesone 1. Dagligvareforretninger på inntil 2 000 m2 BRA kan vurderes tillatt i byggesone 2 og 3 gjennom detaljreguleringsplan. Forretninger for plasskrevende varer kan vurderes tillatt gjennom reguleringsplan innenfor arealer avsatt til næringsbebyggelse merket NF på Tiller. BRA for handel defineres som summen av salgsflate, lagerlokale, spiserom/kantine og kontorareal som er nødvendig for driften. Areal til parkering og varelevering inngår ikke.
- Næringsvirksomheter med få besøkende, som bygg- og anleggsvirksomheter, håndverkere, teknologi og produksjonsvirksomheter, skal lokaliseres innenfor formålet næringsbebyggelse, eller innenfor byggesone 1-3. Virksomheter som ikke kan tilpasses bystrukturen eller fører til vesentlig støy- og trafikkbelastning for omgivelsene bør ikke lokaliseres i byggesone 1-3.
- Arealkrevende næringsvirksomheter med behov for nærhet til hovedvegnettet skal fortrinnsvis lokaliseres innenfor formålet næringsbebyggelse i felt merket NA.

Ved arbeidsintensiv virksomhet/kontorformål bør det settes av areal til uteoppholdsareal for ansatte.

§ 19.2 Støyutredning
Støy fra veg, bane, havnevirksomhet, helikopter og industri skal utredes ved etablering av støyfølsomme formål. For veg, bane og helikopter skal støykart i kommunens kartløsning legges til grunn for vurdering av behovet for støyutredning.

§ 19.5 Stille områder og grønnstruktur
I og i nærheten av stille områder vist i Temakart støysone veg og stille områder og formålet blå/grønnstruktur, skal det dokumenteres ved planlegging og søknad at tiltak ikke medfører en økning av støynivået i disse områdene.

Lydpåvirkning (Lden) fra vegtrafikk, bane, trikk, helikopter, havne- og industrivirksomhet bør holdes under 55 dBA for grønnstruktur generelt og under 50 dBA for stille områder. Ved flere støykilder bør sumstøy vurderes. For andre støykilder brukes grenseverdier i T-1442. Støynivå fra tekniske installasjoner bør tilfredsstille samme krav som stilles til lydnivå ved boligfasade.

§ 22 Plan for bygge- og anleggsfasen
Plan for beskyttelse av omgivelsene i bygge- og anleggsfasen skal foreligge før arbeidet kan igangsettes.Nødvendige beskyttelsestiltak skal være etablert før bygge- og anleggsarbeider kan igangsettes. I bygge- og anleggsfasen skal det være god framkommelighet, trafikksikkerhet og orienterbarhet for gående, syklende og kollektivtransport.

Planen bør redegjøre for trafikkavvikling, massetransport, driftstider, støyforhold, rystelser og vibrasjoner, ivaretakelse av terreng og verdifull vegetasjon, renhold og støvdemping,

framkommelighet og trafikksikkerhet for gående, syklende og kollektivtransport, håndtering av avrenning for å ivareta hensyn til vannmiljø og avløpsnett samt tiltak for å redusere klimagassutslipp. Lange omveier for gående og syklende bør unngås.

Tiltakshaver er ansvarlig for at planen foreligger, at planen er tilgjengelig på bygge-/anleggsplassen og at den er kjent for foretakene som utfører arbeid. Det bør vises hvordan kravene i §§ 15.4, 19.6 og 20.2 tilfredsstilles og dokumenteres i bygge-og anleggsfasen. Ved større prosjekter bør planen revideres. Ved flere utbygginger i samme område bør tiltakene samordnes.

§ 23.1 Felles formålsbestemmelser byggesone 1-4:
Byggesone 1 og 2 utgjør tilsammen de mest sentrale byområdene i kommunen, hvor det skal legges til rette for at hovedandelen av nye boliger lokaliseres.

Arbeidsplassintensive virksomheter skal lokaliseres i byggesone 1 og 2 langs kollektivbuen og ved de store knutepunktene.

Byggesone 1 skal utvikles med et mangfold av publikumsfunksjoner tilpasset stedets omland, og et aktivt og levende bymiljø.

Byggesone 2 og 3 skal videreutvikles som områder for boliger med innslag av næring, og nødvendig areal til tjenesteyting og idrett. Virksomheter med mange besøkende, eller som ikke kan tilpasses bystrukturen eller gir vesentlig belastning på tilliggende vegnett, bymiljø og bomiljøer tillates normalt ikke.

Byggesone 4 skal utvikles i tråd med omgivelsene, og antall nye boliger skal begrenses.

Ved regulering kan justeringer av grensene mellom byggesonene vurderes etter en stedsanalyse. Dette for å sikre bedre utnyttelse av arealer innenfor byggesonene og bedre tilpasning til etablert gate- og bebyggelsesstruktur, samt hensynta naturlige terrengavgrensninger, viktige natur- og kulturhistoriske verdier eller fjernvirkning i landskapet.

For alle planforslag skal det tidlig i planprosessen avklares behov for å innpasse areal til nye, eller utvidelse av eksisterende, offentlige funksjoner eller annen nødvendig infrastruktur.

Dagligvarehandel skal lokaliseres i tilknytning til bydelens gang- og sykkelnett og nært godt kollektivtilbud.

Alle byggesonene skal utvikles på en måte som bidrar til å skape en inkluderende by, der bymiljø og møteplasser er tilgjengelige og åpne for alle.

§ 23.2 Felles bestemmelser byggesone 1 og 2
Områdene skal utvikles etter bymessige prinsipper, med høy tetthet og kvalitet, og sammenhengende byromsnettverk.

Ny bebyggelse skal utformes og plasseres slik at den ikke er til hinder for at omkringliggende eiendommer kan utvikles med tilsvarende tetthet og kvalitet, der hvor dette kan være aktuelt.

Langs fasader som henvender seg mot hovedgater og offentlige byrom skal det vurderes etablert utendørs møbleringssone som muliggjør tilrettelegging for utendørs byliv.

Første etasje, herunder areal på bakkeplan trukket inn under tak, ut mot sentrale offentlige gater, gangveger og byrom bør ikke inneholde parkeringsanlegg, boder og lager, samt større rom for

tekniske anlegg.

Stopp for tjeneste- og varelevering og renovasjonsbiler skal fortrinnsvis etableres i forbindelse med møbleringssone langs sidegater.

Det skal tilstrebes et finmasket gangnett. Ved planlegging av ny bebyggelsesstruktur bør kvartaler ha maksimal bredde/lengde på 70 meter, og fasadene underdeles med sprang i fasadeliv og variert material- og fargebruk minst hver 30 meter. Føresteetasjer ut mot sentrale offentlige gater, gangveger og byrom bør ligge på samme nivå som gateplan for å muliggjøre innganger fra gata. Felles oppholdsrom for flere boenheter, kantiner eller lignende skal fortrinnsvis plasseres her. Som en mindre del av møbleringsarealet langs gater kan det etableres langsgående offentlig korttidsparkering for besøkende, HC
parkering og taxi.

§ 23.3.3 Utforming av bystruktur og bebyggelse:
Sentrumsstrategien og Gatebruksplan for Midtbyen skal legges til grunn som stedsanalyse for planforslag i byggesone 1, felt S1 Midtbyen og Trondheim sentrum.

For planforslag i sentrumskjerner felt S2-5 skal det utarbeides stedsanalyse.

Mot torg og sentrale gaterom/strøk skal fasader i første etasje ha et åpent uttrykk og en stor andel vinduer, samt dører med direkte adkomst fra gateplan.

Arealene i etasje på gateplan bør være fleksible for ulike typer virksomheter og enhetsinndeling. Takhøyde bør være minimum 4,5 meter brutto. Vinduer bør ikke dekkes med folie eller lignende.

§ 23.4.2 Arealbruk
a. Innenfor byggesone 2 tillates kun følgende formål: boligbebyggelse, offentlig tjenesteyting, privat tjenesteyting inntil 400 m2 BRA, idrettsanlegg, næringsbebyggelse.
b. Forretning tilknyttet næringsvirksomheter tillates på inntil 25 % av virksomhetens BRA.
c. I eksisterende bebyggelse av antikvarisk verdi klasse A-C tillates også tjenesteyting som kan bidra til at bebyggelsen fortsatt kan være i bruk.

Forretningsformål bør være knyttet til service- og håndverksvirksomheter.

§ 23.5.2 Arealbruk
a. Innenfor byggesone 3 tillates kun følgende formål: boligbebyggelse, offentlig tjenesteyting, idrettsanlegg, og næringsbebyggelse.
b. Forretning tilknyttet næringsvirksomheter tillates på inntil 25 % av virksomhetens BRA.
c. I eksisterende bebyggelse av antikvarisk verdi klasse A-C tillates også tjenesteyting som kan bidra til at bebyggelsen fortsatt kan være i bruk.

Forretningsformål bør være knyttet til service- og håndverksvirksomheter.

§ 24.1.1 Generelle bestemmelser
Det må foreligge godkjent avløpsløsning med felles ledningsnett knyttet til kommunalt nett eller eget renseanlegg før igangsettingstillatelse kan gis.

Fritidsbebyggelse skal tilpasses tomtearealet, og bør ha maksimalt 120 m2 BRA for hovedbygg.

§ 24.4.1 Innhold

Innenfor formålet kan det etableres næringsvirksomheter i tråd med prinsippet for rett virksomhet på rett sted. Energianlegg tillates. Ved søknad om tiltak gjelder formål angitt i vedtatt reguleringsplan foran formål angitt i arealdelen dersom motstrid.

Innenfor arealer avsatt til næringsbebyggelse bør det kun tillates håndverk og industri (1340), lager (1350) og bensin-/energistasjon (1360), samt energianlegg. Dette med unntak av på Strindheim mellom jernbanen og Innherredsveien, hvor det fra andre etasje og opp kan etableres kontor (1310).

Innenfor felt merket NA bør næringsarealene forbeholdes større produksjons- og lager/logistikkvirksomheter med behov for stort, sammenhengende areal.

På Tiller i felter merket NF kan det vurderes tillatt forretning for plasskrevende varegrupper gjennom reguleringsplan.

For Tunga næringsområde tillates det kontor for virksomheter med få besøkende fra andre etasje og opp. Etasjer på bakkeplan skal forbeholdes næringsformål som angitt over.

Det vises for øvrig til retningslinjene under § 18 Rett virksomhet på rett sted.

§ 24.5 Idrettsanlegg (1400)
Ved detaljregulering skal det i tillegg til idrettsanlegg legges til rette for grønne forbindelser og egenorganisert aktivitet.

§ 24.6.2 Massedeponi
Ved detaljregulering og søknad om etablering av massedeponi skal det foreligge en plan for drifts- og anleggsfasen. Planen skal sikre naturverdier og trinnvis utvikling av deponiet, slik at naturverdier ivaretas fram til området tas i bruk.

Etterbruk til LNFR skal sikres i reguleringsplan. Jordbruksarealer skal istandsettes for jordbruksdrift. Felt merket MN kan ha næringsbebyggelse som etterbruk. Dette må sikres i reguleringsplan.

Ved etablering av nye massedeponi eller ved vesentlige utvidelser, skal det vurderes sorteringsanlegg og muligheter for gjenbruk av rene masser.

Planen bør også redegjøre for miljøbelastninger knyttet til drift og transport til og fra deponiet for influensområdet, geotekniske forhold, landbruksfaglige forhold, landskap/stedskvalitet, og naturmangfold og vannmiljø.

§ 24.7.5 Fossegrenda KB5 (ny bestemmelse)
Innenfor område KB5 tillates bolig og næring med minimum utnyttelse 100% BRA.

§ 25.2 Offentlige parker
Arealene skal gi tilbud til alle og være offentlig tilgjengelige. Overvannshåndtering skal være godt ivaretatt. Materialbruk og utførelse skal ha høy kvalitet og sikre lang levetid ved høy bruksintensitet.

All vegetasjon bør sikres gode vekstforhold. Der offentlig park etableres på tak eller konstruksjoner under bakken bør konstruksjonen dimensjoneres til å tåle etablering av trær, vegetasjon og jordoverdekning, samt vedlikeholdskjøretøy.

§ 28.3.2 Grunneiere og andre rettighetshavere
For grunneiere og andre rettighetshavere i tilsigsområdet gjelder følgende bestemmelser:
Hele hensynssonen:
a. Det er forbudt å lagre avfall eller avløpsslam.
b. Fritidsboliger skal ikke ha innlagt vann. Fritidsboliger skal ha avløpsfritt forbrenningstoalett eller annen løsning
c. Kunstgjødsel må primært lagres under tak eller sekundært være forsvarlig tildekket. Det er forbudt med inntransport av husdyrgjødsel eller avløpsslam til nedbørfeltet.
d. Transport og lagring av farlige produkter, som oljeprodukter, drivstoff og kjemikalier, skal foregå slik at det ikke kan utgjøre noen fare for forurensning i sonen. Kravet omfatter også håndtering av maskiner eller andre kjøretøy ved vask, reparasjon, oljeskift og lignende aktiviteter som kan medføre fare for forurensning i sonen. Dersom det skjer utslipp i nedbørfeltet, plikter den som oppdager utslippet å varsle vannverkseier og forurensningsmyndigheten.
e. Det er forbudt å salte veier.

§ 28.4 Bestemmelsen strykes

§ 28.5 Bestemmelsen strykes.

§ 28.6 Bestemmelsen strykes.

§ 30.2 Bestemmelsen strykes.

§ 30.3 Bestemmelsen strykes.

§ 32.3 Bestemmelsesområde #3, Mobilitetsfunksjoner
Innenfor bestemmelsesområdet skal mobilitetsfunksjoner samles ett eller flere steder med bydelsparkering, i tråd med mål om et bilfritt område på Nyhavna. Dette sikres ved detaljregulering innenfor felt 1 - 10 i KDP Nyhavna. Det kan benyttes midlertidige parkeringsløsninger for å dekke parkeringskravet for boligene inntil 250 av boligene totalt innenfor feltene er tatt i bruk.

§ 32.4 Bestemmelsesområde #4, Sjøbad Strandveikaia
Innenfor området skal det etableres offentlig sjøbad i tråd med Kvalitetsprogram for Nyhavna.

§ 32.6 Bestemmelsesområde #6, Offentlig tjenesteyting
Før planlegging eller gjennomføring av tiltak innenfor området skal behov for offentlig tjenesteyting avklares.

På Hallset skal bestemmelsen ivareta et nytt helse- og velferdssenter, på Tempe og Overvik en ny barnehage, og på Strindheim en utvidelse av skoletomt.

§ 32.10 Bestemmelsesområde #12, Bynaturpark (ny bestemmelse)
Innenfor området skal det tas særskilt hensyn til naturverdier, kulturmiljø og landskap. Særskilte krav til blågrønn faktor for området, angitt i kommunens Norm for blågrønn faktor, skal oppfylles. Ved planlegging av nye samferdselsanlegg skal etablering av allé eller trær vurderes. For eksisterende alleer og trerekker skal trær og tilstrekkelig rotsone bevares. Allétrær som fjernes skal erstattes

Byggesone	Sykkel	Bil – per 100 m2 BRA

Byggesone 1 – felt S1	Største tall av 3 parkeringsplass pr. 100 m2 og 1,5 parkeringsplass per boenhet	Midtbyen: 0 / S1: maks. 0,4
Byggesone 1 – felt S1		min 0,1 - maks 0,7
Byggesone 2		min 0,2 – maks 0,9
Byggesone 3		min 0,4 – maks 1,1
Øvrige soner		min 0,6 – maks 1,5
Frittliggende eneboliger ogtomannsboliger i byggesone3 og øvrige soner	4 pr. boenhet	min. 2 pr boenhet

Generelt

Næringsareal

Bystyret ber byrådet fram til rullering av neste KPA kartlegge og finne nye næringsarealer slik at målet om 3000 dekar næringsareal fastholdes. Bystyret mener nytt næringsareal er nødvendig for å sikre transformasjon av enkelte områder f.eks. Nyhavna, Lade, Tempe og Sluppen. Det er også viktig å sikre tilstrekkelig areal for å tilrettelegge for ny næringsvirksomhet. Trondheim som teknologihovedstad har et mål om å skape betydelig høyt antall arbeidsplasser knyttet til teknologi, som vil kreve arealer for ny produksjon og utviklingsarbeid. I tillegg vokser byen med et stort antall nye innbyggere årlig som igjen fører til økt behov knyttet til lager og logistikk.

Offentlig tjenesteyting

Bystyret ber byrådet om å følge opp følgende i arbeidet med revidering av plan for areal til offentlige tjenester (PAOT) og i forbindelse med neste rullering av kommuneplanens arealdel (KPA):

- Finne flere områder til helse- og velferdssenter, skoler, barnehager og idrettsformål for å dekke behovet. Det skal vurderes om dette kan løses innenfor andre arealformål, særlig hvordan helse- og velferdssenter og barnehager kan inkluderes i sentrumsformål og boligprosjekter.

Utredning økologisk kompensasjon

Bystyret ber byrådet utrede hvordan økologisk kompensasjon kan brukes for å ivareta prinsippet om arealnøytralitet i kommuneplanens arealdel. Målet med utredninga er en kommunal veileder for økologisk kompensasjon.

Fortetting av eksisterende næringsareal

Bystyret ber byrådet om å ha dialog med aktører som kan bidra til økt utnyttelse og fortetting av eksisterende næringsareal slik at sentrale områder kan transformeres raskere.

Drikkevannsbestemmelser Jonsvatnet

Hensynssonene blir som foreslått i innstillingen til ny KPA, men gjeldende bestemmelser i KPA videreføres. Bystyret ber byrådet om å legge fram nytt forslag til bestemmelser knyttet til hensynssonen rundt Jonsvatnet innen sommeren 2025

Innbyggernes bro

Innbyggernes bro tas ut av plankartet, jf. vedtak i sak 165/24 Videre arbeid med Innbyggernes bro i formannskapet 22.05.2024.

Behov for nye høringer
Bystyret ber byrådet sende følgende forslag på høring. Bystyret ber byrådet komme tilbake med et forslag og en sak til bystyret etter høringsrunden er avsluttet.
1. § 6.6 Byggegrense mot formålet blå/grønnstruktur endres til retningslinje
2. § 10.4 endres til retningslinjer
3. § 13.3 Snøopplag endres til: Langs offentlig veg skal det sikres tilstrekkelig areal til snøopplag. Areal til snøopplag sikres gjennom den enkelte reguleringsplan, på grunnlag av forventede snømengder.
4. Nye minimums- og maksimumsgrenser for bilparkering i §14.1:
§ 14.1 Midtbyen: min 0 / S1: maks 0.6
Byggesone 1 - felt S2-S5 min. 0 - maks 0.8
Byggesone 2 min. 0 - maks 1
Byggesone 3 min. 0 - maks 1.2
Øvrige soner min. 0 - maks 1.5
Frittliggende eneboliger og tomannsboliger i byggesone 3 og øvrige soner: min. 1 pr boenhet
5. Nye maksimumsgrenser for bilparkering pr 100 m2 BRA i §14.2:
Forretning, maks 4
Kontor, byggesone 1 og 2: maks 0.5
Kontor, byggesone 3: maks 1
Kontor, øvrige soner: maks 2
Privat tjenesteyting, maks 0.5.
6. Bestemmelse 14.5.2 endres til:
Utforming av nye parkeringsanlegg skal være i henhold til Statens vegvesen Håndbok N100.
Ved vedlikehold av eksisterende anlegg kan 2,3 meters bredde aksepteres.
7. Punkt b og c i § 23.3.2 strykes
8. 23.3.4 Bymiljø endres til retningslinje
9. Nytt forslag til § 23.5.1 Utnyttelsesgrad
Grad av utnytting tilpasses områdets strøkskarakter, samtidig som hensiktsmessig utnyttelse av arealet sikres.

Ivaretakelse av eksisterende bomiljø, naturverdier og kulturhistoriske verdier bør tillegges vekt ved nye bygninger og andre tiltak.

Ved planlegging av større nye byggeområder eller transformasjonsområder bør det legges vekt på effektiv arealbruk innenfor de rammene som for øvrig er gitt i bestemmelsene. Andel areal på bakkeplan avsatt til kjøring og parkering bør begrenses.
10. §24.4.2 Utnyttelse og utforming (næringsareal) endres ved at første setning beholdes som bestemmelse, øvrig endres til retningslinje.
11. Ny tekst til bestemmelse § 26.3 Fritidsbebyggelse
Oppføring av ny eller utvidelse av bestående fritidsbebyggelse kan godkjennes så lenge tiltaket ikke medfører flere boenheter eller legger til rette for økt bruk. Bruksendring fra fritidsbebyggelse til bolig er ikke tillatt.
12. Markagrensa i Klæbu: Nytt forslag til rød strek (Markagrensa) i tidligere Klæbu kommune flyttes slik at eksisterende helårsboliger ikke ligger innenfor rød strek etter endringen.
13. Teksten " turistbåter med godkjenning " legges til bestemmelsens §27.4 ift hvilke aktiviteter som er unntatt fra forbudet
14. Tilgrensede tomter til område 937 Østmarka gnr/bnr 413/168 og 169 høres som blå/grønnstruktur.
15. Område 127 Moksneslia sendes på høring med formål byggesone 2.
16. Område 402 Ladalen sør for Haakon VIIs gate som var foreslått som næring høres som

byggesone 1, med bestemmelser som sikrer areal til blå/grønnstruktur som er minst like stort som det som ble hørt november 2022.
17. Området på Byåsen mellom Bygrensa, Åsveien skole og Breidablikk som vist i kartutsnitt under med byggesone 2 sendes på høring med formål byggesone 3.

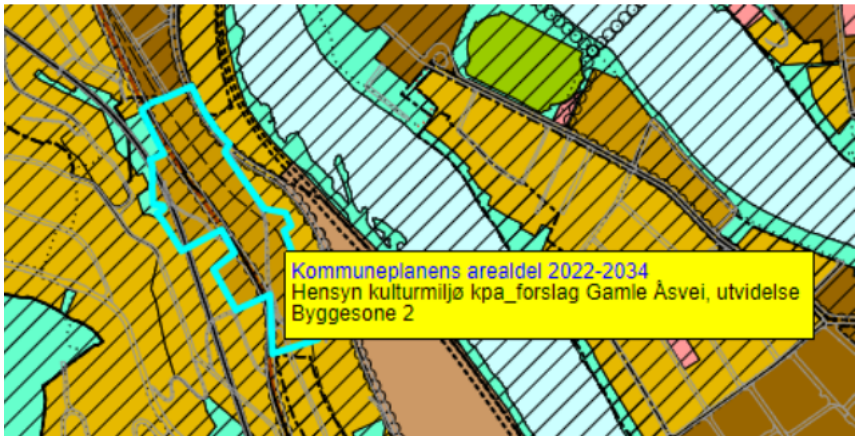

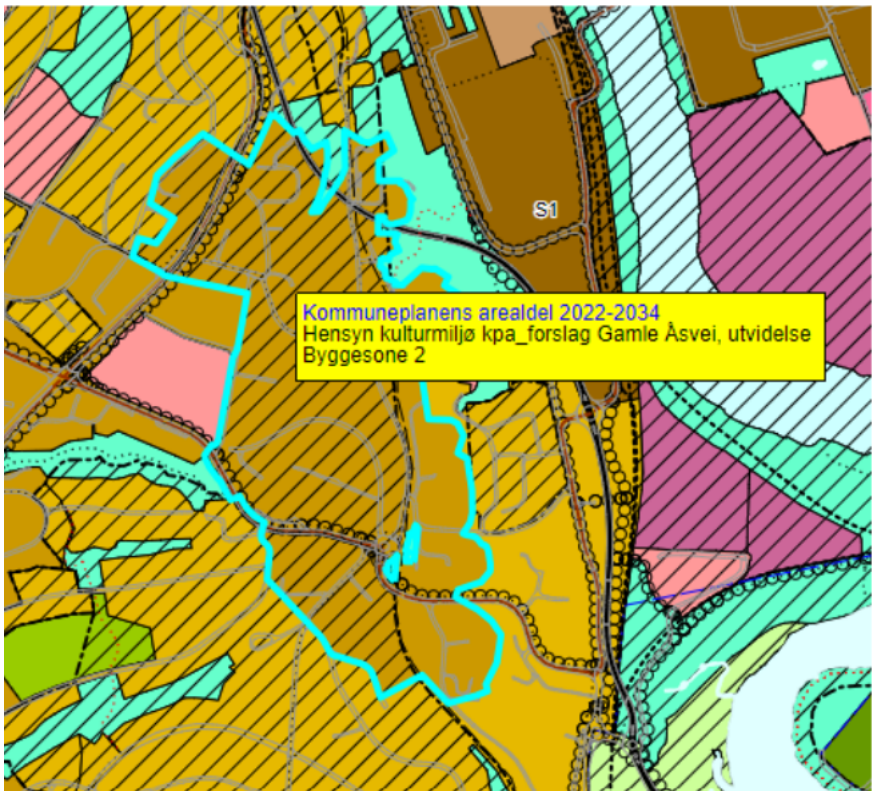

Emil Raaen (Ap) fremmet følgende alternative forslag "Helhetlig forslag, endringer i arealdisponering og byggesoner":

1. Bystyret vedtar forslag til ny kommuneplanens arealdel 2022-2034 som vist på kart i målestokk 1:40 000, senest datert 07.05.2024, og med bestemmelser senest datert 07.05.2024 og beskrevet i planbeskrivelsen, senest datert 07.05.2024, og med de endringer som følger av bystyrets vedtak.

2. Kommuneplanen gjelder fra det tidspunkt planen er vedtatt av bystyret, og vil da gjelde for alle søknader om tiltak og forslag om regulering, jf. § 11-6. Unntak gis for planforslag som mottas som komplett innen seks måneder etter vedtaket av arealdelen. Planforslaget skal være komplett etter loven og krav gitt i Trondheim kommunes veileder for reguleringsplaner. Unntak forutsetter videre at føringer gitt i kommuneplanens arealdel for Trondheim 2012-2024 eller for Klæbu 2010-

2021 følges. En eventuell kombinasjon med føringer fra ny arealdel forutsetter at dette bidrar til bedre bolig- og bykvalitet.

Vedtaket fattes i henhold til plan- og bygningsloven § 11-15

3.Bystyret vedtar at det gjennomføres ny høring for de områder som etter dette vedtaket er nødvendig, før de tas opp til endelig sluttbehandling.

<u>3. Bystyret vedtar følgende endringer i arealdisponering</u>
1. Fossegrenda (9/933) - Framtidig kombinert bebyggelse og anlegg KB5 Innenfor område KB5 tillates bolig og næring med minimumsutnyttelse 100% BRA.
2. Eklestrøa (142) - byggesone 3 og framtidig næringsbebyggelse og LNFR
3. Espflaten (130) - Byggesone 3
4. Flatåsen (106/58) - Fremtidig næring, sentrumsformål og byggesone 2 Hele område 58 reguleres til sentrumsformål og byggesone 2. Område 106 som ikke overlapper 58 reguleres til næringsformål.
5. Fuglmyra (110 /569) - 50 daa næringsareal. Området mellom Postmyra og Gaddmyra. reguleres til næringsareal (50 daa) Fuglmyra skal bevares.

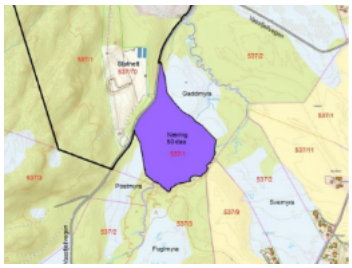

6. Hallsteingård (337) - -Byggesone 3
7. Heimstad (787 (78)) Byggesone 3
8. Hermo (120) Byggesone 3
9. Granås gård (77) Byggesone 3
10. Klet (54) Byggesone 3
11. Brøset (932) Byggesone 2 og offentlig tjenesteyting
12. Kastbrekka/Tomset (108) Byggesone 3
13. Kattem. Aktivitetshus med driftsgarasje (340) Framtidig næringsbebyggelse
14. Område 602/945 Tanemsflata/Tanemsmyra Byggesone 2
15. Kleiva (901/67) Byggesone 3
Området Kleiva på Tanem legges inn i ny KPA med definisjon boligutbygging. Området begrenses til å gjelde inntil 100 boliger.
16. Klokkesvingen Lerkendal (926) Byggesone 1
Arealet reguleres til byggesone 1, bystyre viser til bygningsrådets vedtak den 16.05.2023. der følgende vedtak ble gjort: Bygningsrådet vedtar å legge forslag til detaljregulering av Lerkendal øst, gnr/bnr 62/537 m.fl., ut til offentlig ettersyn, samtidig som det sendes på høring. Hensikten med reguleringsplanen er å etablere kontorarbeidsplasser.
17. Kruskajordet (218) Framtidig idrettsanlegg
18. Leinan (919) Framtidig massedeponi
19. Moksneslia (127) Byggesone 3
20. Oustmyrvegen (143) Byggesone 3
21. Overvik gårdstun (910) Byggesone 3
22. Gamle ladejarlen (124/940 Byggesone 2
23. Øvre Rotvoll sør (911a) Framtidig næringsbebyggelse

24. Ranheimsvegen 305 (941) Byggesone 4
25. 811 Fortunalia (811) Byggesone 3.
26. Valkyrieveien (27) Byggesone 2
27. Fossbakken 9 (10) Byggesone 3
28. Heimdalsveien (93) Næringsareal
29. Osloveien 276A (57) Byggesone 3
30. Brøsetekra 5,7 og 13 (945) Byggesone 2
31. Område 50 Bratsbergvegen 139 avsettes til byggesone 3 og næring

32. Rye/ Bjøra (tidl. 135) (947/802) Byggesone 4
Arealet som i gjeldende KPA (13 daa) er regulert til boligformål, settes av til boligformål og byggesone 4.
33. Saghaugen (928) Fritidsbebyggelse
34. Tempe (918) Kombinert næring noe bolig
Innenfor området ved Tempevegen som er hørt som næringsareal tillates bolig og næring med minimum utnyttelse 100% BRA.
35. Tiller KB5 med forretning (954 a næringsbebyggelse, sentrumsformål og forretning i tråd med gjeldende KPA
36. Overvik
Bystyret vedtar at realisering av midlertidige og permanente anlegg innenfor vedtatt områderegulering på Overvik (område KBA) gjenopptas og gjennomføres. Dette vil i henhold til behovsanalysen være eneste mulighet for å dekke anleggsbehovet i bydelen på kort og lang sikt. Områdeplanen for Overvik skal derfor gjennomføres i sin helhet slik bystyret vedtok den uten innsigelser 25.04.2019.
37. Håkon VII gate (402) byggesone 2 og framtidig blå/grønnstruktur

38. Område 48 Stokkåsen
Område 48 Stokkåsen får byggesone 3 som formål, markagrensa justeres
39. Område 41 Røddevegen
40. AP 1 Hensynssone: Wullumsgården.
Hensynssone: Wullumsgården Det gjennomføres en regulering for hele eiendommen med gnr/bnr 423/80. -Eiendommen skal reguleres i sin helhet Reguleringen skal avklare arealbehov for landbruk, friluftsliv og bygge- og anleggsformål, herunder HVS-senter, skole og boliger/gårdstun
Område 41 Røddevegen får næringsareal som formål
41. Område 51 Sandmoen
Område 51 Sandmoen får næringsbebyggelse

Overnatting tillates som formål
42. Område 912b Rotvolltrekanten
Hele Rotvolltrekanten får arealformålet kombinert bebyggelse og anlegg og næringsformål Det settes av areal til kollektivanlegg, kommunaltekniske anlegg, energianlegg, energistasjon og renovasjonsanlegg. Det skal legges til rette for næringsareal på resterende areal og over bussdepot, bydrift og energistasjon der dette er mulig.
43. HVS på Østmarka
Bystyret forutsetter at helse- og velferdssenteret på Østmarka skal utvikles i tråd med prinsippene og skissene som i vinnerprosjektet i Europan-konkurransen for området, og viser for øvrig til bestemmelsens § 30.2 hvor bl.a at det skal gjøres en artskartlegging, og at det ikke er tillatt å fjerne naturverdier før ny detaljreguleringsplan er vedtatt.
44. Område 941 Ranheimsvegen 305
Område 941 Ranheimsvegen 305 får byggesone 4 som formål
45. Område 964 Storfagerlibekken
Område 964 Storfagerlibekken får næringsareal som formål.
46. Deler av område 74 og 96 Brøttemsvegen (Torgård sør)
Området reguleres til næringsareal (150 daa)

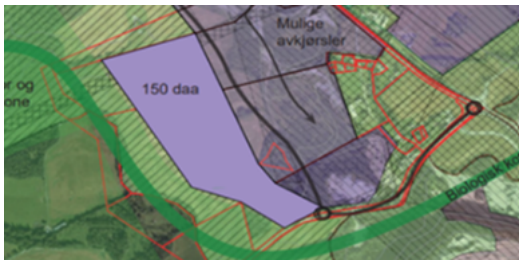

Område 333 Solbergåsen/Lundåsen
Område 333 Solbergåsen/Lundåsen avsettes til byggesone 3 og offentlig tjenesteyting Før planlegging eller gjennomføring av tiltak innenfor området skal behov for offentlig tjenesteyting avklares

Emil Raaen (Ap) fremmet følgende alternative forslag "Endringer i bestemmelser og retningslinjer":
1. Bystyret vedtar forslag til ny kommuneplanens arealdel 2022-2034 som vist på kart i målestokk 1:40 000, senest datert 07.05.2023, og med bestemmelser senest datert 07.05.2024 og beskrevet i planbeskrivelsen, senest datert 07.05.2024, og med de endringer som følger av bystyrets vedtak.

2. Kommuneplanen gjelder fra det tidspunkt planen er vedtatt av bystyret, og vil da gjelde for alle søknader om tiltak og forslag om regulering, jf. § 11-6. Unntak gis for planforslag som mottas som komplett innen seks måneder etter vedtaket av arealdelen. Planforslaget skal være komplett etter loven og krav gitt i Trondheim kommunes veileder for reguleringsplaner. Unntak forutsetter videre at føringer gitt i kommuneplanens arealdel for Trondheim 2012-2024 eller for Klæbu 2010-2021følges. En eventuell kombinasjon med føringer fra ny arealdel forutsetter at dette bidrar til bedre bolig- og bykvalitet.

Vedtaket fattes i henhold til plan- og bygningsloven § 11-15

3.Bystyret vedtar at det gjennomføres ny høring for de bestemmelser som etter dette vedtaket er nødvendig, før de tas opp til endelig sluttbehandling.

4. Bystyret vedtar følgende endringer til kommunedirektørens forslag til "Bestemmelser og retningslinjer", vedlegg 3:

Retningslinjer i kursiv

Ap 4.1. § 1 Formål
Kommuneplanens arealdel skal følge opp byutviklingsstrategien og målene i kommuneplanens samfunnsdel 2020-2032, Trondheimsløftet - sammen skaper vi Trondheim.
Planen bygger på sju hovedgrep for å oppnå dette:
1. holde bystrukturen samlet
2. differensiere tetthet og sikre attraktive bolig- og bymiljø
3. sikre rett virksomhet på rett sted, og nok areal til næring
4. bevare og tilbakeføre områder for landbruk, natur og friluftsliv
5. bevare særlig verdifulle naturtyper og matjord
6. legge til rette for et klima- og miljøvennlig transportmønster
7. legge føringer for klima- og miljøvennlige byggeprosjekt

Ap 4.2. § 2.2.3
Alle reguleringsplaner vedtatt etter 21.03.2013 går ved motstrid foran kommuneplanens arealdel. Unntatt er:
● ved motstrid med fremtidig LNFR, fremtidig idrettsanlegg,
● bestemmelsesområder, sikringssoner og/eller faresoner i kommuneplanens arealdel.
● minimum parkeringsdekning for bil og sykkel angitt i reguleringsplan, dersom § 14 i arealdelen oppfylles for planområdet i sin helhet. Tiltak som innebærer fjerning eller drenering av myr skal til politisk behandling.

For alle søknadspliktige byggetiltak gjelder uansett arealdelens § 4 om rekkefølgekrav, § 12.1 om overvannshåndtering, § 15 om energi og klima, og § 16.1 om klimarelatert risiko.

Reguleringsplan for Digresmyra skyteanlegg - r20090020 skal gjelde foran arealdelen, men ikke på områder avsatt til fremtidig LNFR.

Ap 4.3. § 4.2 Det er ikke **rekkefølgekrav om skolekapasitet** for boliger innenfor byggesone 1. Fritak for rekkefølgekrav i byggesone 2 kan innvilges gjennom reguleringsplan. Boliger kan ikke tas i bruk før leke- og uteoppholdsareal er etablert.

Ap 4.4. § 6.1 **Byggegrense mot sjø - Trondheimsfjorden**
Tiltak etter PBL § 1-6 første ledd utenom fasadeendringer kan ikke settes i verk nærmere strandlinjen, målt i horisontalplanet ved alminnelig høyvann, enn:
- Byggesone 1 og naust: 0 meter
- Byggesone 2-4 og øvrige byggeformål: 25 meter
- LNFR: 100 meter

Friluftslivstiltak kan tillates dersom viktige økologiske funksjoner blir opprettholdt. Det samme gjelder tiltak for å fremme naturmangfoldet, og tiltak som har til hensikt å reetablere historiske funksjoner.

Ap 4.5. § 6.2 Byggegrense mot vassdrag og innsjøer
Langs Gaula og Vikelva er tiltak etter pbl § 20-1 a, d, j, k og l ikke tillatt inntil 100 meter fra normal strandlinje. Nødvendige tiltak for drift, vedlikehold og fornying av eksisterende teknisk infrastruktur, veg og bane kan tillates. Ved gjenåpning av lukkede bekker kan mindre avstandskrav tillates.

Langs alle vassdrag med årssikker vannføring, inklusive elver, bekker, vann og tjern, gjelder

byggegrense på minimum 10 meter på hver side av vassdraget innenfor byggeområder og minimum 50-meter innenfor LNFR-områder. Dette gjelder både åpne og lukkede vassdrag.

Ap 4.6. § 6.4 Byggegrense Markagrensa (Rød strek)
Innenfor byggegrensen i plankartet skal det sikres et bærekraftig friluftsliv og et rikt og variert naturmiljø der viktige økologiske funksjoner opprettholdes. Kun skånsom tilrettelegging for idrett og friluftsliv, og tiltak i tråd med LNFR-formålet kan tillates.

Ap 4.7. § 6.6 Byggegrense mot formålet blå/grønnstruktur
Tiltak på eksisterende bebyggelse innenfor fire meter fra formålet blå/grønnstruktur og innenfor selve formålet er tillatt.

Bebyggelse bør ikke plasseres nærmere enn fire meter fra formålet blå/grønnstruktur. Dette gjelder ikke innenfor byggesone 1, eller frittliggende bygninger under 50 m² BRA som ikke skal benyttes til beboelse. Midlertidige tiltak som er reversible kan tillates innenfor formålet.

Ap 4.8. § 7.1 Folkehelse
Alle planforslag skal bidra til å utvikle sosialt bærekraftige lokalsamfunn, som motvirker utenforskap og bidrar til tilhørighet og deltakelse.

Støy og luftkvalitet, solforhold, tilgang til gode uteoppholdsarealer og sosiale møteplasser i gangavstand, tilrettelegging for fysisk aktivitet, kriminalitets- og ulykkesforebygging og tiltak for å utjevne sosiale helseforskjeller bør vektlegges.

Planforslag bør redegjøre for planens bidrag til kommunens mål for folkehelse og levekår, og virkninger for folkehelse i planområdet og influensområder.

Ap 4.9. § 7.2 Universell utforming
Alle planforslag skal redegjøre for universell utforming i planområdet og i sammenheng med omgivelsene. Der det kan oppstå konflikt mellom ulike hensyn, skal planarbeidet avveie alternative løsninger basert på prinsippet om inkludering og likestilt bruk, og hensynet til universell utforming skal veie tungt

Uttalelser fra kommunalt råd for personer med funksjonsnedsettelser, samt berørte organisasjoner, brukes som dokumentasjon i saker som omhandler universell utforming.

Ap 4.10. § 8.2 Arkitektur
Nye tiltak skal være i samspill med omgivelsene. Fargesetting og materialbruk skal bidra til variasjon i bymiljøet og bygge opp under Trondheims identitet.

Ap 4.11. § 8.4 Overordnede strukturer
Viktige landskapstrekk og landemerker, offentlige gater og byrom, blågrønne strukturer og offentlig tilgang til sjø og vassdrag skal være premissgivende for bystrukturen.

Byens viktigste landskapstrekk er høydedragene som omkranser byen, strandsonen, elveog bekkedalene, jordbrukslandskapet, sammenhengende grøntdrag og markante trær.

Ap 4.12. § 8.5 Høyhus
- Høyhus kan plasseres i allerede etablerte høyhusområder.
- Høyhus kan vurderes langs viktige innfartsårer og langs høyfrekvente kollektivårer, tilsvarende

metrobusslinjer.
- Høyhus kan vurderes der det skal signalisere større lokalt sentrum, allment tilgjengelige tilbud eller annen samfunnsmessig verdi.
- Høyhus kan vurderes der landskapsmessige og lokale forhold ellers tilsier det.

Høyhus er her bygg over 10 etasjer.

Ap 4.13. § 8.6 Svalganger
Ved etablering av svalganger skal disse ha høy kvalitet i form og materialbruk.
Svalganger bør som hovedregel ikke legges mot offentlige gater og byrom.

Ap 4.14. § 10.3 Fellesarealer innendørs
Ved planforslag med 20 boliger eller mer skal det sikres etablering av et samlet innendørs felles oppholdsareal.

Retningslinjer for innendørs fellesarealer:
- for 20-50 boenheter: 30 m2
- for 50-100 boenheter: 50 m2
- for over 100 boenheter: 75 m2, pluss 0,5 m2 per boenhet over 100 boenheter

Fellesarealet bør ligge i første etasje og ha direkte kontakt med gaterommet og hovedadkomst til boligene. Ekstra fellesareal for over 100 boenheter kan inneholde andre fellesfunksjoner, som gjesteleilighet, verksted eller kjøkken, men med kvaliteter tilsvarende oppholdsrom. Krav til støyskjerming kan oppfylles i fasaden.

Ap 4.15. § 10.4 Uteoppholdsareal
Ved planforslag og søknad om byggetiltak skal alle boenheter innenfor planområdet eller tiltaket ha minste uteoppholdsareal (MUA) i samsvar med tabellen under.

Kravet for byggesone 1 - felt S1 utenfor Midtbyhalvøya og felt S2-5 - reduseres med 5 m2 per boenhet/100 m2 boareal dersom offentlig park/torg på minimum 500 m2 er etablert i den aktuelle sentrumskjernen eller innenfor 100 m fra boligene.

Sone	Per boenhet eller per 100 m2	Plassering og fordeling
Byggesone 1, innenfor Midtbyhalvøya	10 m2	- minst 50 % som fellesareal - kravet om eget uteoppholdsareal kan fravikes dersom det ikke er mulig å legge til rette for uteoppholdsareal, og det sikres tilgang til tilstrekkelig og kvalitativt gode leke- og uteoppholdsareal i trafikksikker gangavstand på maksimalt 200 m fra boligene
Byggesone 1, felt S1 utenom Midtbyhalvøya	30 m2	- minst 50 % som fellesareal

Byggesone 1, felt S2 - S5	30 m2	- minst 50 % som fellesareal (hvorav minst 20 % på bakkeplan)
Byggesone 2	40 m2	- minst 50 % som fellesareal (hvorav minst 50 % på bakkeplan)
Byggesone 3 under 20 boenheter	70 m2	- ved mer enn tre boenheter: minst 40 % som fellesareal (hovrav minst 60% på bakkeplan) - minimum halvparten av alle boenheter skal ha privat uteoppholdsareal på bakkeplan eller balkong (alle boenheter skal ha privat uteoppholdsareal på bakkeplan eller balkong)
Byggesone 3 over 20 boenheter	50 m2	
Byggesone 4	75 m2	Utformet som privat uteoppholdsareal på bakkeplan.

BRA ved beregning av uteoppholdsareal skal inkludere alt bruksareal til bolig. Annet bruksareal i kjeller (herunder boder), uteoppholdsareal eller innendørs fellesareal skal ikke medregnes.

Minste uteoppholdsareal skal oppfylle følgende kvalitetskrav:
- Alle boenheter bør ha maksimalt 100 meter trygg gangavstand fra hovedinngang i bygget til nærmeste del av uteoppholdsarealet på bakkeplan.
- Minst halve arealet bør ha sol i minst 3 timer ved vårjevndøgn etter klokka 12, samt klokka 18 midtsommers.

Minste uteoppholdsareal bør i tillegg oppfylle følgende retningslinjer:
-Arealet bør være mest mulig sammenhengende, og små eller smale oppstykkede arealer skal unngås. Areal som er brattere enn 1:3 kan ikke medregnes hvis ikke arealet har særlige bruksverdier. Areal mindre enn to meter fra private vinduer inn mot oppholdsrom kan ikke medregnes som felles uteoppholdsareal.
- Areal som kreves lagt på bakkeplan skal ligge på naturlig terreng, eller på dekke med god terrengkontakt, dimensjonert for å kunne bære permanent vegetasjonsdekke.
- Tellende uteoppholdsareal bør være skjermet mot motorisert trafikk og forurensing, og tilfredsstille grenseverdiene i tabell 2 i T-1442/21. Unntak er inntil ¼-del av felles uteoppholdsareal i byggesone 1, som kan ha støy inntil 3 dB over grenseverdi angitt i T-1442/21, men areal særlig tilrettelagt for barn og unge kan ikke etableres her.

Tekniske installasjoner som trafokiosker, høyspentrom og lufteanlegg bør plasseres slik at de ikke reduserer kvalitet og bruksverdi på uteoppholdsarealene. Boenheter i første etasje bør ha oppholdsareal på terreng i direkte tilknytning til boenheten.

Ap 4.16. § 11.2 Vegetasjon
Verdifull vegetasjon bør i størst mulig grad etterstrebes bevart. Ved utarbeidelse av planforslag og søknad om tiltak bør det legges til rette for ny vegetasjon i form av trær og annen vegetasjon, grønne tak og fasader eller andre grønne elementer som kan bidra til å styrke naturmangfold og økosystemtjenester.

Verdifull vegetasjon er bytrær, store trær og annen vegetasjon med stor betydning for naturmangfold, kulturhistorie, stedsidentitet, landskapsbilde, lokalklima, fordrøyning, og/eller karbonlagring.

Ap 4.17. § 11.3 Karbonrike arealer
Forslag om fjerning eller drenering av myr, og omdisponering av skog med høy bonitet, skal vurderes og utredes i hvert enkelt tilfelle.

Det tillates ikke nedbygging av arealer vist som myr og våtmark, eller skog med høy bonitet i AR5 på www.kilden.nibio.no.

Ap 4.18. § 12.1 Overvannshåndtering
Planforslag og søknad om tiltak skal identifisere, dimensjonere og sikre arealer for overvannshåndtering og flomveger i tre trinn i tråd med Trondheim kommunes VA-norm og sanitærreglement.

Overvann bør søkes utnyttet som positivt element i bymiljøet og styrke lokalt naturmangfold. Andre løsninger må begrunnes. Utfyllende beskrivelse av overvannshåndtering i tre trinn er gitt i Trondheim kommunes VA-norm.

I "Middelalderbyen" skal overvannshåndtering planlegges i samråd med arkeologisk fagmiljø/Riksantikvaren.

Ap 4.19. § 12.2 Blågrønn faktor
Alle planforslag bør dokumentere at Trondheim kommunes norm for blågrønn faktor kan oppfylles ved gjennomføring av planen. Ved tiltak som er omfattet av pbl § 20-1 a og l, bør Trondheim kommunes norm for blågrønn faktor være dokumentert oppfylt.

Ved andre tiltak eller tiltak etter reguleringsplan vedtatt før kommuneplanens arealdel 2022-2034 bør det tilstrebes å oppnå normkrav til blågrønn faktor.

Ap 4.20. § 12.3 Vassdrag
Bredden på kantsonen på hver side av vassdraget skal være minimum 10 meter innenfor tettbebygde områder og 50-meter innenfor LNFR-områder.

Lukking av vassdrag eller andre tiltak som forringer økologiske funksjoner i og ved vassdrag er som hovedregel ikke tillatt. Nødvendige tiltak for drift, vedlikehold og fornying av eksisterende teknisk infrastruktur for veg og bane kan tillates, men skal i størst mulig grad ivareta økologiske funksjoner.

Ved reguleringsplaner som berører lukkede eller sterkt påvirkede vassdrag bør det alltid vurderes om vassdraget kan gjenåpnes og restaureres. Ved behov skal det avsettes areal for tiltak mot partikkelavrenning og annen forurensning til vassdrag. Det bør legges vekt på å ivareta og der det er mulig reetablere et belte med naturlig kantvegetasjon.

Ap 4.21. § 13.1 Generelt
Transportsystemet skal bidra til en attraktiv by, at flere går, sykler og reiser kollektivt og at viktige samfunnsfunksjoner har nødvendig fremkommelighet.

Bystrukturen skal planlegges slik at byens gater og byrom gir et attraktivt og finmasket gangnett som gir kort adkomst til viktige målpunkt.

Ved planlegging av nye samferdselsanlegg bør etablering av allé eller trær vurderes. For eksisterende alleer og trerekker bør trær og tilstrekkelig rotsone bevares. Allétrær som fjernes bør

erstattes.

Fortau bør opparbeides med minst 2 meter asfaltert bredde og reguleres med 2,5 meter bredde for å inkludere skulderareal. I private blindveger uten gjennomgang kan 1,5 meter asfaltert bredde aksepteres hvis de betjener færre enn 50 boenheter.

Ap 4.22. § 13.2 Innenfor tettstedene
Samferdselsanlegg innenfor byggesone 1-3 og ellers innenfor tettstedene skal som hovedregel utformes som gater for lav fart og med areal til blågrønne kvaliteter. Unntak er fjernveger og skinnegående transport.

Tilrettelegging for kryssing for fotgjengere bør være på bakkeplan, unntatt over fjernveg. Annen løsning kan vurderes der alternativet sikrer en mer effektiv gang- og sykkelforbindelse. Planskilte kryss kan vurderes som et tillegg der dette er nødvendig for å sikre trygg skoleveg.

Ap 4.23. § 13.4 Mobilitetsutredning
I planforslag skal det redegjøres for hvordan planforslaget vil bidra til at flere går, sykler og reiser kollektivt.
Relevante tiltak fra mobilitetsutredningen bør sikres i reguleringsplanen.
Mobilitetsutredningen bør vise:
1. Forventet transportbehov: reiser til/fra bolig/virksomhet, besøksreiser, varelevering, godstransport.
2. Tilbud for gående, syklende, kollektivtrafikk og kjørende.
3. Trafikksikkerhet og fremkommelighet for gående, syklende, kollektivtrafikk og utrykningskjøretøy.
4. Tiltak for å bedre tilgjengeligheten for gående, syklende og kollektivreisende.
5. Parkeringstilbud for bil og sykkel, herunder plassering, utforming og ladeinfrastruktur. Det bør illustreres hvordan antall plasser er tenkt fordelt på personer med nedsatt funksjonsevne, beboere, besøkende, kunder, tjenesteytere og bildeling. Det bør også fremkomme om parkering kan samlokaliseres med andre boligfelt eller virksomheter i området.
6. Behov for regulering av offentlige gater i det aktuelle influensområdet for å begrense parkering utenfor eiendom.
7. Løsninger for renovasjon og varelevering.
8. For planlagt ny næringsbebyggelse skal det også foreligge en vurdering av om lokaliseringen er i samsvar med målsettingen om rett virksomhet på rett sted (§ 18).

Ap 4.24. § 13.5 Fjernveg
Langs fjernveg skal effektiv og trafikksikker fremkommelighet for motoriserte kjøretøy prioriteres.

Antall avkjørsler bør begrenses.

Ap 4.25. § 13.8 Sykkelnett
Langs sykkelnettet skal det sikres et sammenhengende tilbud for syklende som oppleves som trygt og enkelt å bruke.

Det bør sikres gjennomgående tilbud for sykkel i kryss.

Der sykkelnett sammenfaller med hovedveg og/eller kollektivtrasé bør det hovedsakelig tilrettelegges for beskyttet sykkelanlegg. Bruk av fortau og fotgjengeroverganger ved kryssing bør unngås som del av tilbudet for syklister i sykkelnettet.

Ap 4.26. § 13.9 Turveg
Turveger vist på plankartet er viktige overordnede gangforbindelser som kobler turvegnettet sammen og gir sammenheng mellom marka og de andre overordnede grønne områdene. Turveger vist i byggeområder kan reguleres til og utformes som gangveg.

Ap 4.27. § 14.1 Antall parkeringsplasser for boligbebyggelse
Det skal avsettes plass for biler og sykler i samsvar med følgende norm:

Tabell 2 – Antall parkeringsplasser for boligbebyggelse

<table>
<tr><th>Byggesone</th><th>Sykkel</th><th>Bil – per 100 m2 BRA</th></tr>
<tr><td>Byggesone 1 – felt S1</td><td rowspan="5">Minimum 3 parkeringsplass pr. 100 m2, eller 1,5 parkeringsplass per boenhet.

(Største tall av 3 parkeringsplass pr. 100 m2
og 1,5 parkeringsplass per
boenhet)</td><td>Midtbyen: min 0/S1: min 0</td></tr>
<tr><td>Byggesone 1 – felt S2-S5</td><td>min 0.1 – maks 0.8</td></tr>
<tr><td>Byggesone 2</td><td>min. 0.2 – maks 1</td></tr>
<tr><td>Byggesone 3</td><td>min.0.4 – maks1.2</td></tr>
<tr><td>Øvrige soner</td><td>min. 0.6 – maks 1.5</td></tr>
<tr><td>Frittliggende eneboliger og tomannsboliger i byggesone 3 og øvrige soner</td><td>4 pr. boenhet</td><td>min. 1 pr. boenhet</td></tr>
</table>

Avrundingsregel: Det rundes opp til nærmeste hele tall.

Ap 4.28. § 14.2 Antall parkeringsplasser for kontor, forretning og privat tjenesteyting
Det skal avsettes plass for biler og sykler per 100 m2 BRA i samsvar med følgende norm, gjelder ikke for virksomheters nyttekjøretøy:

Tabell 3 - Antall parkengsplasser for kontor, forretning og privat tjenesteyting

<table>
<tr><th colspan="3">Sykkel</th><th colspan="3">Bil</th></tr>
<tr><td>Forretning</td><td>Kontor</td><td>Privat tjenesteyting</td><td>Forretning</td><td>Kontor</td><td>Privat tjenesteyting</td></tr>
<tr><td>Min. 2</td><td>Min. 2</td><td>Min. 2</td><td>Max. 3</td><td>Byggesone 1: Maks 0.2
Byggesone 2: Maks 0.5
Byggesone 3: Maks 0.8
Øvrige soner: Maks</td><td>Min. 0,8</td></tr>
</table>

				2	

Avrundingsregel: Minimumskrav rundes opp og maksimumskrav rundes ned til nærmeste hele tall.

Ap 4.29. § 14.3 Bilparkeringsplasser for personer med nedsatt bevegelsesevne
Ved søknad om tiltak og ved utarbeidelse av planer skal det etableres minst 1 plass, unntatt ved frittliggende en- og tomannsboliger. Kravet til antall plasser skal for øvrig være den høyeste verdien av enten:
- 5 prosent av alle bilparkeringsplassene
- 1 bilparkeringsplass pr. 1500 m2 BRA

Etablering av slike parkeringsplasser bør ivareta følgende:
Parkeringsplassene bør maksimalt ligge 25 meter fra hovedinngang.
Parkeringsplassene bør fordeles mellom parkeringskjeller og gateplan, for å sikre et godt tilbud til ulike grupper av personer med nedsatt bevegelsesevne og biler med ekstra stor høyde.

Ap 4.30. § 14.4 Bilparkeringsplasser for besøkende og nyttekjøretøy.
I tillegg til parkeringsplasser etablert etter § 14.1 og § 14.2, skal det etableres bilparkeringsplasser for besøkende og nyttekjøretøy.

Antall parkeringsplasser skal vurderes og fastsettes i den enkelte reguleringsplan.

Det bør alltid sikres minst 1 parkeringsplass.

Ap 4.31. § 14.5.1 Plassering
Plassering av parkeringsplasser skal vurderes og fastsettes i den enkelte reguleringsplan eller byggesak. Felles parkeringsanlegg skal som hovedregel anlegges ved kjøreadkomst fra veg.

Ved anleggelse av flere enn åtte parkeringsplasser, bør det vurderes å samle disse i felles parkeringsanlegg.

Ap 4.32. § 14.5.2 Utforming
Etablering av nye parkeringsplasser skal ta utgangspunkt i anbefalinger gitt gjennom SINTEFs anvisning for utforming og dimensjonering av parkeringsanlegg.

Ved vedlikehold av eksisterende anlegg kan 2,3 meters bredde aksepteres.

Det bør sikres fri høyde på minst 2,6 meter på HC-parkeringsplass ved hovedinngang eller heis.

Ap 4.33. § 15.4 Fjernvarme
Ved utbygging eller ved hovedombygging med samlet areal over 1000 m2 BRA innenfor gjeldende konsesjonsområde for fjernvarme skal bebyggelsen tilknyttes fjernvarmeanlegg.

Det kan fritas for tilknytningsplikt til fjernvarme hvis det dokumenteres at klimagassutslippene ved andre energiløsninger er lavere, og/eller belastningen på el-nettet blir akseptabel. Nødvendig anleggsarbeid for å etablere løsningene bør inkluderes i klimagassberegningen.

Akseptabel belastning på el-nettet tilsier at varmeløsningen ved dimensjonerende utetemperatur ikke belaster el-nettet vesentlig mer enn tilsvarende bygg som tilfredsstiller gjeldende byggteknisk forskrift og som benytter fjernvarme som primærvarmekilde.

Ap 4.34. § 17.3 Næringsavfall
I byggesone 1 og 2 skal næringsavfall løses innomhus.

I øvrige byggeområder skal næringsavfall løses på egen grunn og fortrinnsvis innomhus. Utomhus bør det tilstrebes nedgravde oppsamlingsløsninger.

I byggesone 1 og 2 bør det vurderes om næringsarealer kan ha felles renovasjonsløsning med husholdninger i samme bygg eller på nærliggende tomt.

Ap 4.35. § 17.4 Offentlig returpunkt og ombrukssentral
Ved planlegging og oppføring av nye bygg på over 1000 m2 BRA i byggesone 1, 2 eller 3 må det avklares om det skal sikres areal til offentlige returpunkt for renovasjon.

Ved planlegging av boliger i byggesone 1 og 2 bør areal til ombrukssentral vurderes.

Ap 4.36. § 18 Rett virksomhet på rett sted
Virksomheter skal lokaliseres etter prinsippet rett virksomhet på rett sted. Støyende virksomheter og virksomheter med sikkerhetssoner skal etableres med god avstand fra boliger eller andre følsomme formål.

Prinsippet rett virksomhet på rett sted innebærer blant annet:

-Arbeidsplassintensive virksomheter, som kontor, bør lokaliseres langs kollektivbuen mellom Sluppen og Strindheim, i tilknytning til kollektivknutepunktene Heimdal, Tiller og Strindheim, eller i lokale sentrumskjerner. I disse områdene bør arbeidsplassintensive virksomheter etableres innenfor byggesone 1, byggesone 2 eller fra andre etasje og opp innenfor formålet næringsbebyggelse der dette er vedtatt i arealplanen.

-Hotell skal kun tillates innenfor Midtbyen og sentrumsområdene rundt (felt S1) og i de største knutepunktene (felt S2).

-Publikumsrettede virksomheter, som handel, tjenesteyting og andre kultur- og servicetilbud som har kommunen eller regionen som omland, bør fortrinnsvis lokaliseres i byggesone 1 - S1, på Midtbyhalvøya. Små publikumsrettede virksomheter med lokalt nedslagsfelt skal kun tillates i byggesone 1, og på inntil 400 m2 BRA i byggesone 2.

-Forretninger generelt kan lokaliseres i byggesone 1. Dagligvareforretninger på inntil 2000 m2 BRA kan vurderes tillatt i byggesone 2 og 3 gjennom detaljreguleringsplan. Forretninger for plasskrevende varer kan tillates gjennom reguleringsplan innenfor arealer avsatt til næringsbebyggelse merket NF på Tiller. BRA for handel defineres som summen av salgsflate, lagerlokale, spiserom/kantine og kontorareal som er nødvendig for driften. Areal til parkering og varelevering inngår ikke.

-Næringsvirksomheter med få besøkende, som bygg- og anleggsvirksomheter, håndverkere, teknologi og produksjonsvirksomheter, bør lokaliseres innenfor formålet næringsbebyggelse, eller innenfor byggesone 1-3. Virksomheter som ikke kan tilpasses bystrukturen eller fører til vesentlig støy- og trafikkbelastning for omgivelsene bør ikke lokaliseres i byggesone 1-3.

-Arealkrevende næringsvirksomheter med behov for nærhet til hovedvegnettet skal fortrinnsvis lokaliseres innenfor formålet næringsbebyggelse i felt merket NA.

*Ved arbeidsintensiv virksomhet/kontorfo*rmål *bør det settes av areal til uteoppholdsareal for ansatte.*

Ap 4.37. § 20.3 Elektromagnetiske felt
Ved etablering av boliger, barnehager, skoler og uteoppholdsområder nær høyspentanlegg eller transformatorstasjoner, skal det foretas en utredning av virkningene dersom det elektromagnetiske feltet ved gjennomsnittlig årlig strømbelastning overstiger 0,4 µT. Det samme gjelder ved etablering av høyspentanlegg eller transformatorstasjoner. Utredningene skal foreslå avbøtende tiltak.

Ap 4.38. § 22 Plan for bygge- og anleggsfasen
Plan for beskyttelse av omgivelsene i bygge- og anleggsfasen skal foreligge før arbeidet kan igangsettes.

Nødvendige beskyttelsestiltak skal være etablert før bygge- og anleggsarbeider kan igangsettes. I bygge- og anleggsfasen skal det være god framkommelighet, trafikksikkerhet og orienterbarhet for gående, syklende og kollektivtransport.

Planen bør redegjøre for trafikkavvikling, massetransport, driftstider, støyforhold, rystelser og vibrasjoner, ivaretakelse av terreng og verdifull vegetasjon, renhold og støvdemping, framkommelighet og trafikksikkerhet for gående, syklende og kollektivtransport, håndtering av avrenning for å ivareta hensyn til vannmiljø og avløpsnett samt tiltak for å redusere klimagassutslipp.

Tiltakshaver er ansvarlig for at planen foreligger, at planen er tilgjengelig på bygge-/anleggsplassen og at den er kjent for foretakene som utfører arbeid. Det bør vises hvordan kravene i §§ 15.4, 19.6 og 20.2 tilfredsstilles og dokumenteres i bygge-og anleggsfasen. Ved større prosjekter bør planen revideres. Ved flere utbygginger i samme område bør tiltakene samordnes.

Ap 4.39. § 23.1 Felles formålsbestemmelser byggesone 1-4
Byggesone 1 og 2 utgjør tilsammen de mest sentrale byområdene i kommunen, hvor det skal legges til rette for at hovedandelen av nye boliger lokaliseres.

Arbeidsplassintensive virksomheter skal lokaliseres i byggesone 1 og 2 langs kollektivbuen og ved de store knutepunktene. Byggesone 1 og 2 skal samtidig utvikles med et mangfold av publikumsfunksjoner tilpasset stedets omland, og et aktivt og levende bymiljø.

Byggesone 2 og 3 skal videreutvikles som områder for boliger med innslag av næring, og nødvendig areal til tjenesteyting og idrett. Virksomheter som gir vesentlig belastning på tilliggende vegnett, bymiljø og bomiljøer tillates ikke i byggesone 2 og 3. Byggesone 4 skal ikke utvikles vesentlig.

Ved regulering kan mindre justeringer av grensene mellom byggesonene vurderes etter en stedsanalyse. Dette for å sikre bedre utnyttelse av arealer innenfor byggesonene og bedre tilpasning til etablert gate- og bebyggelsesstruktur, samt hensynta naturlige terrengavgrensninger, viktige natur- og kulturhistoriske verdier eller fjernvirkning i landskapet.

Alle byggesonene skal utvikles på en måte som bidrar til å skape en inkluderende by, der bymiljø og møteplasser er tilgjengelige og åpne for alle.

Dagligvarehandel skal lokaliseres i tilknytning til bydelens gang- og sykkelnett og nært godt

kollektivtilbud.

For alle planforslag skal det tidlig i planprosessen avklares behov for å innpasse areal til nye, eller utvidelse av eksisterende, offentlige funksjoner eller annen nødvendig infrastruktur.

Ap 4.40. § 23.2 Felles bestemmelser byggesone 1 og 2
Områdene skal utvikles etter bymessige prinsipper, med høy tetthet og kvalitet, og sammenhengende byromsnettverk.

Ny bebyggelse skal utformes og plasseres slik at den ikke er til hinder for at omkringliggende eiendommer kan utvikles med tilsvarende tetthet og kvalitet, der hvor dette kan være aktuelt.

Langs fasader som henvender seg mot hovegater og offentlige byrom skal det vurderes etablert utendørs møbleringssone som muliggjør tilrettelegging for utendørs byliv.

Første etasje, herunder areal på bakkeplan trukket inn under tak, ut mot sentrale offentlige gater, gangveger og byrom bør i hovedsak ikke inneholde parkeringsanlegg, boder og lager, samt større rom for tekniske anlegg.

Stopp for tjeneste- og varelevering og renovasjonsbiler bør fortrinnsvis etableres i forbindelse med møbleringssone langs sidegater. Det skal tilstrebes et finmasket gangnett. Ved planlegging av ny bebyggelsesstruktur bør kvartaler ha maksimal bredde/lengde på 70 meter, og fasadene underdeles med sprang i fasadeliv og variert material- og fargebruk minst hver 30 meter. Føresteetasjer ut mot sentrale offentlige gater, gangveger og byrom bør ligge på samme nivå som gateplan for å muliggjøre innganger fra gata. Felles oppholdsrom for flere boenheter, kantiner eller lignende skal fortrinnsvis plasseres her. Som en mindre del av møbleringsarealet langs gater kan det etableres langsgående offentlig korttidsparkering for besøkende, HC parkering og taxi.

Ap 4.41. § 23.3.2 Arealbruk
Innenfor byggesone 1 tillates følgende formål: boligbebyggelse, sentrumsformål, forretninger, tjenesteyting, idrettsanlegg, næringsbebyggelse. Arealkrevende næring tillates ikke foruten næringer i bestemmelsesområde #1 kaibaserte næringer på Nyhavna.

Bebyggelsens første etasje ut mot sentrale offentlig gater og byrom bør fortrinnsvis inneholde utadrettet virksomhet, eventuelt innendørs fellesareal og kantiner.

Første etasje i nye bygg bør ikke inneholde boenheter ut mot sentrale offentlige gater, gangveger og byrom, dersom arealet vurderes som egnet til fellesfunksjoner eller publikumsrettet virksomhet.

Ap 4.42. § 23.3.3 Utforming av bystruktur og bebyggelse
Sentrumsstrategien og Gatebruksplan for Midtbyen skal legges til grunn som for planforslag i byggesone 1, felt S1_Midtbyen og Trondheim sentrum.

For planforslag i sentrumskjerner felt S2-5 skal det utarbeides stedsanalyse for hele sentrumskjernen, samt tilgrensende områder.

Arealene i etasje på gateplan bør være fleksible for ulike typer virksomheter og enhetsinndeling.

Mot torg og sentrale gaterom/strøk skal fasader i første etasje ha et åpent uttrykk og en stor andel

vinduer, samt dører med direkte adkomst fra gateplan. Vinduer skal ikke dekkes med folie eller lignende.

Ap 4.43. § 23.3.4 Bymiljø
Ved etablering av nye byggetiltak over 1000 m2 BRA helt eller delvis innenfor felt S2-4 skal offentlig torg eller park på minst 500 m2 etableres der dette ikke finnes fra før.

Sentrale offentlige gater skal opparbeides som byrom med plass for opphold, møblering og trær. Utforming av trafikkarealer skal tilpasses lav fart for kjørende.

Alle offentlige byrom opparbeides med høy bymessig kvalitet. Eventuelle ramper til parkeringsanlegg integreres i bebyggelsens hovedvolumer.

Parkering bør plasseres i fellesanlegg i utkanten av eller utenfor sentrumskjernen.

Ap 4.44. § 23.4.2 Arealbruk
Innenfor byggesone 2 tillates følgende formål: boligbebyggelse, sentrumsformål, offentlig tjenesteyting, privat tjenesteyting inntil 400 m2 BRA, idrettsanlegg, næringsbebyggelse. Publikumsrettede virksomheter og forretning knyttet til service- og håndverksvirksomheter med mange besøkende kan tillates gjennom detaljreguleringsplan.

I eksisterende bebyggelse av antikvarisk verdi klasse A-C tillates formål som kan bidra til at bebyggelsen fortsatt kan være i bruk.

Ap 4.45. § 23.5.1 Utnyttelsesgrad
Grad av utnytting tilpasses områdets strøkskarakter, samtidig som hensiktsmessig utnyttelse av arealet sikres.

Ivaretakelse av eksisterende bomiljø, naturverdier og kulturhistoriske verdier bør tillegges stor vekt ved nye bygninger og andre tiltak. Fotavtrykk og høyder på ny bebyggelse bør ikke være vesentlig større enn eksisterende bebyggelse, og ikke større enn at grønn karakter og landskapstrekk ivaretas.

Ved planlegging av større nye byggeområder eller transformasjonsområder bør det legges vekt på effektiv arealbruk innenfor de rammene som for øvrig er gitt i bestemmelsene. Andel areal på bakkeplan avsatt til kjøring og parkering bør begrenses.

Ap 4.46. §23.5.2 Arealbruk
Innenfor byggesone 3 tillates boligbebyggelse, offentlig tjenesteyting, idrettsanlegg, næringsbebyggelse og privat tjenesteyting inntil 400 m2 BRA.

Forretning knyttet til service- og håndverksvirksomheter tillates på inntil 25 % av virksomhetens BRA.

I eksisterende bebyggelse av antikvarisk verdi klasse A-C tillates også tjenesteyting som kan bidra til at bebyggelsen fortsatt kan være i bruk.

Ap 4.47. § 23.6.1 Utnyttelsesgrad
Grad av utnytting skal ikke overstige 50 % BRA.

Ivaretakelse av eksisterende bomiljø, naturverdier og kulturhistoriske verdier bør tillegges stor vekt ved nye bygninger og andre tiltak.

Ap 4.48. § 23.6.2 Arealbruk
Innenfor byggesone 4 tillates boligbebyggelse, offentlig tjenesteyting, idrettsanlegg, privat tjenesteyting inntil 200 m2 BRA og næringsvirksomheter som ikke medfører støy, forurensning eller andre ulemper for omgivelsene. Det tillates ikke nyetablering eller bruksendring for tiltak med høy arbeidsplass- eller besøksintensitet.

Areal bør i hovedsak benyttes til bolig. For eksisterende bebyggelse av antikvarisk verdi klasse A-C tillates formål som kan bidra til at bebyggelsen fortsatt kan være i bruk.

Ap 4.49. § 24.1.1 Generelle bestemmelser
Det må foreligge godkjent avløpsløsning med felles ledningsnett knyttet til kommunalt nett eller eget renseanlegg før igangsettingstillatelse kan gis.

Fritidsbebyggelse bør tilpasses tomtearealet, og som hovedregel ha maksimalt 80 m2 BRA for hovedbygg.

Ap 4.50. § 24.2 Tjenesteyting (1160)
Arealene vist som tjenesteyting skal benyttes til barnehager, skoler, helse- og omsorgsinstitusjoner, brannstasjoner, fengsel, museer og kirker/religiøse forsamlingslokaler. Idrettsanlegg tillates etablert innenfor formålet.

Felles bestemmelser for byggesone 1 og 2 - § 23.2 og tilhørende retningslinjer - bør gjelde for utforming av bebyggelse, bymiljø og samferdsel innenfor formålet tjenesteyting. Det bør legges vekt på effektiv arealbruk innenfor de rammene som for øvrig er gitt i bestemmelsene. Andel areal på bakkeplan avsatt til kjøring og parkering bør begrenses.

Minimum uteoppholdsareal til offentlig tjenesteyting:
-Barnehager: 24 m2 godt egnet uteoppholdsareal per barn.
-Skole: 25 m2 godt egnet uteoppholdsareal per elev. Deler kan være regulert som offentlig friområde.
-Helse- og velferdssenter: 25 m2 godt egnet uteoppholdsareal per 100 m2 bruksareal.

Ap 4.51. § 24.3 Råstoffutvinning (1200)
Ved planforslag og behandling av søknad om råstoffutvinning skal det foreligge en vurdering av miljøbelastninger for influensområdet knyttet til driften og transport til og fra området, geotekniske forhold, landbruksfaglige forhold, landskap/ stedskvalitet og biologisk naturmangfold.

Etterbruk til LNFR bør sikres i reguleringsplan. Jordbruksarealer bør istandsettes til jordbruksdrift. Felt merket RN kan ha næringsbebyggelse som etterbruk. Dette bør sikres i reguleringsplan.

T-1442 og T-1520 skal ligge til grunn for vurderingene av støy og luftkvalitet.

Ap 4.52. § 24.4.1 Innhold
Innenfor formålet kan det etableres næringsvirksomheter i tråd med prinsippet for rett virksomhet på rett sted. Energianlegg tillates. Ved søknad om tiltak gjelder formål angitt i vedtatt reguleringsplan foran formål angitt i arealdelen dersom motstrid.

I*nnenfor arealer avsatt til næringsbebyggelse bør det kun tillates håndverk og industri (1340), lager (1350) og bensin-/energistasjon (1360), samt energianlegg. Dette med unntak av 1) på Strindheim mellom jernbanen og Innherredsveien, hvor det fra andre etasje og opp kan etableres kontor, og 2) på Tunga, der næringsarealene bør forbeholdes industri, plasskrevende varehandel og næringer samt produksjons- og lager/logistikkvirksomheter. Kontorlokaler fra andre etasje og opp kan her tillates gjennom reguleringsplan. (1310) Kontor fra andre etasje og opp over forretninger for plasskrevende varehandel tillates som hovedregel ikke.*

Innenfor felt merket NA bør næringsarealene forbeholdes større produksjons- og lager/logistikkvirksomheter med behov for stort, sammenhengende areal.

På Tiller i felter merket NF kan det vurderes tillatt forretning for plasskrevende varegrupper gjennom reguleringsplan.

Det vises for øvrig til retningslinjene under § 18 Rett virksomhet på rett sted.

Ap 4.53. § 24.4.2 Utnyttelse og utforming
Effektiv arealutnyttelse skal ivaretas gjennom høy tetthet tilpasset omgivelsene og områdets tilgjengelighet i henhold til prinsippet om rett virksomhet på rett sted.

-Alle planforslag og søknader om tiltak bør vise hvordan plassering og utforming av bebyggelse og adkomster bidrar til effektiv arealutnyttelse for tomta og tilsluttende næringsarealer. Det bør primært etableres felles renovasjon og varelevering. Varelevering bør etableres slik at det ikke er til unødig ulempe for omgivelsene.

-For å sikre tilstrekkelig areal til virksomhetenes arealkrevende funksjoner bør arealene på bakkeplan både ute og inne reserveres til disse funksjonene. I ytterkant av næringsområdene, mot samferdselsanlegg, boliger og andre områder for opphold, bør det etableres visuell skjerming ved bruk av vegetasjon. Dette gjelder ikke for nåværende næringsbebyggelse langs Haakon VII's gate vest for Leangen allé.

Det bør legges til rette for uteoppholdsareal for ansatte

Belysning skal utformes slik at landbruks-, natur- og friluftslivsområder skjermes mot lysforurensning.

Ap 4.54. § 24.7.5 Fossegrenda KB 5
Innenfor område KB tillates bolig og næring med minimum utnyttelse 100% BRA

Ved detaljregulering skal det sikres minimum 50% BRA utnyttelse til lager og industri
Virksomheten må ikke føre til vesentlig støy og trafikkbelastning for omgivelsene

Ap 4.55. § 25.1 Opparbeidelse og bruk (blågrønn struktur)
Formålet omfatter naturområder, turdrag, friområder og parker. Sammenhengene i blå/grønnstrukturen, eksisterende naturverdier og økologiske funksjoner skal ivaretas og styrkes.

Tiltak for å fremme friluftsliv, lek og rekreasjon tillates. Andre tiltak tillates som hovedregel ikke. Unntak er bruk av bebyggelse med antikvarisk verdi klasse A-C, som kan benyttes til funksjoner innenfor formålene tjenesteyting og bevertning.

Arter oppført på listen over fremmede arter og/eller definert som problemart i Trondheim skal

unngås i blå/grønnstrukturen. Det bør i størst mulig grad brukes vegetasjon som er naturlig for stedet.

Ap 4.56. § 25.2 Offentlige parker
Arealene skal gi tilbud til alle og være offentlig tilgjengelige. Overvannshåndtering skal være ivaretatt.

Materialbruk og utførelse bør ha høy kvalitet og sikre lang levetid ved høy bruksintensitet. All vegetasjon bør sikres gode vekstforhold. Der offentlig park etableres på tak eller konstruksjoner under bakken bør konstruksjonen dimensjoneres til å tåle etablering av trær, vegetasjon og jordoverdekning, samt vedlikeholdskjøretøy.

Ap 4.57. § 26.1 Generelle bestemmelser
LNFR-områder er det ikke tillatt å gjøre bruksendringer eller oppføre nye bygninger, nye boenheter eller andre konstruksjoner og anlegg. Det samme gjelder fradeling til slike formål. Unntatt er tiltak knyttet til stedbunden næring, og tiltak som kan styrke ressursgrunnlaget i landbruket.

Ved søknad om fradeling av eksisterende bolig som er en følge av bruksrasjonaliseringstiltak i landbruket, godkjent etter jordlov og konsesjonslov, kan dispensasjon vurderes. Fradeling av boenheter tilknyttet tunet tillates ikke.

I LNFR-områder legges hensynet til landbruk, natur og allmenn rekreasjon til grunn for kommunens forvaltning. Det tas særlig hensyn til langsiktig forvaltning av natur- og kulturlandskapet.

For endringer på bebygde eiendommer legges det vekt på tiltakets tilpasning på eiendommen og helhetlige kulturlandskapsvurderinger. Nybygg og tilbygg tilknyttet landbruket skal tilpasses eksisterende bygningsmiljø og landskapet.

Ap 4.58. § 26.2 Våningshus for landbruksdrift
Det tillates inntil to våningshus.

Våningshuset bør plasseres i tilknytning til tunet på landbrukseiendommen, og utformes på en slik måte at den blir en naturlig del av det tradisjonelle kulturlandskapet, samt tilpasses eksisterende bygningsmasse når det gjelder takvinkler, materialvalg, farger og stilart.

Våningshuset bør som hovedregel ikke berøre dyrka jord (fulldyrka eller overflatedyrka) jf. digitale markslagskart AR5 (gårdskart) med mindre det ikke finnes andre alternativ.

Ap 4.59. § 26.3 Fritidsbebyggelse
Søknad om oppføring av ny eller utvidelse av bestående fritidsbebyggelse skal vurderes i hvert tilfelle. Det samme gjelder for bruksendring fra fritidsbebyggelse til bolig.

Oppføring av ny eller utvidelse av bestående fritidsbebyggelse, samt bruksendring fra fritidsbebyggelse til bolig, bør som hovedregel ikke tillates.

Ap 4.60. § 27.4 Friluftsområde (6700)
Innenfor områder avsatt til friluftsområde i sjø og vassdrag skal det tas hensyn til ferdsel, rekreasjon, lek og opphold i sjøen. Anlegg, tiltak og aktivitet til ulempe for friluftsliv eller opplevelsesverdi, herunder bruk av motordrevne fartøy, er ikke tillatt. Dette gjelder ikke for

transportkjøring inntil 5 knop for turistbåter med godkjenning og kjøretøy som ivaretar og rutegående transport etter yrkestransportlova, sikkerhetstjenester, eller drift og vedlikehold av friluftsområdene.

Følgende aktiviteter er ikke underlagt fartsbegrensing:
-Forsvarets øvelser, forflytninger og transporter
-Politi-, rednings-, brannverns- og ambulansetjenester, tiltak i forbindelse med akutt forurensning, samt oppsyns- og tilsynstjeneste.

Ap 4.61. § 28.1-.6 Behandling av § 28.1 til §28.6 som omhandler drikkevann
utsettes, og behandles for seg. Inntil nye bestemmelser og retningslinjer om drikkevann er vedtatt av bystyret, gjelder eksisterende bestemmelser.

Ap 4.62. § 28.7.1 Arealbruk
Det tillates boligbebyggelse og annen sårbar bebyggelse i randsone til deponi i de områdene som er svært viktige for byutviklingen og i tråd med byutviklingsstrategien og nullvekstmålet. Bygging av andre formål tillates på og i randsone til deponi.

Ved bygging av sårbar bebyggelse på avfallsdeponi, som for eksempel bolig, barnehage, helsebygg og undervisningsbygg, skal avfallet som hovedregel fjernes under bebyggelsen. Areal der deponimasser er fjernet skal betraktes som ordinær byggetomt eller randsone til deponi.

Utvikling på og ved nedlagte deponier vurderes hver for seg, og det må gjøres nødvendige sikringstiltak som hindrer inntrenging av gass fra deponiet inn i bebyggelse i den enkelte reguleringsplan.

Ved opprydding av gamle avfallsdeponier skal muligheten for ombruk og materialgjenvinning utredes og vurderes. Masser som etter opprydding av deponi ikke utgjør risiko for gassproduksjon eller setninger ved nedbryting kan gjenbrukes som fyllmasse under bebyggelse.

Det vises til Miljødirektoratets veileder "Bygging på nedlagte deponier" for ytterligere krav ved detaljregulering innenfor faresonen.

Nettstasjon tillates ikke plassert i rom under bakkeplan innenfor hensynssonen.

Ap 4.63. § 30.2 Båndlegging i påvente av detaljregulering - Østmarka
(H710_1) - tas ut og stemmer for SH 24 HVS på Østmarka

Ap 4.64. § 30.3 Bestemmelsen strykes

Ap 4.65. § 32.1 Bestemmelsesområde #1, Kaibasert næring
For sentrumsformål i bestemmelsesområdet skal kaikant og dokk, samt behov for næringsbebyggelse og adkomst for tungtransport og store volum ivaretas. Dette må avklares i plan- og reguleringsarbeidet.

Ap 4.66. § 32.3 Bestemmelse område #3 mobilitetshus strykes

Ap 4.67. § 32.8 Bestemmelsesområde #8 og #9, Framtidig godsterminal.
Innenfor områdene #8 på Heggstadmoen og #9 på Torgård skal alle søknader om tiltak etter pbl § 1-6 forelegges jernbanemyndighetene for uttalelse før eventuell tillatelse kan gis.

Roald Arentz (R) fremmet følgende alternative forslag på vegne av R:
1. Bystyret vedtar forslag til ny kommuneplanens arealdel 2022-2034 som vist på kart i målestokk 1:40 000, senest datert 07.05.2024, og med bestemmelser senest datert07.05.2024 og beskrevet i planbeskrivelsen, senest datert 07.05.2024, og med de endringer som følger av bystyrets vedtak.

2. Kommuneplanen gjelder fra det tidspunkt planen er vedtatt av bystyret, og vil da gjelde for alle søknader om tiltak og forslag om regulering, jf. § 11-6. Unntak gis for planforslag som mottas som komplett innen seks måneder etter vedtaket av arealdelen. Planforslaget skal være komplett etter loven og krav gitt i Trondheim kommunes veileder for reguleringsplaner. Unntak forutsetter videre at føringer gitt i kommuneplanens arealdel for Trondheim 2012-2024 eller for Klæbu 2010-2021 følges. En eventuell kombinasjon med føringer fra ny arealdel forutsetter at dette bidrar til bedre bolig- og bykvalitet.

Vedtaket fattes i henhold til plan- og bygningsloven § 11-15.

3. Bystyret vedtar at det gjennomføres ny høring for de områder og bestemmelser som etter dette vedtaket er nødvendig, før de tas opp til endelig sluttbehandling

4. Bystyret vedtar følgende endringer i arealdisponering:
Område 5 og 6 Tillermarka som LNFR
Områdene #5 Håbroen og Kvenild og #6 Løvaas m.fl beholdes som LNFR.
Område 14 Sivert Dahlens veg som LNFR
Område 14, Sivert Dahlens veg, videreføres som LNFR.
Område 25 Nergeilan beholdes som LNFR
Område 25 beholdes som LNFR.
Område 35 Leirfossvegen videreføre som næring
Område 35 Leirfossvegen videreføres som næring.
Område 40 Vassfjellvegen
Område 40 reguleres slik at all skog reguleres til LNFR og at området for næring kun gjelder nåværende grustatak.
Område 45 Skjøla utvidelse som LNFR med hensynssone
Område 45 beholdes som LNFR og pålegges hensynssone for sikring av mineralressurser.
Område 47 Løkaunet beholdes som LNFR
Område 47 Løkaunet beholdes som LNFR.
Område 49 Nordset som LNFR
Område 49 Nordset beholdes som LNFR.
Område 56 Fossegrenda senter videreføres som næring.
Område 56 Fossegrenda senter videreføres som næring.
Område 59 Heimdal/Perslia beholdes som grønnstruktur og tjenesteyting
Område 59 Heimdal/Perslia beholdes som grønnstruktur og tjenesteyting.
Område 74, 92 og 96 Torgård beholdes som LNFR og råstoffutvinning
Torgård-områdene #74, #92 og #96 beholdes som LNFR og råstoffutvinning.
Område 75: Stokkanhaugen videreføre som LNFR
Område 75 Stokkanhaugen videreføres som LNFR.
Område 79 og 623 Gjervan gård videreføre som LNFR
område 79 og 623 Gjervan gård videreføres som LNFR.
Område 88 Prestegårdsveien 74 beholdes som LNFR
Område 88 Prestegårdsveien 74 beholdes i sin helhet som LNFR.
Område 98 Lia pukkverk som LNFR med hensynssone
Område 98 Lia pukkverk beholdes som LNFR og pålegges eksisterende råstoffutvinning med

hensynssone for sikring av mineralressurser.
Område 124 Gamle Ladejarlen vgs beholdes som tjenesteyting
Område 124 Gamle Ladejarlen vgs beholdes som tjenesteyting.
Område 125 (del av område 406) Gamle Heimdal vgs beholdes som tjenesteyting
Område 125 Gamle Heimdal vgs beholdes som tjenesteyting.
Område 140 Bromstadvegen 57 videreføre som næring
Område 140 Bromstadvegen 57 videreføre som næring.
Gnr/bnr 314/4 reguleres til LNFR
Gårdsnummer gnr/bnr 314/4 reguleres til LNFR og plasseres bak grønn strek.
Område 401 HVS på Nyhavna
Det avsettes areal for tjenesteyting (HVS) innenfor KDP Nyhavnas område 4 og 8 (inkluderes i bestemmelsesområde #6).
Område 403 og 942, Valøya
Område 403 og 942 avsettes til framtidig idrettsanlegg, framtidig tjenesteyting (skole og kommunalteknisk anlegg) og blå/grønnstruktur.
Område 602 Tanemsmyra hele området som LNFR
Område 602 Tanemsmyra; hele området reguleres til LNFR.
Område 619 Grånåsen myr, hele som LNFR
Hele område 619, inklusive de fire nordlige feltene, beholdes som LNFR.
Område 620 Litlgråkallen (myr), hele som LNFR
Hele område 620 Litlgråkallen beholdes som LNFR.
Område 622 Digresmyra (myr), hele som LNFR
Hele område 622 Digresmyra beholdes som LNFR.
Område 623 Refset-Hatkallåsen forblir LNFR
Område 623 Refset-Hatkallåsen beholdes som LNFR.
Område 625 Forset øvre (myr), bevar de to vestlige/sørvestlige områdene som LNFR
De to vestlige områdene beholdes som LNFR.
Område 626 Stamsåsen viderføre hele området som LNFR
Område 626 Stamsåsen hele området videreføres som LNFR
Område 864 Kvenild som LNFR
Område 862 Kvenild reguleres til LNFR.
Område 872 Lysklett som LNFR
Område 872 Lysklett reguleres til LNFR.
Område 911 Øvre Rotvoll som LNFR
Område 911 Øvre Rotvoll reguleres til LNFR.
Område 912 abc Rotvolltrekanten: Båndlegging fjernes og reguleres til LNFR
Område 912 abc Rotvolltrekanten: Båndlegging fjernes og området reguleres til LNFR.
Område 918 Tempe videreføre som næring
Område 918 Tempe videreføres som næring.
Område 921 Wullumsgården forblir LNFR
Område 921 Wullumsgården beholdes som LNFR.
Område 932 HVS på Brøset
Det avsettes areal for tjenesteyting (HVS) på Brøset (område 932). Inkluderes i bestemmelseområde #6.
Område 937 og tilgrensende tomter gjøres til blågrønnstruktur:
Østmarka (gnr/bnr 413/56 og 57, 413/59-62, 413/124, 413/168 og 169 og 413/177) inkluderes i den sammenhengende blågrønnstrukturen på Ladehalvøya.
Område 944 Tanemsflata til LNFR
Område 944 Tanemsflata reguleres til LNFR.

Område 946 Granås øst som LNFR
Område 946 Granås øst reguleres til LNFR.
Område 950 Tjenesteyting på NGU-tomta
Område 950, NGU-tomta på Østmarka, gnr/bnr 413/21, reguleres til offentlig tjenesteyting.
Område 951a Nyhavna
Område 951a Delområdene på Nyhavna som er behandla i høringsutkast 951a avsettes til havneformål.
Område 970 Furuhaugen som LNFR
Område 970 Furuhaugen beholdes som LNFR.
Område på Byåsen til byggesone 3
Området på Byåsen mellom Bygrensa, Åsveien skole og Breidablikk
reguleres til byggesone 3.
Bratsbergveien 110 (Sorgenfri bussdepot) som næringsbebyggelse
Bratsbergveien 110 (Sorgenfri bussdepot) reguleres som næringsbebyggelse

5. Bystyret vedtar følgende endringer og tillegg i bestemmelsene:
§ 4.2
§ 4.2 Stryk rekkefølgekrav om fritak fra skolekapasitet i byggesone 1.

§9.3 Hensynssoner kulturmiljø forfall
Legge til i §9.3: Ved forfall og/eller brann tillates kun gjenoppføring av bygg innenfor samme volum og høyde.

§30.3 Presthusjordet og Øvre Rotvoll båndleggingssone fjernes
Båndleggingssone i påvente av detaljregulering for Øvre Rotvoll og Presthus iht § 30.3, fjernes, og områdene plasseres bak grønn strek.

Framtidige reguleringsplaner sammenlignes opp mot arkitekturstrategien
Når reguleringsplaner legges fram til politisk behandling, skal det synliggjøres i saksframlegget hvordan reguleringsplanen svarer på arkitekturstrategien.Område 911 Øvre Rotvoll reguleres til LNFR.**

Elin Marie Andreassen (FrP) fremmet følgende tilleggsforslag "Utbygging i tråd med områdeplan for Overvik":
Overvik utvikles i tråd med Overvik områdeplan, r20150024.

Elin Marie Andreassen (FrP) fremmet følgende tilleggsforslag "Massedeponi - Lerslia, del av gnr/bnr 215/1, 215/2 m.fl.":
Bystyret viser til detaljregulering av Lerslia, del av gnr/bnr 215/1, 215/2 m.fl., r20150037, sluttbehandling, behandlet og avvist i bystyret 4.2.2021. Bystyret ber om at det på nytt startes en prosess for å sikre at arealene kan benyttes til massedeponi.

Elin Marie Andreassen (FrP) fremmet følgende tilleggsforslag "Høring - Vikingvegen - Byggesone 1 eller 2":
Deler av gnr./bnr. 521/137, Vikingvegen 8 og areal i nord mot Finnmyrvegen, avsettes til byggesone 1 eller 2 etter høring.

Elin Marie Andreassen (FrP) fremmet følgende tilleggsforslag "Høring - Kleivavegen 23 og 25 - Byggesone 3":
For boligeiendommene 80/17 og 80/30 skal ikke omfattes av markagrensa, og avsettes til byggesone 3 etter høring.

Elin Marie Andreassen (FrP) fremmet følgende tilleggsforslag "Høring - Områder avvist ved fastsetting av planprogram":
Områdene #16 - Byneset, Klefstadbakkan, #18 - Bratsberg, Ny Jord-vegen 114, #24 - Klæbu, Eidstutrøa, #27 - Byneset, Nerhovsvegen 169 - Begrenset til del av 248/2, teig i vest, beliggende langs Skolvegen, og #95 - Lund, Øvre Solberg og Lund Vestre skal høres i tråd med opprinnelig innspill til planprogrammet.

Elin Marie Andreassen (FrP) fremmet følgende tilleggsforslag "Høring - Lilleuglen, gnr./bnr. 518/1 - Næringsareal":
Områder øst og vest for Tanemsbruvegen skal høres som fremtidig næringsareal og noe fremtidig jordbruksareal i tråd med innspill fra Adnor Advokat AS.

Elin Marie Andreassen (FrP) fremmet følgende tilleggsforslag "Øvre allé 25 og 27 og Eidsvolls gate 2A":
Eiendommene 406/26, 406/27 og 406/161, Øvre allé 25 og 27 og Eidsvolls gate 2A, klassifiseres ikke, og holdes utenfor hensynssone for Singsaker, inklusive Kristianfeldt.

Elin Marie Andreassen (FrP) fremmet følgende tilleggsforslag "Parkering ved helse- og velferdssentre":
Det må planlegges for et betydelig høyere antall parkeringsplasser for ansatte og pårørende ved bygging av nye helse- og velferdssentre, enn det som er praksis i dag. Alle tall i tabell for Veiledende norm for bilparkering på side 17 i parkeringsveilederen gjøres til minimumskrav.

Elin Marie Andreassen (FrP) fremmet følgende tilleggsforslag "Høring - Justering av markagrensa - Lian og Kystadmarka":
Markagrensa skal justeres, slik at eiendommer omfattet av r20200039, Detaljregulering av Lian og Kystadmarka, kan omdefineres til byggesone 4 uten de restriksjoner som følger av rød strek.

Elin Marie Andreassen (FrP) fremmet følgende tilleggsforslag "Høring - Justering av markagrensa - Strindamarka":
Markagrensa skal justeres, slik at eiendommer langs Estenstadvegen og Kleivavegen kan omdefineres til byggesone 4 uten de restriksjoner som følger av rød strek.

Elin Marie Andreassen (FrP) fremmet følgende tilleggsforslag "Høring - Hensynssone bevaring naturmiljø":
Hensynssone bevaring naturmiljø må følge den blågrønne strukturen, og ikke overlappe byggesonen, eksempelvis på Ladehalvøya.

Elin Marie Andreassen (FrP) fremmet følgende tilleggsforslag "Høring - Solemsvegen 5, gnr/bnr. 109/131":
Solemsvegen 5, gnr/bnr. 109/131 En smal stripe helt sør på eiendommen, som gjennom reguleringsplan for Lian og Kystadmarka er avsatt til friluftsformål, endres til boligformål.

Roar Aas (Ap) fremmet følgende tilleggsforslag "Mer næringsareal":
Deler av område 74 og 96 Brøttemsvegen (Torgård sør) Området reguleres til næringsareal (150 daa).

Elin Marie Andreassen (FrP) fremmet følgende tilleggsforslag "949 Buengveien 1A, Forsøkslia/Buenget":
KU nr. 949 Buengveien 1A, Forsøkslia/Buenget avsettes til byggesone 3.

Kirsti Tømmervold (Ap) fremmet følgende tilleggsforslag "Rullering av KPA":
Bystyret vedtar at Kommuneplanensarealdel blir rullert innen 4 år. Dette er i tråd med plan- og bygningsloven.

Roar Aas (Ap) fremmet følgende tilleggsforslag «Område 912b Rotvolltrekanten»

Hele Rotvolltrekanten får arealformålet kombinert bebyggelse og anlegg og næringsformål Det settes av areal til kollektivanlegg, kommunaltekniske anlegg, energianlegg, energistasjon og renovasjonsanlegg. Det skal legges til rette for næringsareal på resterende areal og over bussdepot, bydrift og energistasjon der dette er mulig.

Roar Aas (Ap) fremmet følgende tilleggsforslag "Leinan (919) Framtidig massedeponi":
Leinan (919) Framtidig massedeponi.

Roar Aas (AP) fremmet følgende tilleggsforslag «Øvre Rotvoll sør (911a) Framtidig næringsbebyggelse»
Øvre Rotvoll sør (911a) Framtidig næringsbebyggelse.

Votering:
Tømmervolds forslag fikk 25 stemmer (17 Ap, 4 FrP, Uavh, 3 R) mot 42 stemmer (19, H, 9 SV, 5 MDG, 4 V, 3 PP, KrF, SP) og falt.
Innstillingen fikk 4 stemmer (4 H) mot 63 stemmer (15 H, 17 Ap, 9 SV, 5 MDG, 4 FrP, 4 V, 3 R, 3 PP, KrF, Uavh., SP) og falt.
Rødts helhetlige forslag fikk 3 stemmer (3 R) mot 64 stemmer (19 H, 17 Ap, 9 SV, 5 MDG, 4 FrP, 4 V, 3 PP, KrF, Uavh., SP) og falt.
FrPs helhetlige forslag fikk 8 stemmer (4 FrP, 4 H) mot 59 stemmer (15 H, 17 Ap, 9 SV, 5 MDG, 4 V, 3 R, 3 PP, KrF, Uavh., SP) og falt.
Aps helhetlige forslag, "endringer i arealdisponering og byggesoner" fikk 25 stemmer (4 H, 17 Ap, 3 FrP, Uavh.) mot 42 stemmer (15 H, 9 SV, 5 MDG, 1 FrP, 4 V, 3 R, 3 PP, KrF, SP) og falt.
Aps helhetlige forslag, "endringer i bestemmelser" fikk 22 stemmer (4 H, 17 Ap, Uavh.) mot 45 stemmer (15 H, 9 SV, 5 MDG, 4 FrP, 4 V, 3 R, 3 PP, KrF, SP) og falt.
Høyres "helhetlige forslag "KPA Sentrum - Høyre og SV" fikk 38 stemmer (15 H, 9 SV, 5 MDG, 4 V, 3 PP, KrF, SP) mot 29 stemmer (4 H, 17 Ap, 4 FrP, 3 R, Uavh.) og ble vedtatt.
Ness Bergsengs tilleggsforslag "Område 912 og 911 Øvre Rotvoll reguleres til LNFR og legges bak grønn strek" fikk 12 stemmer (9 SV, 3 R) mot 55 stemmer (19 H, 17 Ap, 5 MDG, 4 FrP, 4 V, 3 PP, KrF, Uavh., SP) og falt
Aas tilleggsforslag "Øvre Rotvoll sør (911a) Framtidig næringsbebyggelse" fikk 55 stemmer (19 H, 17 Ap, 5 MDG, 4 FrP, 4 V, 3 PP, KrF, Uavh., SP) mot 12 stemmer (9 SV, 3 R) og ble vedtatt.
Aas tilleggsforslag "område 912b Rotvolltrekanten" fikk 55 stemmer (19 H, 17 Ap, 5 MDG, 4 FrP, 4 V, KrF, Uavh., SP) mot 12 stemmer (9 SV, 3 R) og ble vedtatt.
Andreassen tilleggsforslag "Utbygging i tråd med områdeplan for Overvik" fikk 25 stemmer (4 H, 17 Ap, 4 FrP) mot 42 stemmer (15 stemmer, 9 SV, 5 MDG, 4 V, 3 R, 3 PP, KrF, Uavh., SP) og falt.
Andreassen tilleggsforslag "Massedeponi - Lerslia, del av gnr/bnr 215/1, 215/2 m,fl, fikk 8 stemmer (4 H, 4 FrP) mot 59 stemmer (15 H, 17 Ap, 9 SV, 5 MDG, 4 V, 3 R, 3 PP, KrF, Uavh., SP) og falt.
Andreassen tilleggsforslag "Høring - Vikingvegen - Byggesone 1 eller 2" fikk 27 stemmer (4 H, 17 Ap, 4 FrP, 1 PP, Uavh.) mot 40 stemmer (15 H, 9 SV, 5 MDG, 4 V, 3 R, 2 PPKrF, SP) og falt.
Andreassen tilleggsforslag "Høring - Kleivavegen 23 og 25 - Byggesone 3" fikk 26 stemmer (4 H, 17 Ap, 4 FrP, Uavh.) mot 41 stemmer (15 H, 9 SV, 5 MDG, 4 V, 3 R, KrF, SP) og falt.
Andreassen tilleggsforslag "Høring - Områder avvist ved fastsetting av planprogram" fikk 9 stemmer (4 H, 4 FrP, Uavh.) mot 58 stemmer (15 H, 17 Ap, 9 SV, 5 MDG, 4 V, 3 R, 3 PP, KrF, SP) og falt.

Andreassen tilleggsforslag "Høring - Lilleuglen, gnr./bnr. 518/1 - Næringsareal" fikk 25 stemmer (4 H, 17 Ap, 4 FrP) mot 42 stemmer (15 H, 9 SV, 5 MDG, 4 V, 3 R, 3 PP, KrF, Uavh., SP) og falt.
Andreassen tilleggsforslag "Øvre allé 25 og 27 og Eidsvolls gate 2A" fikk 8 stemmer (4 H, 4 FrP) mot 59 stemmer (15 H, 17 Ap, 9 SV, 5 MDG, 4 V, 3 R, 3 PP, KrF, Uavh., SP) og falt.
Andreassen tilleggsforslag "Parkering ved helse- og velferdssentre" fikk 27 stemmer (4 H, 17 Ap, 4 FrP, 1 R, Uavh.) mot 40 stemmer (15 H, 9 SV, 5 MDG, 4 V, 2 R, 3 PP, KrF, SP) og falt.
Andreassen tilleggsforslag "Justering av markagrensa - Lian og Kystadmarka" fikk 8 stemmer (4 H, 4 FrP) mot 59 stemmer (15 H, 17 Ap, 9 SV, 5 MDG, 4 V, 3 R, 3 PP, KrF, Uavh., SP) og falt.
Andreassen tilleggsforslag "Høring - Justering av markagrensa - Strindamarka" fikk 8 stemmer (4 H, 4 FrP) mot 59 stemmer (15 H, 17 Ap, 9 SV, 5 MDG, 4 V, 3 R, 3 PP, KrF, Uavh., SP) og falt.
Andreassen tilleggsforslag "Høring - Hensynssone bevaring naturmiljø" fikk 26 stemmer (4 H, 17 Ap, 4 FrP, Uavh.) mot 41 stemmer (15 H, 9 SV, 5 MDG, 4 V, 3 R, 3 PP, KrF, SP) og falt.
Andreassen tilleggsforslag "Høring - Solemsvegen 5, gnr/bnr. 109/13" fikk 8 stemmer (4 H, 4 FrP) mot 59 stemmer (15 H, 17 Ap, 9 SV, 5 MDG, 4 V, 3 R, 3 PP, KrF, Uavh., SP) og falt.
Aas tilleggsforslag "Mer næringsareal under forusettning av at torgård blir skrinlagt" fikk 25 stemmer (4 H, 17 Ap, 4 FrP) mot 42 stemmer (15 H, 9 SV, 5 MDG, 4 V, 3 R, 3 PP, KrF, Uavh., SP) og falt.
Andreassen tilleggsforslag "949 Buengveien 1A, Forsøkslia/Buenget" fikk 27 stemmer (4 H, 17 Ap, 4 FrP, R, Uavh.) mot 40 stemmer (15 H, 9 SV, 5 MDG, 4 V, 2 R, 3 PP, KrF, SP) og falt.
Tømmervolds tilleggsforslag "Rullering av KPA" fikk 26 stemmer (4 H, 17 Ap, 4 FrP, Uavh.) mot 41 stemmer (15 H, 9 SV, 5 MDG, 4 V, 3 R, KrF, SP) og falt.
Aas tilleggsforslag "Leinan (919) Framtidig massedeponi" fikk 26 stemmer (4 H, 17 Ap, 4 FrP, Uavh.) mot 41 stemmer (15 H, 9 SV, 5 MDG, 4 V, 3 R, 3 PP, KrF, SP) og falt.

PS 170/2024 Årsrapport 2023 - Ombud for helse, omsorg og oppvekst

Bystyrets behandling i møte den 26.09.2024:

Vedtak:
Saken ble utsatt i bystyrets møte 26. september 2024.

Behandling:
Votering:
Saken ble enstemmig vedtatt utsatt.

PS 171/2024 Retningslinjer for forfall

Bystyrets behandling i møte den 26.09.2024:

Vedtak:
Saken ble utsatt i bystyrets møte 26. september 2024.

Behandling:

PS 172/2024 Representantforslag - Innføre en sømløs og vedtaksfri "omsorgstrapp" for personer med ALS - Tone Dorthe Sletten (H)

Bystyrets behandling i møte den 26.09.2024:

Vedtak:
Saken ble utsatt i bystyrets møte 26. september 2024.

Behandling:
Votering:
Saken ble enstemmig vedtatt utsatt.

PS 173/2024 Fritakssøknad og oppnevninger for Høyre

Bystyrets behandling i møte den 26.09.2024:

Vedtak:
1.Bystyret gir Stine Hostad rett til å tre ut av følgende verv for resten av perioden: Medlem i Nordenfjeldske kunstindustrimuseum
Varamedlem i styret i Trondheim kunstmuseum.
Bystyret stadfester bystyrevedtak i sak 167/2024 om oppnevning av Karl Erik Haug i disse vervene.

2. Bystyret oppnevner Sebastian Johansen (H) som settemedlem for Christianne Bauck-Larssen i finans- og organisasjonsutvalget.

Behandling:
Votering:
Innstillingen ble enstemmig vedtatt.

FO 45/2024 Muntlige spørsmål bystyret 26.09.2024

Bystyrets behandling i møte den 26.09.2024:

Vedtak:

Behandling:
1) Sigurd Jan Ingvaldsen (Ap) spurte om "Sammenslåing av Helseplattformen og HEMIT". Byråd Kjetil Reinskou svarte.

2) Mona Berger (SV) spurte om "spørsmål om fremdrift i etablering av brukerrom for personer med rusmiddelavhengighet ". Byråd Christiane Bauck Larssen svarte.

3) Elin Marie Andreassen (FrP) spurte om "Klassebilde - hvordan går det med deg nå?" Byråd Lucie Katrine Eidem svarte.

4) Guro Holm Skillingstad (V) spurte om "Fastlege for studenter i Trondheim". Byråd Merete Ranum svarte.

5) Majen Helen Sævik (KrF) spurte om "Implementering av ny kunnskap om lekens betydning i skolen. Byråd Lucie Katrine Eidem svarte.

6) Kirsti Tømmervold (Ap) spurte om "Tilrettegging for frivillige lag og organisasjoner i Klæbu rådhus". Byråd Kjetil Reinskou svarte.

7) Ottar Michelsen (SV) spurte om "Valgfrihet for familier ved bruk av plass i SFO". Byråd Lucie Katrine Eidem svarte.

FO 46/2024 Medlemsforslag - Base for hjemmetjeneste ved Vår Frue Menighets Omsorgsboliger - Maria Alseth (FrP)

Bystyrets behandling i møte den 26.09.2024:

Vedtak:
Bystyret vedtar at medlemsforslaget oversendes helse- og velferdsutvalget for innstilling til bystyret.

Behandling:
Maria Alseth (FrP) fremmet følgende alternative forslag:
Bystyret vedtar at medlemsforslaget oversendes helse- og velferdsutvalget for innstilling til

bystyret.

Votering:
Ved alternativ votering mellom innstillingen og Alseths forslag ble innstilingen avvist med 32 stemmer (19 H, 5 MDG, 4 V, 3 PP, 1 SP) mot 35 stemmer /17 Ap, 9 SV, 4 FrP, 3 R, KrF, Uavh.)

FO 47/2024 Medlemsforslag - Innkjøpsstopp for Tesla så lenge arbeidskonflikt pågår - Roald Arentz (R)

Bystyrets behandling i møte den 26.09.2024:

Vedtak:
Bystyret vedtar at medlemsforslaget oversendes finans- og organisasjonsutvalget for innstilling til bystyret

Behandling:
Elin Marie Andreassen (FrP) fremmet følgende alternative forslag:
Bystyret vedtar at medlemsforslaget avvises.

Votering:
Ved alternativ votering mellom innstillingen og Andreassens forslag ble

innstillingen vedtatt med 63 stemmer (19 H, 17 Ap, 9 SV, 5 MDG, 4 V, 3 R, 3 PP, KrF, Uavh. SP) mot 4 stemmer (FrP).

FO 48/2024 Medlemsforslag - Samarbeid for å etablere hjelpetiltak for etterlatte ved overdose - og andre rusrelaterte dødsfall - Mona Berger (SV)

Bystyrets behandling i møte den 26.09.2024:

Vedtak:
Bystyret vedtar at medlemsforslaget oversendes helse- og velferdsutvalget for innstilling til bystyret

Behandling:
Ferhat Güven fremmet følgende forslag:
Bystyret vedtar at forslaget avvises, siden oppgaven anses ivaretatt i kommunens eksisterende arbeid og samarbeid.

Votering:
Ved alternativ votering mellom Güvens forslag og innstillingen ble innstillingen vedtatt med 47 stemmer (17 Ap, 9 SV, 5 MDG, 4 FrP, 4 V, 3 R, 2 PP, KrF, Uavh., SP) mot 20 stemmer (19 H, PP).

FO 49/2024 Medlemsforslag - Heve bompengesatsen for nye fossilbiler fra 2025 - Jenny Nordaune (SV) og Even Næss Bergseng (SV)

Bystyrets behandling i møte den 26.09.2024:

Vedtak:
Bystyret vedtar at medlemsforslaget oversendes byrådet for utredning og videre behandling i sammenheng med framtidig høring på ny bompengeinnretning.

Behandling:
Elin Marie Andreassen (FrP) fremmet følgende alternative forslag:
Bystyret vedtar at medlemsforslaget avvises.

Jenny Nordaune (SV) fremmet følgende alternative forslag:
Bystyret vedtar at medlemsforslaget oversendes til miljø, næring og samferdselsutvalget som innstiller til bystyret.

Votering:
Andreassens forslag fikk 8 stemmer (1 Ap, 4 FrP, KrF, Uavh., SP) mot 58 stemmer (19 H, 15 Ap, 9 SV, 5 MDG, 4 V, 3 R, 3 PP) og falt.
Nordaunes forslag fikk 12 stemmer (9 SV, 3 R) mot 54 stemmer (19 H, 16 Ap, 5 MDG, 4 FrP, 4 V, 3 PP, KrF,Uavh., SP) og falt.
Insntillingen fikk 60 stemmer (19 H, 15 Ap, 9 SV, 5 MDG, 4 V, 3 R, 3 PP, KrF, SP) mot 6 stemmer (1 Ap, 4 FrP, Uavh.) og ble vedtatt.

FO 50/2024 Medlemsforslag - egne avdelinger for åndsfriske på sykehjem - Lise Julianne Sandvik (PP)

Bystyrets behandling i møte den 26.09.2024:

Vedtak:
Bystyret viser til vedtak i formannskapet, sak 259/22 og anser medlemsforslaget som behandlet.

Behandling:
Votering:
Innstillingen ble enstemmig vedtatt.

FO 51/2024 Medlemsforslag - Språkpolitisk plan i Trondheim kommune - Annbjørg Horgar (SV)

Bystyrets behandling i møte den 26.09.2024:

Vedtak:
Bystyret vedtar at medlemsforslaget oversendes byrådet for utredning og videre behandling i sammenheng med kommende planstrategi.

Behandling:
Votering:
Innstillingen ble enstemmig vedtatt.

FO 52/2024 Medlemsforslag - Flere skolehager i Trondheim - Vegard Frøseth Fenes (SP)

Bystyrets behandling i møte den 26.09.2024:

Vedtak:
Bystyret vedtar at medlemsforslaget oversendes byrådet for utredning og videre behandling i sammenheng med kommende sak om klimatilskudd.

Behandling:
Elin Marie Andreassen (FrP) fremmet følgende alternative forslag:
Bystyret vedtar at medlemsforslaget avvises.

Votering:
Ved alternativ votering mellom innstillingen og Andreassens forslag ble innstillingen vedtatt med 63 stemmer (19 H, 17 Ap, 9 SV, 5 MDG, 4 V, 3 R, 3 PP, KrF, Uavh. SP) mot 4 stemmer (4 FrP).

FO 53/2024 Interpellasjon - Interpellasjon om likeverdige helsetjenester - Annbjørg Horgar (SV)

Bystyrets behandling i møte den 26.09.2024:

Vedtak:
Saken ble utsatt i bystyrets møte 26. september 2024.

Behandling:

PS 174/2024 Valg til politiske organer etter innføring av parlamentarisme - settevalg og nyvalg

Bystyrets behandling i møte den 26.09.2024:

Vedtak:
Navneforslag:
1. Bystyret oppnevner følgende settemedlemmer for den perioden medlemmer er byråd eller byrådssekretær.
17.mai-utvalget 2023 - 27 Medlem:
Lise Andersen Wiseth (H)

Kulturpriskomite 2023 - 27
Medlem: Erling Moe (V)

Representantskapet i Trondheim Havn IKS 2023 -27
Representant: Aurora Meland Winger (MDG)
Vararepresentant: Guro Holm Skillingstad (V)
Vararepresentant: Jonas Ali Ghanizadeh (MDG)

Representantskapet TBRT IKS 2023 - 27
Representant: Nora Malini Sætherhø (MDG)
Vararepresentant: Jonas Ali Ghanizadeh (MDG)

Samenes nasjonaldag - komite 2024 - 27
Medlem: Marthe Stricert (V)

2. Bystyret oppnevner følgende medlemmer for resten av perioden som følge av at byråder eller byrådssekretærer ihht. Byrådets reglement, og reglement for byrådssekretærer, har gått ut av vervet.

Strinda fjellstyre 2023-27
Varamedlem: Jonas Ali Ghanizadeh (MDG)

Midtbyen Management AS – styret 2023-27
Medlem: Berit Norseth (H)

Partnerskap Atlantbanan 2023-27
Representant: Jonas Ali Ghanizadeh (MDG)

Samarbeidsutvalg (forum) for samferdsel i Midt-Norge 2023-27
Medlem: Nora Malini Sætherhø (MDG) – også arbeidsutvalget

Samarbeidsnettverk Punktum Trondheim Fagnettverk mot vold i nære relasjoner 2023-27
Medlem: Henriette L. Winnberg (SV)

Singsaker studenthjem, rådet 2023-27
Varamedlem: Magnus Gilje (V)

Skoleutvalg Strinda vgs 2023-27
Medlem: Ivar Henry Larsen (MDG)

Trondheimsregionens friluftsråd 2023-27
Vara: Nora Malini Sætherhø (MDG)

Vitensenteret 2023-27
Medlem. Aurora Meland Winger (MDG)

Thonning Owesens legat Stiftelsen Christi Kjærlighet 2023-27
Varamedlem: Jonas Ali Ghanizadeh (MDG)

Thonning Owesens legat for håndgjerningsskole for piker og gutter 2023-27
Varamedlem: Jonas Ali Ghanizadeh (MDG)

Kaare Romulslis legat til kunstnerisk utsmykning 2023 - 27
Medlem: Majen Helen Sævik (KrF)

Behandling:
Berit Tiller (H) fremmet følgende alternative forslag på vegne av H, KrF, MDG, PP, SP, SV, V:
Navneforslag:
1. Bystyret oppnevner følgende settemedlemmer for den perioden medlemmer er byråd eller byrådssekretær.
17.mai-utvalget 2023 - 27 Medlem:
Lise Andersen Wiseth (H)

Kulturpriskomite 2023 - 27

Medlem: Erling Moe (V)

Representantskapet i Trondheim Havn IKS 2023 -27
Representant: Aurora Meland Winger (MDG)
Vararepresentant: Guro Holm Skillingstad (V)
Vararepresentant: Jonas Ali Ghanizadeh (MDG)

Representantskapet TBRT IKS 2023 - 27
Representant: Nora Malini Sætherhø (MDG)
Vararepresentant: Jonas Ali Ghanizadeh (MDG)

Samenes nasjonaldag - komite 2024 - 27
Medlem: Marthe Stricert (V)

2. Bystyret oppnevner følgende medlemmer for resten av perioden som følge av at byråder eller byrådssekretærer ihht. Byrådets reglement, og reglement for byrådssekretærer, har gått ut av vervet.

Strinda fjellstyre 2023-27
Varamedlem: Jonas Ali Ghanizadeh (MDG)

Midtbyen Management AS – styret 2023-27
Medlem: Berit Norseth (H)

Partnerskap Atlantbanan 2023-27
Representant: Jonas Ali Ghanizadeh (MDG)

Samarbeidsutvalg (forum) for samferdsel i Midt-Norge 2023-27
Medlem: Nora Malini Sætherhø (MDG) – også arbeidsutvalget

Samarbeidsnettverk Punktum Trondheim Fagnettverk mot vold i nære relasjoner 2023-27
Medlem: Henriette L. Winnberg (SV)

Singsaker studenthjem, rådet 2023-27
Varamedlem: Magnus Gilje (V)

Skoleutvalg Strinda vgs 2023-27
Medlem: Ivar Henry Larsen (MDG)

Trondheimsregionens friluftsråd 2023-27
Vara: Nora Malini Sætherhø (MDG)

Vitensenteret 2023-27
Medlem. Aurora Meland Winger (MDG)

Thonning Owesens legat Stiftelsen Christi Kjærlighet 2023-27

Varamedlem: Jonas Ali Ghanizadeh (MDG)

Thonning Owesens legat for håndgjerningsskole for piker og gutter 2023-27
Varamedlem: Jonas Ali Ghanizadeh (MDG)

Kaare Romulslis legat til kunstnerisk utsmykning 2023 - 27
Medlem: Majen Helen Sævik (KrF)

Votering:
Tillers forslag ble enstemmig vedtatt.

PS 175/2024 Valg av forliksrådsmedlemmer og møtefullmektiger for forliksrådet for perioden 01.01.2025 - 31.12.2028

Bystyrets behandling i møte den 26.09.2024:

Vedtak:
Faste forliksrådsmedlemmer:
Leder: Åse Åberg (H)
Terje Roel (Ap)
Nora Stein Baustad (SP)

Varamedlemmer:
Jostein Eirik Gjermstad(FrP)
Espen Agøy Hegge (KrF)
Nisrin El Morabit (SV)

Møtefullmektiger:
Anne Sophie Hunstad (Ap)
Gunnar Halstadtrø (H)
Aage Borrmann (Ap)
Bente Dyrseth (H)
Arne Ivar Denstad (KrF)
Urda Brende (H)
Gro Eide (H)
Bjørn Onseid (H)
Haakon Gussiaas (H)
Svein Otto Nilsen (PP)

Behandling:
Berit Tiller (H) fremmet følgende tilleggsforslag på vegne av H, FrP, KrF, MDG, PP, SP V, SV, Ap:
Faste forliksrådsmedlemmer:
Leder: Åse Åberg (H)
Terje Roel (Ap)
Nora Stein Baustad (SP)

Varamedlemmer:
Jostein Eirik Gjermstad(FrP)
Espen Agøy Hegge (KrF)
Nisrin El Morabit (SV)

Møtefullmektiger:
Anne Sophie Hunstad (Ap)
Gunnar Halstadtrø (H)
Aage Borrmann (Ap)
Bente Dyrseth (H)
Arne Ivar Denstad (KrF)
Urda Brende (H)
Gro Eide (H)
Bjørn Onseid (H)
Haakon Gussiaas (H)
Svein Otto Nilsen (PP)

Votering:
Innstillingen ble enstemmig vedtatt.

PS 176/2024 Stavne Arbeid Trondheim KF og Stavne Inkludering Trondheim KF - styret - valg av settemedlem

Bystyrets behandling i møte den 26.09.2024:

Vedtak:
August Grøntvedt Cairns (H), velges som nytt settemedlem. Inge Bjørnbekk rykker opp som nestleder, i perioden hvor Høyre har settemedlem.

Behandling:
Berit Tiller (H) femmet følgende tilleggsforslag på vegne av H, KrF, MDG, PP, SP, V:
August Grøntvedt Cairns (H), velges som nytt settemedlem. Inge Bjørnbekk rykker opp som nestleder, i perioden hvor Høyre har settemedlem.

Votering:
Innstillingen ble enstemmig vedtatt.

PS 177/2024 Trondheim symfoniorkester & opera - oppnevning til valgkomite

Bystyrets behandling i møte den 26.09.2024:

Vedtak:
Ola Lund Renolen velges som medlem i valgkomiteen til Trondheim Symfoniorkester og opera

Behandling:
Votering:
Innstillingen ble enstemmig vedtatt.

PS 178/2024 Navneendring for Rådet for personer med funksjonsnedsettelser

Bystyrets behandling i møte den 26.09.2024:

Vedtak:
Bystyret omgjør sitt tidligere navnevedtak for Rådet for personer med funksjonsnedsettelser, og fjerner tillegget (funkisrådet), fra rådets navn.

Behandling:
Votering:
Innstillingen ble enstemmig vedtatt.